# Bulletin d'estimation du risque d'avalanche

(valable en dehors des pistes balisées et ouvertes)

# MASSIF : Embrunais Parpaillon

Rédigé le samedi 28 mars 2026 à 16h

## Estimation des risques pour le : DIMANCHE 29 MARS

**PLAQUES EN PLACE DANS LA NEIGE RÉCENTE, FORMÉES JEUDI PAR LE VENT DE NORD**

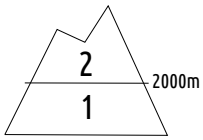


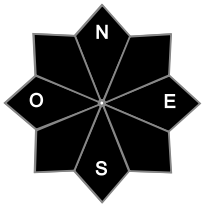


Au-dessus de 2000m indice de risque limité, plus bas indice faible.

**Départs spontanés :** peu probables.

**Déclenchements provoqués :** instabilités superficielles dans la neige ventée, plus épaisses en altitude.

Indices de risque : 5 très fort - 4 fort - 3 marqué - 2 limité - 1 faible -- En noir : les pentes les plus dangereuses

## Stabilité du manteau neigeux

**Situation avalancheuse typique :** neige ventée

**Déclenchements provoqués :** à proximité de l'Ubaye, de rares plaques minces se forment avec les faibles chutes de neige dans la nuit de samedi à dimanche. Elles peuvent être faciles à déclencher par le passage d'un skieur, mais engendrent des avalanches de taille petite uniquement (taille 1).
De plus, des instabilités sont encore en place dans la neige récente ventée. Elles sont présentes en toutes orientations au-dessus de 2000/2200 m environ. Sous forme de plaques dures, elles sont facilement identifiables, localisées même loin des crêtes et ruptures de pente, et encore facilement déclenchables par un seul skieur. Elles génèrent des avalanches de petite taille (taille 1), voire moyenne (taille 2).

**Départs spontanés :** peu probables, quelques boulettes au soleil au fil des éclaircies se développant l'après-midi.

## Qualité de la neige

**L'enneigement** est proche des normales pour une fin mars.
Hauteurs de neige observées : 107 cm à la nivôse du Parpaillon à 2500 m.

**Limite d'enneigement skiable :** au plus bas à 1400/1500 m en ubacs bien protégés ou sur pistes forestières, plutôt 2000/2100 m en adrets.

**État de la neige de surface** : 5/7 cm de neige fraîche légère à proximité de l'Ubaye. Elle repose sur une neige durcie par le vent, localement encore légère dans les secteurs bien abrités. Crêtes parfois décapées. En versant sud, neige croutée sous 2200/2400, s'humidifiant en journée.

## Aperçu météo pour le dimanche 29 mars

| | nuit | matin | après-midi | soir |
|---|---|---|---|---|
| | | | | |
| Faibles chutes de neige dans la nuit de samedi à dimanche. Retour de belles éclaircies en cours de journée. | | | | |
| **Pluie-Neige** | 900 m | | | |
| **Iso 0 °C** | 1 500 m | 1 500 m | 2 000 m | 1 900 m |
| **Vent 2000 m** | ↓ 20 km/h | ↙ 30 km/h | ↘ 25 km/h | ↘ 15 km/h |
| **Vent 3000 m** | ← 25 km/h | ← 40 km/h | ↙ 25 km/h | ↙ 20 km/h |

## Épaisseur de neige hors-piste

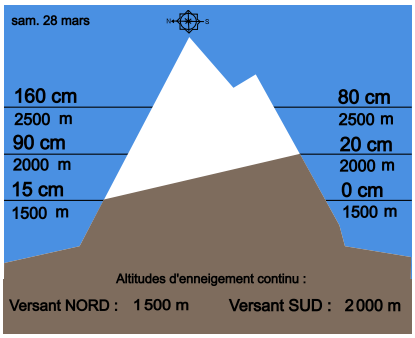


## Précipitations à 1800 m

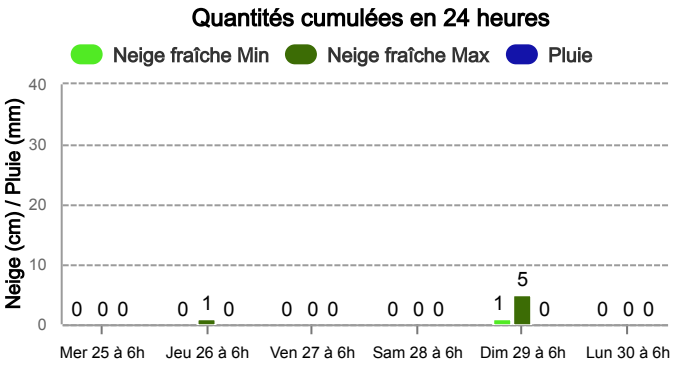


## Tendance du lundi 30 mars

**Indice de risque limité**

Risque en hausse mais restant a priori limité. Formation de nouvelles plaques avec le vent de nord-ouest qui devient tempétueux en montagne au fil de l'après-midi de lundi.

Pour consulter la vigilance en cours, veuillez vous rendre sur le site https://vigilance.meteofrance.fr/fr

Météo-France - 73 avenue de Paris, 94165 Saint-Mandé cedex - Contact : contact@meteo.fr

Rédigé par Météo-France avec la contribution des observateurs du réseau nivo-météorologiques. Partenariat : ANMSM (Maires de Stations de Montagne), DSF (Domaines Skiables de France), ADSP (Directeurs de Pistes et de la Sécurité des Stations de Sports d'Hiver) et autres acteurs de la montagne.

Bulletin neige & avalanches par téléphone au 0 892 68 10 20 Service 0,35 € / min + prix appel

RÉPUBLIQUE FRANÇAISE
*Liberté Égalité Fraternité*

METEO FRANCE
À VOS CÔTÉS, DANS UN CLIMAT QUI CHANGE

# Bulletin d'estimation du risque d'avalanche
## (valable en dehors des pistes balisées et ouvertes)
# MASSIF : Embrunais Parpaillon

Rédigé le samedi 28 mars 2026 à 16h

## Conditions nivo-météo des 7 derniers jours

| | dim. 22/03 | | | | lun. 23/03 | | | | mar. 24/03 | | | | mer. 25/03 | | | | jeu. 26/03 | | | | ven. 27/03 | | | | sam. 28/03 | | | |
|---|---|---|---|---|---|---|---|---|---|---|---|---|---|---|---|---|---|---|---|---|---|---|---|---|---|---|---|---|
| | 03h | 09h | 15h | 21h | 03h | 09h | 15h | 21h | 03h | 09h | 15h | 21h | 03h | 09h | 15h | 21h | 03h | 09h | 15h | 21h | 03h | 09h | 15h | 21h | 03h | 09h | 15h | 21h |
| Météo | | | | | | | | | | | | | | | | | | | | | | | | | | | | |
| Vent (km/h) | 15 | 25 | 30 | 30 | 25 | 25 | 25 | 30 | 25 | 15 | 15 | 15 | 30 | 50 | 60 | 70 | 30 | 60 | 70 | 70 | 50 | 40 | 30 | 10 | 30 | 25 | 30 | 25 |
| à 3000m | | | | | | | | | | | | | | | | | | | | | | | | | | | | |
| Vent (km/h) | 15 | 20 | 25 | 25 | 15 | 15 | 15 | 10 | 10 | 10 | 20 | 5 | 10 | 15 | 50 | 30 | 20 | 50 | 60 | 50 | 45 | 40 | 20 | 10 | 10 | 10 | 20 | 20 |
| à 2000m | | | | | | | | | | | | | | | | | | | | | | | | | | | | |

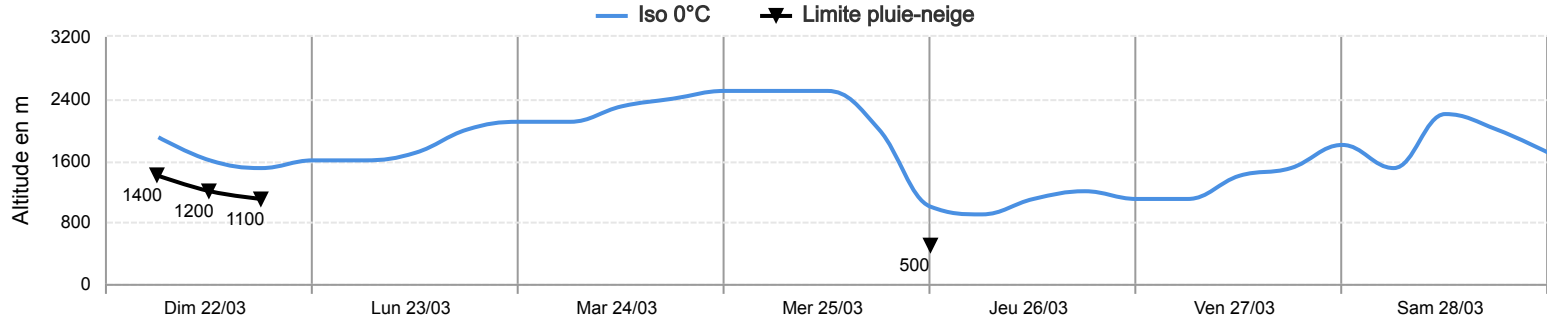


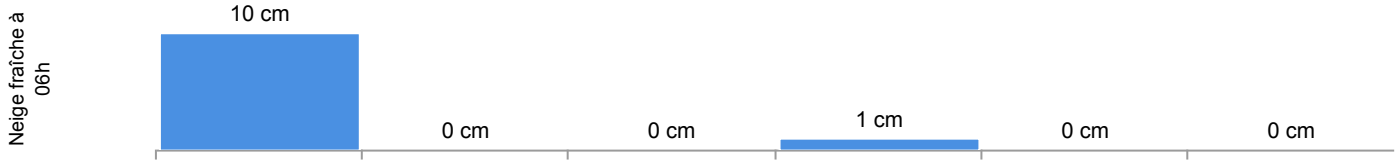


| Risque d'avalanche | dim. 22/03 | lun. 23/03 | mar. 24/03 | mer. 25/03 | jeu. 26/03 | ven. 27/03 | sam. 28/03 |
|---|---|---|---|---|---|---|---|
| | 2 | 2 | 2 | 2 | 3 | 2 | 2 |

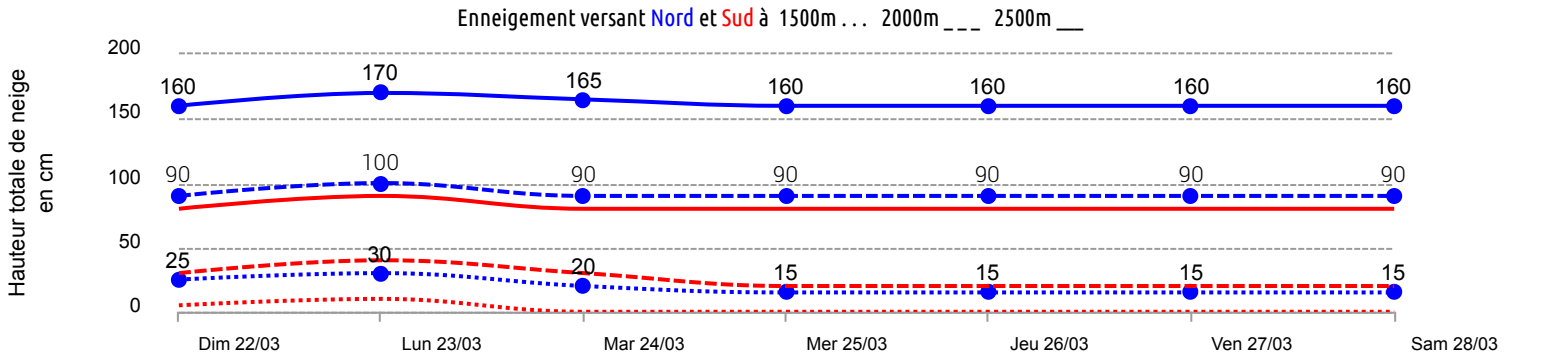


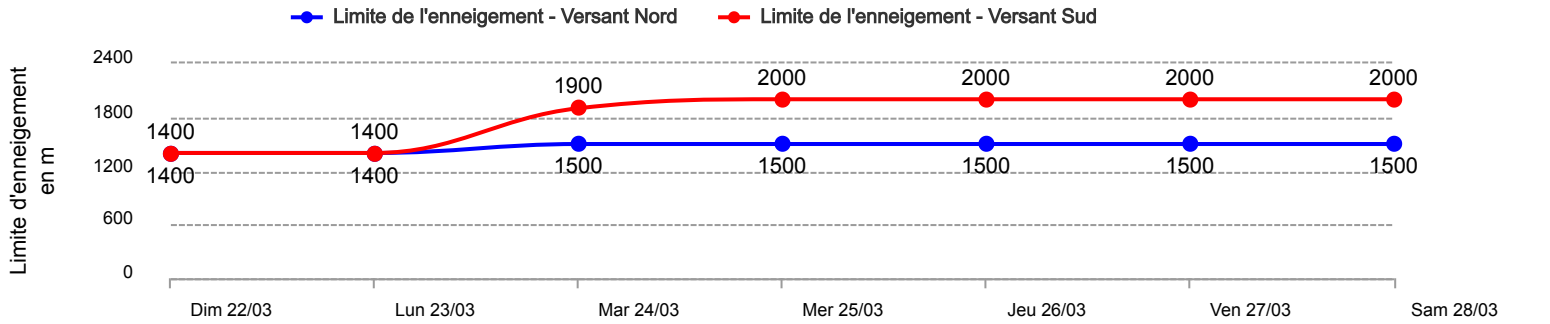


Pour consulter la vigilance en cours, veuillez vous rendre sur le site https://vigilance.meteofrance.fr/fr


Météo-France - 73 avenue de Paris, 94165 Saint-Mandé cedex - Contact : contact@meteo.fr


Bulletin neige & avalanches par téléphone au **0 892 68 10 20** Service 0,35 € / min + prix appel


Rédigé par Météo-France avec la contribution des observateurs du réseau nivo-météorologiques. Partenariat : ANMSM (Maires de Stations de Montagne), DSF (Domaines Skiables de France), ADSP (Directeurs de Pistes et de la Sécurité des Stations de Sports d'Hiver) et autres acteurs de la montagne.