Bulletin d'estimation du risque d'avalanche

(valable en dehors des pistes balisées et ouvertes)

MASSIF : Grandes-Rousses

Rédigé le samedi 28 mars 2026 à 16h

Estimation des risques pour le : DIMANCHE 29 MARS

QUELQUES PLAQUES DANS LA NEIGE VENTÉE.

2

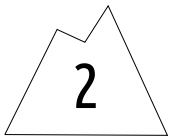

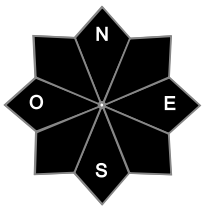

zones d'accumulation

Indices de risque : 5 très fort - 4 fort - 3 marqué - 2 limité - 1 faible -- En noir : les pentes les plus dangereuses

Indice de risque limité.

Départs spontanés : Rares coulées humides au soleil en cas d'éclaircies

Déclenchements provoqués : Quelques plaques dans la neige ventée, parfois loin des crêtes.

Stabilité du manteau neigeux

Situation avalancheuse typique : neige ventée

Déclenchements provoqués : Quelques plaques à vent subsistent ce dimanche, dans les zones d'accumulations formées par le vent de Nord-Nord-Est qui faiblit un peu pour la journée. Elles peuvent être situées loin des crêtes, parfois même en bas de pente. Elles se retrouvent en tout versant, bien que plus fréquemment dans les versants à composante Sud à Est, qui ont été généralement plus chargés. Souvent difficiles à déclencher et d'aspect dur, mais localement il n'est pas exclu qu'elles présentent un aspect un peu plus friable voire poudreux, tout en étant plus réactives au passage d'un pratiquant. La petite couche de neige fraîche attendue jusqu'en début de journée de dimanche (1-5 cm, localement 7 cm à l'ouest du massif) ne vient pas fondamentalement changer la donne, de rares nouvelles petites plaques très peu épaisses mais localement réactives pouvant se former préférentiellement dans ces mêmes zones d'accumulations.

Déclenchements spontanés : Rares coulées humides de taille 1 dans les pentes ensoleillées en cas d'éclaircies en journée, dans la neige fraîche/récente qui peut s'humidifier au soleil et près des rochers.

Qualité de la neige

Qualification de l'enneigement : L'enneigement est bon à basse altitude, et même excellent dés 1800 / 2000m. Peu de sous couche sous 1700m en plein Sud.
Limites skiables : Vers 1000 / 1300m selon le versant, avec prudence en Sud / sous les sapins

Qualité de la neige dimanche : Fine couche de neige fraîche tombant en nuit de samedi à dimanche (jusqu'en journée de dimanche dans certains secteurs de l'ouest du massif), ou à défaut neige récente tombée quelques jours plus tôt et souvent travaillée ou soufflée par le vent dans de nombreux endroits. Le manteau neigeux est parfois très irrégulier. Certaines crêtes et pentes les plus ventées, où la neige a été arrachée, peuvent être dégarnies et le ski se fait parfois sur la vieille croûte de regel. Toutefois, on retrouve des secteurs en neige poudreuse plus agréable, notamment en bas de pentes / dans les arbres. A noter que dans certaines pentes ayant été exposées au soleil, la neige récente s'est parfois humidifiée, on peut alors y retrouver des surfaces croûtées glissantes pouvant être à peine masquées par la petite couche de fraîche.

Aperçu météo pour le dimanche 29 mars

nuit	matin	après-midi	soir

Passage faiblement perturbé en nuit de sam à dim (1 à 5 cm possibles, loc 7 cm à l'ouest du massif).
Vent de NE temporairement en perte de vitesse.

Pluie-Neige	500 m			
Iso 0 °C	900 m	900 m	1 400 m	1 500 m
Vent 2000 m	↙ 40 km/h	↙ 25 km/h	↙ 20 km/h	↙ 20 km/h
Vent 3000 m	↙ 45 km/h	↙ 35 km/h	↙ 25 km/h	↓ 30 km/h

Épaisseur de neige hors-piste

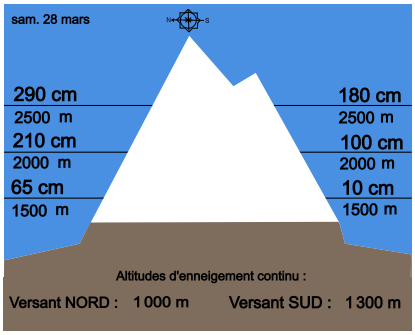

Précipitations à 1800 m

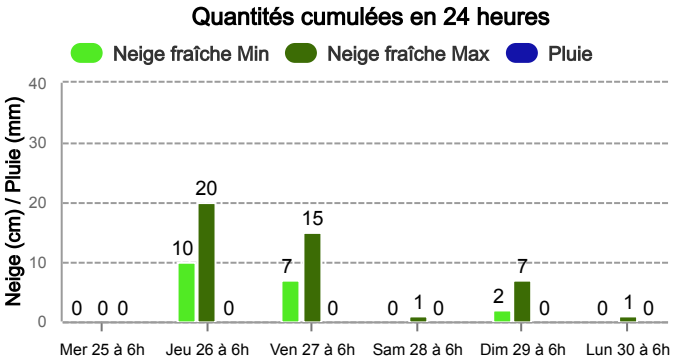

Tendance du lundi 30 mars

3

Indice de risque marqué

Lundi, risque à nouveau en hausse. Le vent de Nord se renforce, créant de nouvelles instabilités dans la neige fraîche/récente. En parallèle, une nouvelle perturbation gagne le massif, donnant un peu de neige surtout à partir de l'après-midi. A confirmer, il reste des incertitudes...

Pour consulter la vigilance en cours, veuillez vous rendre sur le site https://vigilance.meteofrance.fr/fr

Météo-France - 73 avenue de Paris, 94165 Saint-Mandé cedex - Contact : contact@meteo.fr

Rédigé par Météo-France avec la contribution des observateurs du réseau nivo-météorologiques. Partenariat : ANMSM (Maires de Stations de Montagne), DSF (Domaines Skiables de France), ADSP (Directeurs de Pistes et de la Sécurité des Stations de Sports d'Hiver) et autres acteurs de la montagne.

Bulletin neige & avalanches par téléphone au 0 892 68 10 20 Service 0,35 € / min + prix appel

RÉPUBLIQUE FRANÇAISE
Liberté Égalité Fraternité

METEO FRANCE
À VOS CÔTÉS, DANS UN CLIMAT QUI CHANGE

Bulletin d'estimation du risque d'avalanche

(valable en dehors des pistes balisées et ouvertes)

MASSIF : Grandes-Rousses

Rédigé le samedi 28 mars 2026 à 16h

Conditions nivo-météo des 7 derniers jours

	dim. 22/03				lun. 23/03				mar. 24/03				mer. 25/03				jeu. 26/03				ven. 27/03				sam. 28/03			
	03h	09h	15h	21h	03h	09h	15h	21h	03h	09h	15h	21h	03h	09h	15h	21h	03h	09h	15h	21h	03h	09h	15h	21h	03h	09h	15h	21h
Météo																												
Vent (km/h)	15	15	15	10	10	30	25	30	25	15	10	10	25	45	70	100	95	90	90	85	80	60	40	35	50	40	45	35
à 3000m																												
Vent (km/h)	10	5	5	5	5	25	20	15	10	10	10	5	10	20	50	70	70	60	65	60	45	45	30	20	35	35	35	25
à 2000m																												

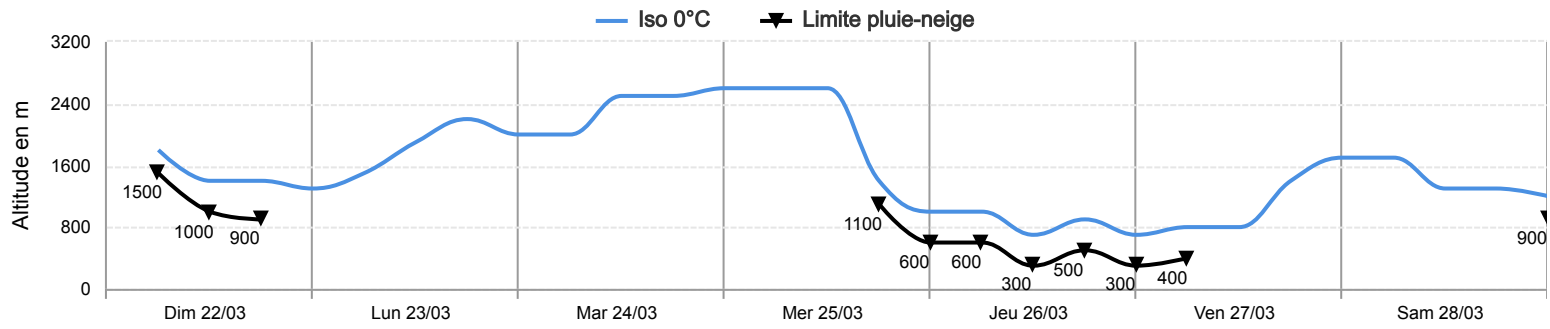

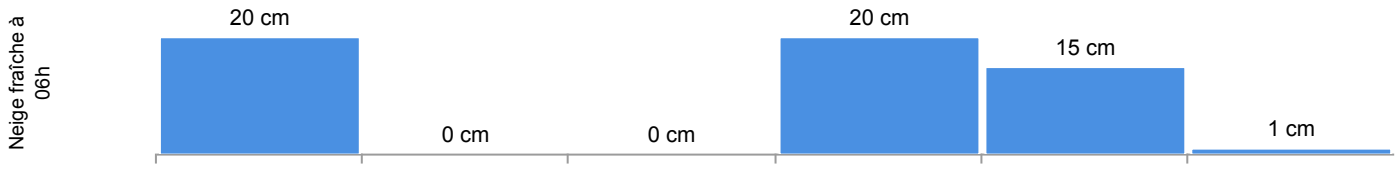

Risque d'avalanche	dim. 22/03	lun. 23/03	mar. 24/03	mer. 25/03	jeu. 26/03	ven. 27/03	sam. 28/03
	2	2	2	3	4	3	2

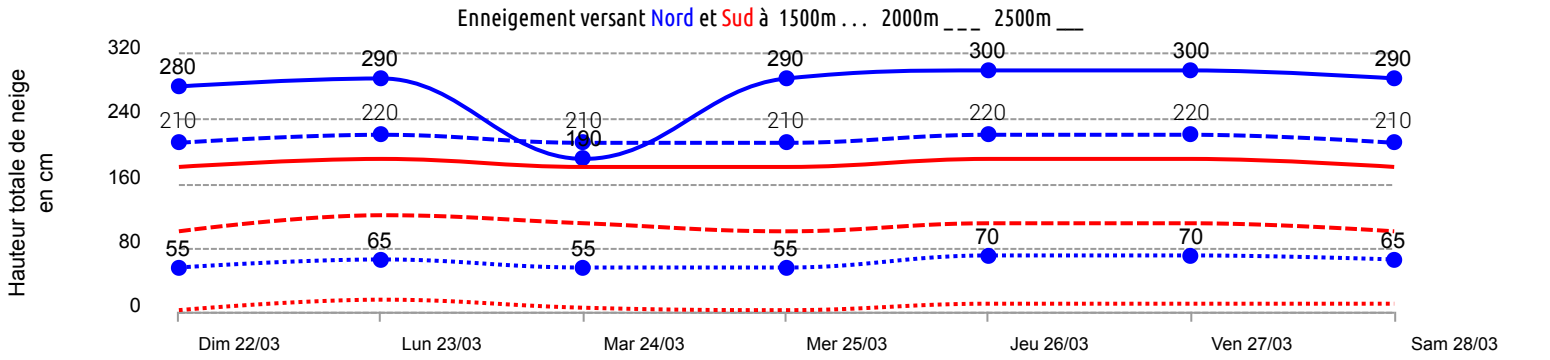

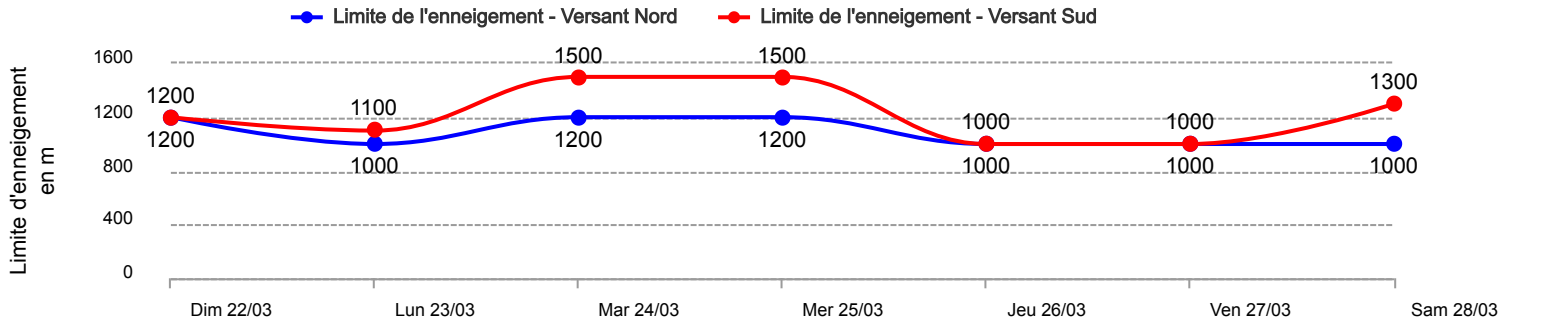

Pour consulter la vigilance en cours, veuillez vous rendre sur le site https://vigilance.meteofrance.fr/fr

Météo-France - 73 avenue de Paris, 94165 Saint-Mandé cedex - Contact : contact@meteo.fr

Rédigé par Météo-France avec la contribution des observateurs du réseau nivo-météorologiques. Partenariat : ANMSM (Maires de Stations de Montagne), DSF (Domaines Skiables de France), ADSP (Directeurs de Pistes et de la Sécurité des Stations de Sports d'Hiver) et autres acteurs de la montagne.

Bulletin neige & avalanches par téléphone au

0 892 68 10 20 Service 0,35 € / min + prix appel