Bulletin d'estimation du risque d'avalanche
(valable en dehors des pistes balisées et ouvertes)

MASSIF : Haut-Var Haut-Verdon

Rédigé le samedi 28 mars 2026 à 16h

Estimation des risques pour le : DIMANCHE 29 MARS

NOUVELLES INSTABILITÉS DE TAILLE LIMITÉE DANS LA NEIGE VENTÉE

2

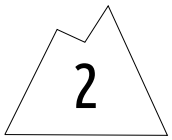

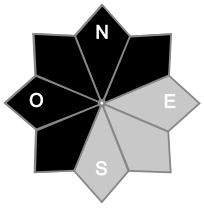

Indice de risque limité.

Départs spontanés : départs ponctuels, voire en plaque, peu fréquents.

Déclenchements provoqués : quelques nouvelles instabilités, faciles à déleclencher mais de taille petite, plus rarement moyenne.

Indices de risque : 5 très fort - 4 fort - 3 marqué - 2 limité - 1 faible -- En noir : les pentes les plus dangereuses

Stabilité du manteau neigeux

Situation avalancheuse typique : neige ventée

Déclenchements provoqués : nouvelles instabilités en formation avec les chutes de neige attendues et le vent. Plaques à vent de taille limitée, plus fréquentes en versants d'altitude de large nord à ouest, même loin de des crêtes et sommets. Elles peuvent céder facilement au passage d'un skieur, mobilisant surtout la neige tombée dans la nuit de samedi à dimanche.

Départs spontanés : en pente raide d'altitude, éventuels départs ponctuels, voire en plaque, avec le transport de la neige par le vent de nord-est à est. Taille petite, plus rarement moyenne.
Dimanche après-midi avec le retour des éclaircies, départs superficiels en pentes raides ensoleillées, près des rochers de la neige fraiche s'humidifiant.

Qualité de la neige

Enneigement plutôt excédentaire dans le Haut-Verdon, proche des normales dans le Haut Var.
Hauteurs de neige observées : vers 2000 m, 182 cm dans le vallon de Valdemars, 119 cm dans le Haut Var.

Enneigement skiable : vers 1400/1500 m en ubacs, 1700/1800 m en adrets peu pentus.

État de la neige en surface : 5/15 cm de neige fraiche reposant sur de la neige souvent regelée / croutée. En ubacs d'altitude, sur de la neige sèche souvent durcie par le vent, plus rarement poudreuse dans les combes abritées.

Aperçu météo pour le dimanche 29 mars

	nuit	matin	après-midi	soir
	5/10 cm de neige, très localement 15 cm pendant la nuit. Vent de nord-est à est sensible surtout le matin. Belles éclaircies l'après-midi.			
Pluie-Neige	1 000 m			
Iso 0 °C	1 500 m	1 500 m	1 800 m	1 800 m
Vent 2000 m	20 km/h	45 km/h	25 km/h	15 km/h
Vent 3000 m	45 km/h	50 km/h	35 km/h	25 km/h

Épaisseur de neige hors-piste

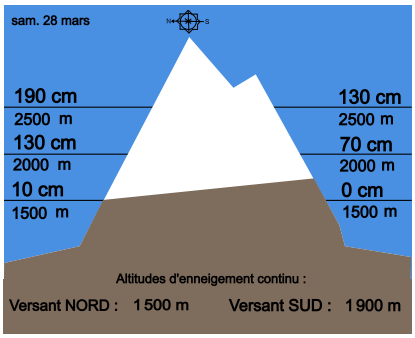

Précipitations à 1800 m

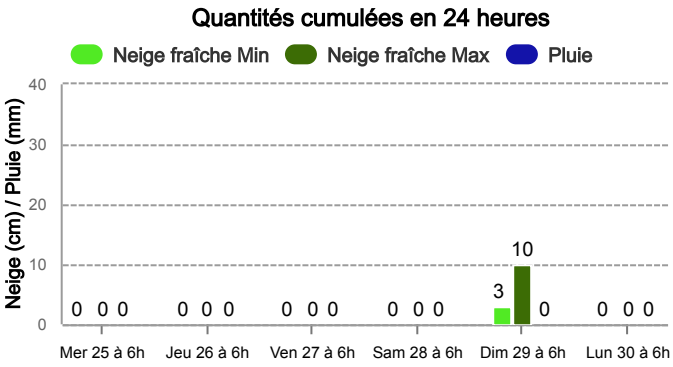

Tendance du lundi 30 mars

2

Indice de risque limité

Risque en hausse mais restant à priori limité. Quelques instabilités localisées, mais de nouvelles en formation en cours de journée de lundi avec le transport de la neige mobilisable par le vent de nord qui devient fort.

Pour consulter la vigilance en cours, veuillez vous rendre sur le site https://vigilance.meteofrance.fr/fr

Météo-France - 73 avenue de Paris, 94165 Saint-Mandé cedex - Contact : contact@meteo.fr

Rédigé par Météo-France avec la contribution des observateurs du réseau nivo-météorologiques. Partenariat : ANMSM (Maires de Stations de Montagne), DSF (Domaines Skiables de France), ADSP (Directeurs de Pistes et de la Sécurité des Stations de Sports d'Hiver) et autres acteurs de la montagne.

Bulletin neige & avalanches par téléphone au
0 892 68 10 20 Service 0,35 € / min + prix appel

Bulletin d'estimation du risque d'avalanche

(valable en dehors des pistes balisées et ouvertes)

MASSIF : Haut-Var Haut-Verdon

Rédigé le samedi 28 mars 2026 à 16h

Conditions nivo-météo des 7 derniers jours

	dim. 22/03				lun. 23/03				mar. 24/03				mer. 25/03				jeu. 26/03				ven. 27/03				sam. 28/03			
	03h	09h	15h	21h	03h	09h	15h	21h	03h	09h	15h	21h	03h	09h	15h	21h	03h	09h	15h	21h	03h	09h	15h	21h	03h	09h	15h	21h
Météo																												
Vent (km/h)	20	20	35	45	40	25	20	25	20	10	15	15	25	40	70	100	100	80	70	60	65	50	40	30	25	25	25	20
à 3000m																												
Vent (km/h)	10	10	25	30	25	15	15	15	10	10	10	10	10	25	55	80	85	65	60	50	45	40	25	15	10	10	20	15
à 2000m																												

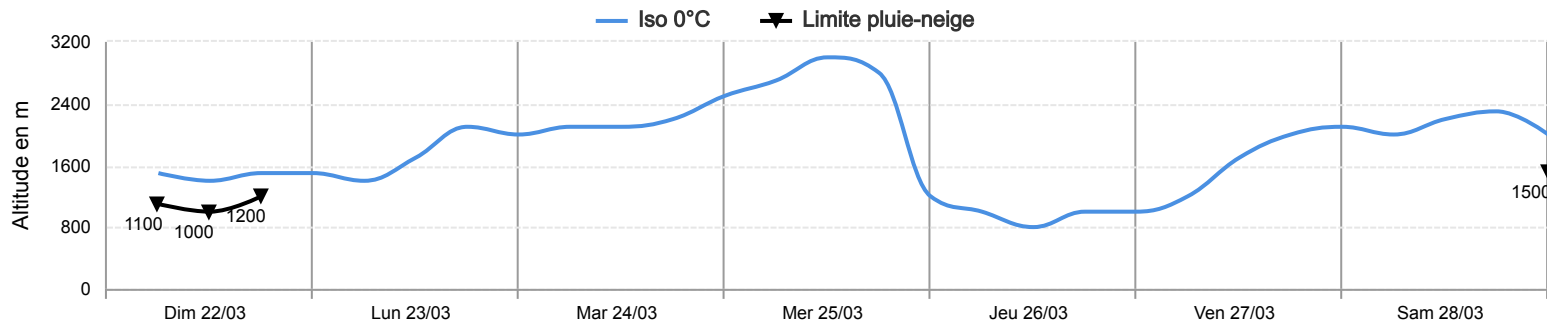

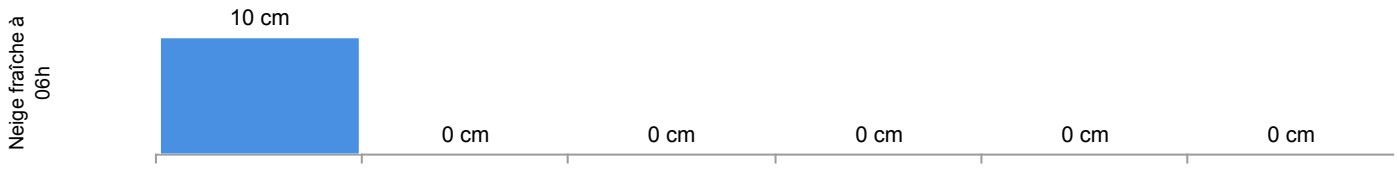

Risque d'avalanche	dim. 22/03	lun. 23/03	mar. 24/03	mer. 25/03	jeu. 26/03	ven. 27/03	sam. 28/03
	3	3	2	2	3	2	2

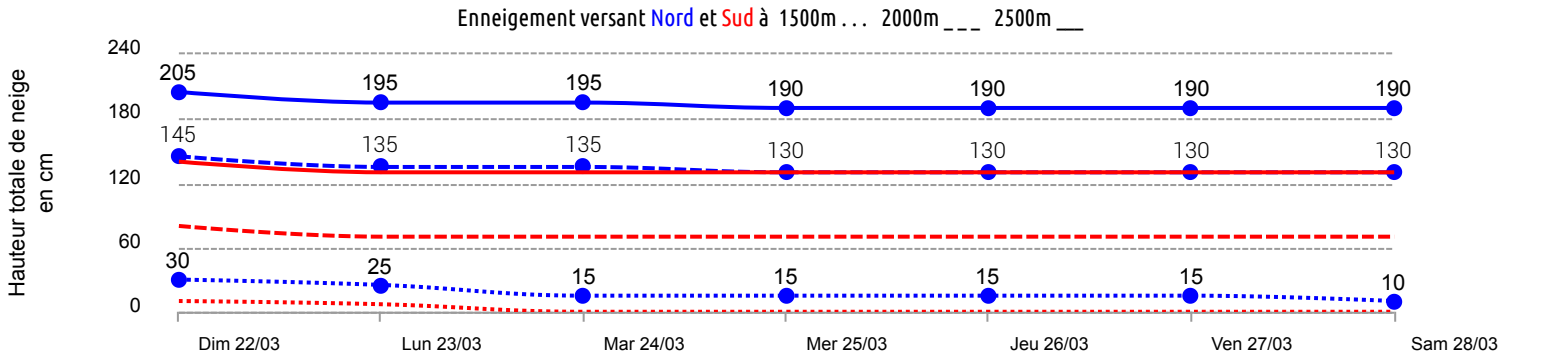

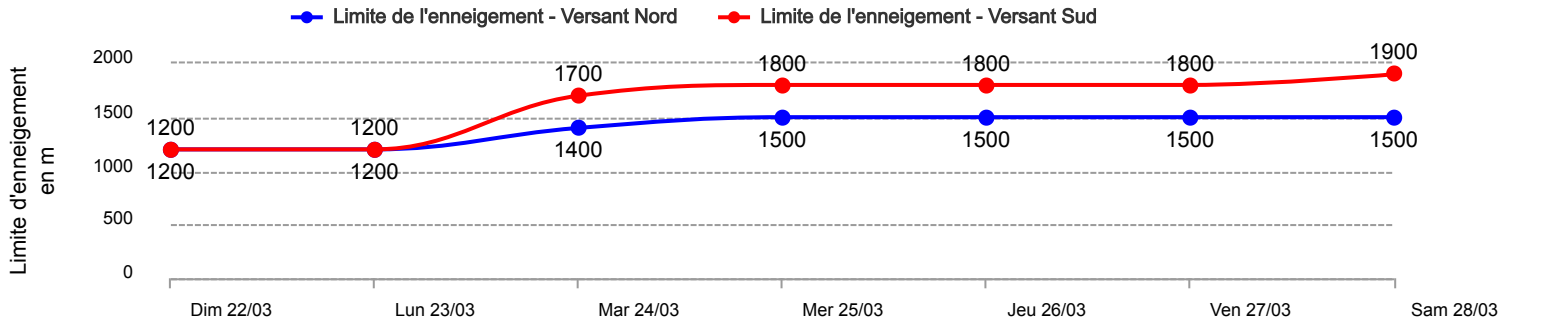

Pour consulter la vigilance en cours, veuillez vous rendre sur le site https://vigilance.meteofrance.fr/fr

Météo-France - 73 avenue de Paris, 94165 Saint-Mandé cedex - Contact : contact@meteo.fr

Bulletin neige & avalanches par téléphone au

0 892 68 10 20 Service 0,35 € / min + prix appel

Rédigé par Météo-France avec la contribution des observateurs du réseau nivo-météorologiques. Partenariat : ANMSM (Maires de Stations de Montagne), DSF (Domaines Skiables de France), ADSP (Directeurs de Pistes et de la Sécurité des Stations de Sports d'Hiver) et autres acteurs de la montagne.