Bulletin d'estimation du risque d'avalanche
(valable en dehors des pistes balisées et ouvertes)

MASSIF : Haute-Maurienne

Rédigé le samedi 28 mars 2026 à 16h

Estimation des risques pour le : DIMANCHE 29 MARS

HIVERNAL. IL TOMBE QUELQUES CENTIMÈTRES DE NEIGE SUR UN MANTEAU TRÈS VENTÉ MAIS PLUTÔT STABLE.

2

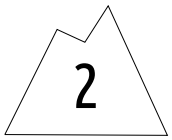

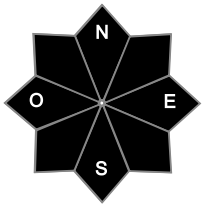

zones d'accumulation

Indices de risque : 5 très fort - 4 fort - 3 marqué - 2 limité - 1 faible -- En noir : les pentes les plus dangereuses

Indice de risque limité.

Départs spontanés : peu probables.

Déclenchements provoqués : quelques plaques en neige ventée, tous versants.

Stabilité du manteau neigeux

Situation avalancheuse typique : neige ventée

Déclenchements provoqués : **quelques plaques** en neige ventée, a priori **surtout dans les orientations sud à est** mais un déclenchement reste possible en tous versants. Ce sont essentiellement d'anciennes plaques datant du coup de vent mercredi-jeudi, plutôt dures, plutôt loin des crêtes, et qui sont désormais peu réactives au passage d'un skieur. La neige fraîche qui tombe dans la nuit ne devrait pas créer d'instabilités supplémentaires car les cumuls sont très faibles (souvent < 5 cm). Par contre, cette fine couche aura pour effet de masquer la plupart des indices visuels, compliquant l'identification des anciennes plaques. **Cassures 20-40 cm**, petites à moyennes avalanches.
Observables peu nombreux : fissures sous les skis...

Départs spontanés : peu probables.

Qualité de la neige

Enneigement : encore un peu au dessus de la moyenne, sauf aux plus basses altitudes où les hauteurs de neige sont tout juste correctes pour la saison.

Limite skiable : avec la petite chute de la nuit, il sera possible de skier dès 1000/1200 m dans les prairies. Sous-couche vers 1300 m en Nord, 1600 m en Sud.

Qualité de la neige : 1-5 cm de neige fraîche ce dimanche matin, voire localement un peu plus dans les zones d'accumulation en altitude. Neige poudreuse, légère, sur un fond généralement bien plus ferme : ski agréable. Se méfier des cailloux sur les crêtes/croupes d'altitude, bien souvent pelées et juste recouvertes de ce saupoudrage, notamment versant nord.
Grâce aux nuages et à la masse d'air froide, la neige reste légère en tous versants et quasiment à toutes les altitudes.

Aperçu météo pour le dimanche 29 mars

	nuit	matin	après-midi	soir

Temps hivernal avec encore quelques flocons à basse altitude le matin. Éclaircies en journée, notamment vers la frontière avec l'Italie.

Pluie-Neige	800 m	500 m		
Iso 0 °C	1 100 m	900 m	1 400 m	1 500 m
Vent 2500 m	↘ 20 km/h	↘ 20 km/h	↘ 20 km/h	↘ 20 km/h
Vent 3500 m	↓ 30 km/h	↓ 30 km/h	↓ 30 km/h	↓ 30 km/h

Épaisseur de neige hors-piste

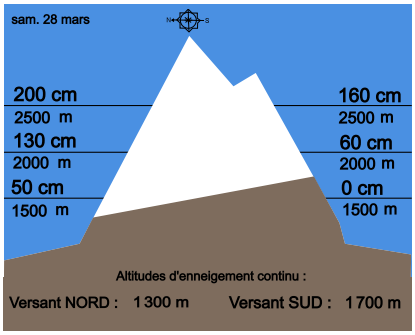

Précipitations à 1800 m

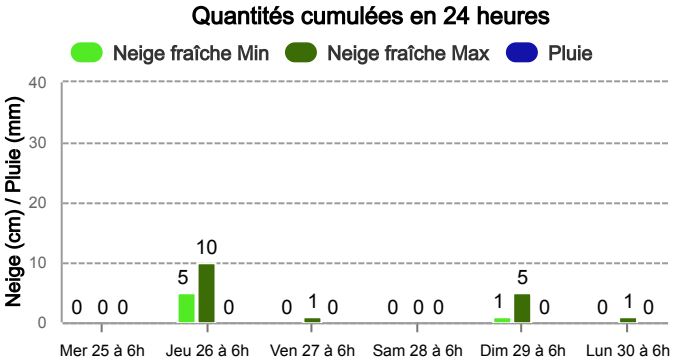

Tendance du lundi 30 mars

2

Indice de risque limité

Tempête de vent de nord-ouest ce lundi, mais il ne neige quasiment pas. Il devrait y avoir assez peu de neige transportable (uniquement les 1-5 cm tombés ce week-end), et le manteau est déjà très travaillé par le vent. Le nombre de plaques nouvellement formé pourrait rester limité, tout comme le risque, stationnaire. A confirmer.

Pour consulter la vigilance en cours, veuillez vous rendre sur le site https://vigilance.meteofrance.fr/fr

Météo-France - 73 avenue de Paris, 94165 Saint-Mandé cedex - Contact : contact@meteo.fr

Rédigé par Météo-France avec la contribution des observateurs du réseau nivo-météorologiques. Partenariat : ANMSM (Maires de Stations de Montagne), DSF (Domaines Skiables de France), ADSP (Directeurs de Pistes et de la Sécurité des Stations de Sports d'Hiver) et autres acteurs de la montagne.

Bulletin neige & avalanches par téléphone au
0 892 68 10 20 Service 0,35 € / min + prix appel

RÉPUBLIQUE FRANÇAISE
Liberté Égalité Fraternité

METEO FRANCE
À VOS CÔTÉS, DANS UN CLIMAT QUI CHANGE

Bulletin d'estimation du risque d'avalanche

(valable en dehors des pistes balisées et ouvertes)

MASSIF : Haute-Maurienne

Rédigé le samedi 28 mars 2026 à 16h

Conditions nivo-météo des 7 derniers jours

	dim. 22/03				lun. 23/03				mar. 24/03				mer. 25/03				jeu. 26/03				ven. 27/03				sam. 28/03			
	03h	09h	15h	21h	03h	09h	15h	21h	03h	09h	15h	21h	03h	09h	15h	21h	03h	09h	15h	21h	03h	09h	15h	21h	03h	09h	15h	21h
Météo																												
Vent (km/h)	15	20	20	10	15	20	20	20	20	20	15	35	50	65	85	100	100	95	90	90	60	30	30	30	30	40	40	30
à 3500m																												
Vent (km/h)	10	25	25	15	15	10	15	10	10	10	10	15	25	45	70	85	90	80	75	70	50	25	20	20	20	30	30	20
à 2500m																												

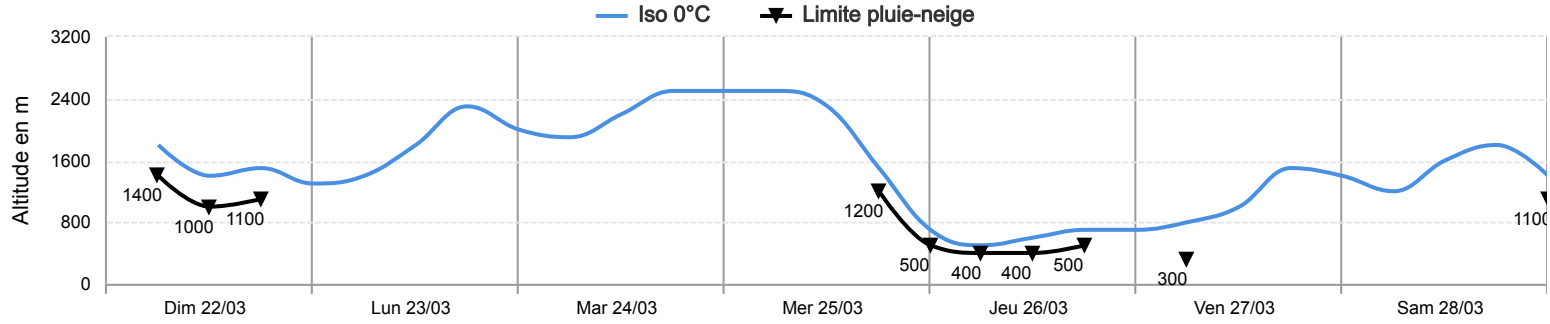

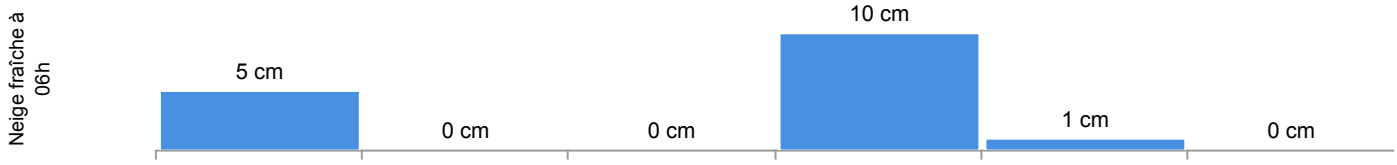

Risque d'avalanche	dim. 22/03	lun. 23/03	mar. 24/03	mer. 25/03	jeu. 26/03	ven. 27/03	sam. 28/03
	3	3	2	3	3	3	2

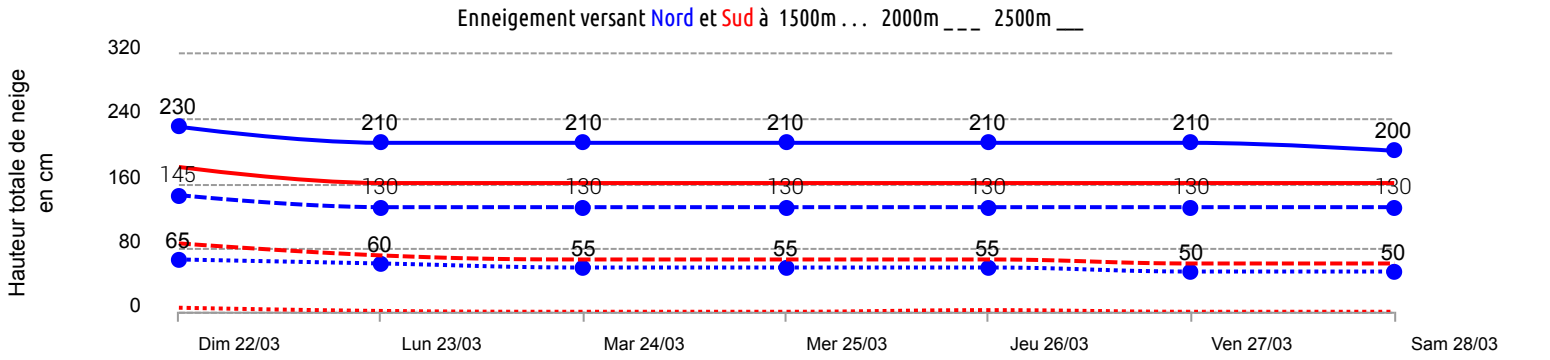

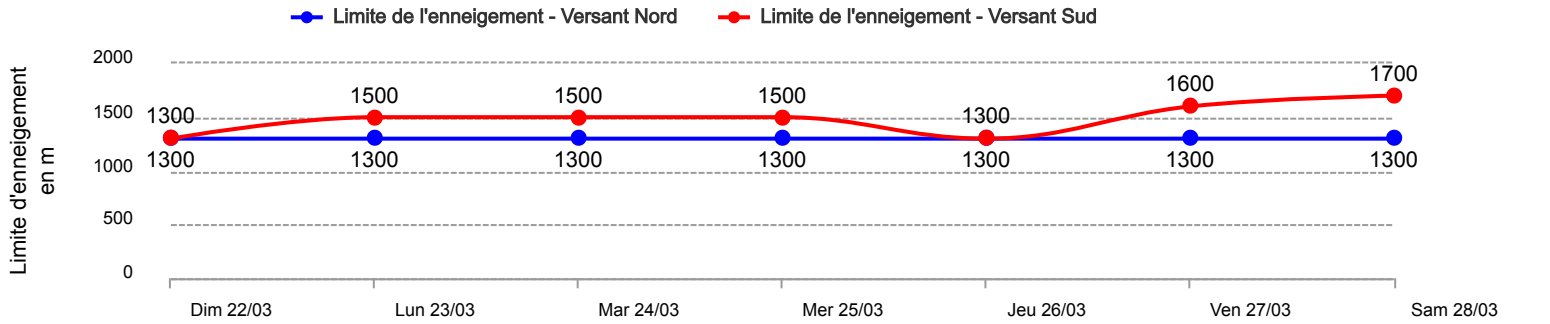

Pour consulter la vigilance en cours, veuillez vous rendre sur le site https://vigilance.meteofrance.fr/fr

Météo-France - 73 avenue de Paris, 94165 Saint-Mandé cedex - Contact : contact@meteo.fr

Bulletin neige & avalanches par téléphone au **0 892 68 10 20** Service 0,35 € / min + prix appel

Rédigé par Météo-France avec la contribution des observateurs du réseau nivo-météorologiques. Partenariat : ANMSM (Maires de Stations de Montagne), DSF (Domaines Skiables de France), ADSP (Directeurs de Pistes et de la Sécurité des Stations de Sports d'Hiver) et autres acteurs de la montagne.