Bulletin d'estimation du risque d'avalanche

(valable en dehors des pistes balisées et ouvertes)

MASSIF : Pays-Basque

Rédigé le samedi 28 mars 2026 à 16h

Estimation des risques pour le : DIMANCHE 29 MARS

PLAQUES EN ALTITUDE EN FORMATION DE PLUS EN PLUS ÉPAISSES, CHUTES DE NEIGE EN COURS.

3

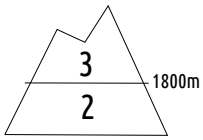

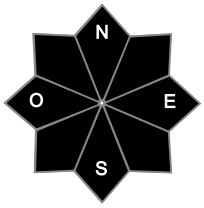

Plaques en formation

Au-dessus de 1800m indice de risque marqué, plus bas indice limité.

Départs spontanés : Départs ponctuels de plaques en altitude, sinon dans la neige récente et dans les chutes en cours.

Déclenchements provoqués : Plaques en altitude s'épaississant au fil des chutes de neige.

Indices de risque : 5 très fort - 4 fort - 3 marqué - 2 limité - 1 faible -- En noir : les pentes les plus dangereuses

Stabilité du manteau neigeux

Situation avalancheuse typique : neige fraîche — neige ventée

Déclenchements provoqués :
- **Au-dessus de 1800m**, des plaques à vent de plus en plus épaisses se forment au fil des chutes de neige de la journée, poursuivant celles de la veille et de la nuit, sous l'effet du vent fort de Nord à Nord-Est. Elles sont situées dans les pentes raides d'un large secteur Sud (de l'Est vers l'Ouest en passant par le Sud), et elles reposent sur de fines plaques à vent plus anciennes. On peut aussi les trouver dans les pentes raides des autres versants où elles viennent se former sur les fines plaques anciennes. Elles restent facilement déclenchables par un simple skieur. Des cassures linéaires de tailles moyennes sont possibles (taille 2) par faible sollicitation, parfois des grandes (taille 3) dans les zones d'accumulation les plus importantes.
- **Sous 1800m**, un simple skieur peut déclencher en tous versants des départs ponctuels dans la neige récente et dans la neige continuant de tomber, des avalanches petites à moyennes (taille 1 à 2) sont généralement attendues, plus rarement des grandes (taille 3) notamment dans les zones d'accumulation les plus importantes.

Départs spontanés :
- **Au-dessus de 1800m**, des départs ponctuels des plaques décrites ci-dessus restent possibles par surcharge par le vent, engendrant des avalanches moyennes (taille 2), parfois des grandes (taille 3) dans les zones d'accumulation les plus importantes.
- **Sous 1800m**, des départs ponctuels dans la neige récente ainsi que dans la neige continuant de tomber sont possibles, engendrant des avalanches petites à moyennes (taille 1 à 2), plus rarement des grandes (taille 3) notamment dans les zones d'accumulation les plus importantes.

Qualité de la neige

Enneigement : Correct pour la saison au-dessus de 1800m, mais restant assez maigre en versants exposés au vent d'ouest. Les nouvelles chutes de neige depuis samedi et celles continuant ce dimanche redonnent un aspect hivernal au manteau neigeux. L'enneigement débute vers 900/1000m dimanche, voire plus bas, mais reste skiable dès 1300/1400m environ, où la couche de neige paraît suffisante.

État de la neige : Couche de neige plus ou moins épaisse de neige fraîche au petit matin dimanche, s'épaississant au fil de la journée et des chutes de neige. Il s'agit de neige fraîche et récente reposant sur un fond dur et bien regelé. La neige tombée et continuant de tomber au-dessus de 1800m et très travaillée par le vent fort de Nord à Nord-Est, donnant un enneigement assez irrégulier. Les crêtes sont plutôt dégarnies, les combes sont chargées.

Aperçu météo pour le dimanche 29 mars

	nuit	matin	après-midi	soir
Le ciel est bouché en journée, des averses de neige assez régulières poursuivant celle de la nuit, accalmie en soirée. Vent fort de Nord à Nord-Est.				
Pluie-Neige	400 m	500 m	700 m	700 m
Iso 0 °C	600 m	700 m	1 100 m	1 100 m
Vent 1000 m	45 km/h	40 km/h	50 km/h	40 km/h
Vent 2000 m	80 km/h	85 km/h	75 km/h	75 km/h

Épaisseur de neige hors-piste

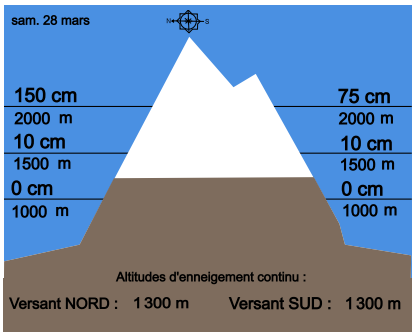

Précipitations à 1800 m

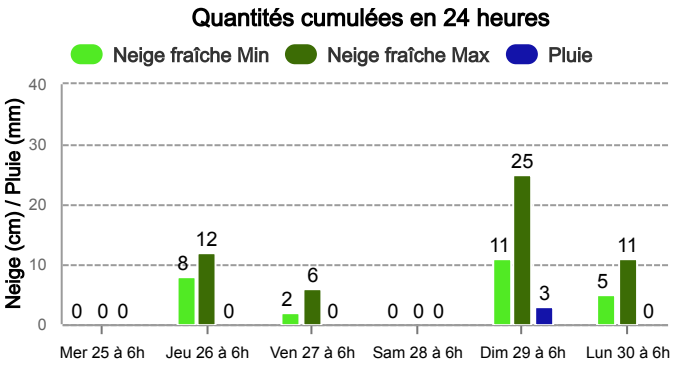

Tendance du lundi 30 mars

3

Indice de risque marqué

Maintien d'un risque marqué. Nouvelles averses de neige à venir lundi après-midi, dans une atmosphère un peu plus douce, toujours du vent fort de Nord à Nord-Ouest.

Pour consulter la vigilance en cours, veuillez vous rendre sur le site https://vigilance.meteofrance.fr/fr

Météo-France - 73 avenue de Paris, 94165 Saint-Mandé cedex - Contact : contact@meteo.fr

Rédigé par Météo-France avec la contribution des observateurs du réseau nivo-météorologiques. Partenariat : ANMSM (Maires de Stations de Montagne), DSF (Domaines Skiables de France), ADSP (Directeurs de Pistes et de la Sécurité des Stations de Sports d'Hiver) et autres acteurs de la montagne.

Bulletin neige & avalanches par téléphone au 0 892 68 10 20 Service 0,35 € / min + prix appel

RÉPUBLIQUE FRANÇAISE
Liberté Égalité Fraternité

METEO FRANCE
À VOS CÔTÉS, DANS UN CLIMAT QUI CHANGE

Bulletin d'estimation du risque d'avalanche

(valable en dehors des pistes balisées et ouvertes)

MASSIF : Pays-Basque

Rédigé le samedi 28 mars 2026 à 16h

Conditions nivo-météo des 7 derniers jours

	dim. 22/03				lun. 23/03				mar. 24/03				mer. 25/03				jeu. 26/03				ven. 27/03				sam. 28/03			
	03h	09h	15h	21h	03h	09h	15h	21h	03h	09h	15h	21h	03h	09h	15h	21h	03h	09h	15h	21h	03h	09h	15h	21h	03h	09h	15h	21h
Météo																												
Vent (km/h)	15	25	35	35	40	35	30	25	25	15	5	15	15	10	50	65	75	80	85	85	75	65	55	55	55	55	65	75
à 2000m																												
Vent (km/h)	5	15	30	25	25	25	25	15	10	10	2	5	5	2	15	25	35	40	50	50	35	35	35	25	20	25	40	45
à 1000m																												

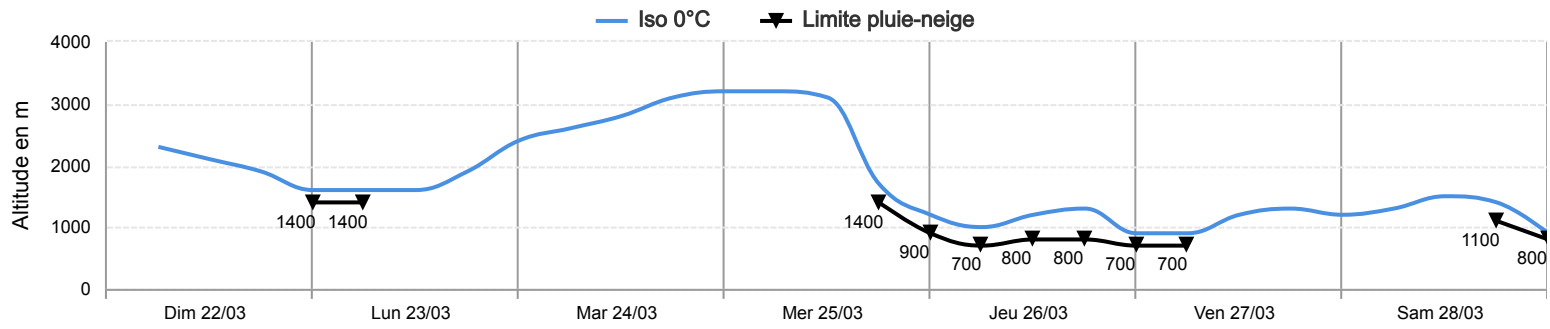

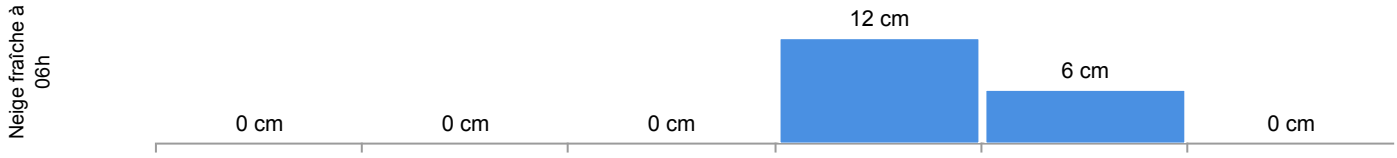

Risque d'avalanche	dim. 22/03	lun. 23/03	mar. 24/03	mer. 25/03	jeu. 26/03	ven. 27/03	sam. 28/03
	2	2	2	2	2	2	2

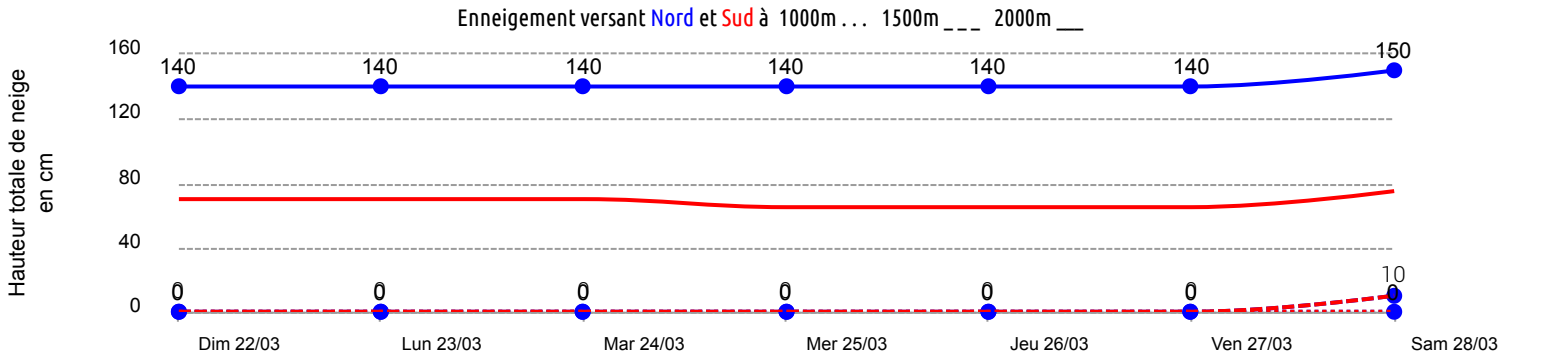

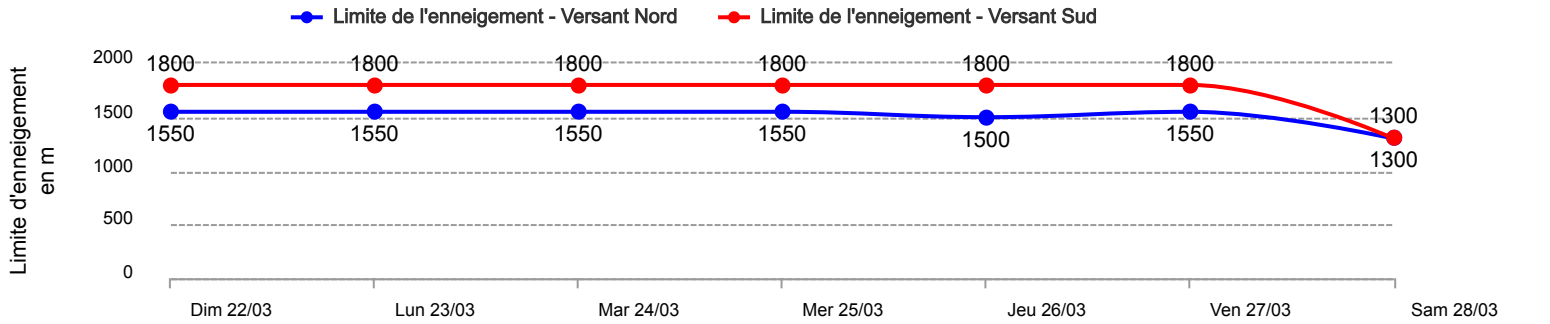

Pour consulter la vigilance en cours, veuillez vous rendre sur le site https://vigilance.meteofrance.fr/fr

Météo-France - 73 avenue de Paris, 94165 Saint-Mandé cedex - Contact : contact@meteo.fr

Rédigé par Météo-France avec la contribution des observateurs du réseau nivo-météorologiques. Partenariat : ANMSM (Maires de Stations de Montagne), DSF (Domaines Skiables de France), ADSP (Directeurs de Pistes et de la Sécurité des Stations de Sports d'Hiver) et autres acteurs de la montagne.

Bulletin neige & avalanches par téléphone au
0 892 68 10 20 Service 0,35 € / min + prix appel