Bulletin d'estimation du risque d'avalanche
(valable en dehors des pistes balisées et ouvertes)

MASSIF : Queyras

Rédigé le samedi 28 mars 2026 à 16h

Estimation des risques pour le : DIMANCHE 29 MARS

PLAQUES EN PLACE DANS LA NEIGE RÉCENTE, PLUS NOMBREUSES ET ÉPAISSES SUR LE HAUT-GUIL

2

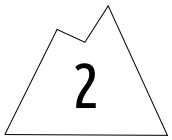

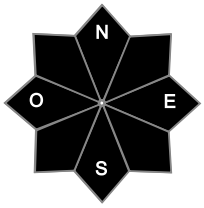

Indice de risque limité.

Départs spontanés : avalanches de neige fraîche, petites à moyennes.

Déclenchements provoqués : nouvelles plaques en formation, principalement à l'est du massif.

Indices de risque : 5 très fort - 4 fort - 3 marqué - 2 limité - 1 faible -- En noir : les pentes les plus dangereuses

Stabilité du manteau neigeux

Situation avalancheuse typique : neige ventée

Déclenchements provoqués : de nouvelles plaques sont en formation avec les chutes de neige dans la nuit de samedi à dimanche et le vent de nord-est modéré dimanche matin. Elles sont présentes en toutes orientations au-dessus de 1800/2000 m environ, plus nombreuses et épaisses sur le Haut-Guil (Abriès / Ristolas). Elles sont d'aspect durcies dans les zones exposées au vent, mais encore d'aspect poudreux dans les combes bien abritées. Elles sont facilement déclenchables par un skieur et engendrent des avalanches de taille petite (taille 1) à moyenne (taille 2) vers les crêtes frontalières du Haut-Guil.
De plus, des instabilités sont encore en place dans la neige récente ventée. Elles sont présentes en toutes orientations au-dessus de 2000/2200 m environ. Sous forme de plaques dures, elles sont facilement identifiables, localisées même loin des crêtes et ruptures de pente, et encore facilement déclenchables par un seul skieur. Elles génèrent des avalanches de petite taille (taille 1), voire moyenne (taille 2) autour de Ceillac ou sur le Haut-Guil.

Départs spontanés : avalanches de neige récente l'après-midi au fil des éclaircies qui se développent ou par surcharge du au vent de nord-est qui se renforce en matinée. Petite taille, voire moyenne sur le Haut-Guil.

Qualité de la neige

L'enneigement est proche des normales pour une fin mars.
Hauteurs de neige observées : 152 cm en versant nord du col Izoard à 2300 m, 142 cm au-dessus de St Véran à 2700 m, 94 cm à la Nivôse du Col Agnel à 2630 m

Limite d'enneigement skiable : au plus bas à 1400/1500 m en ubacs bien protégés ou sur pistes forestières, plutôt 2000/2100 m en adrets.

État de la neige de surface : 15 à 20 cm de neige fraîche, plutôt 5/10 cm vers les Fonts de Cervières ou entre Ceillac et Saint-Véran. Cette neige tombe peu ventée et est donc légère. Neige localement durcie par le vent qui se lève en matinée de dimanche. Sur l'ouest du massif, neige récente fortement travaillée par le vent, mais localement encore légère dans les secteurs bien abrités. Crêtes parfois décapées. En versant sud, neige croutée sous 2200/2400 m, s'humidifiant en journée.

Aperçu météo pour le dimanche 29 mars

	nuit	matin	après-midi	soir
Pluie-Neige	900 m	900 m		
Iso 0 °C	1 300 m	1 500 m	2 000 m	2 000 m
Vent 2000 m	↓ 20 km/h	↓ 25 km/h	↓ 25 km/h	↙ 15 km/h
Vent 3000 m	↘ 25 km/h	← 30 km/h	↙ 25 km/h	↘ 15 km/h

Chutes de neige dans la nuit de samedi à dimanche, plus importantes sur l'est du massif. Retour de belles éclaircies en cours de journée.

Épaisseur de neige hors-piste

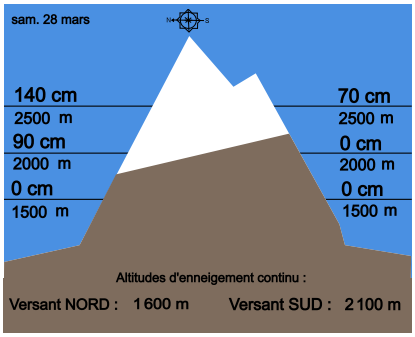

Précipitations à 1800 m

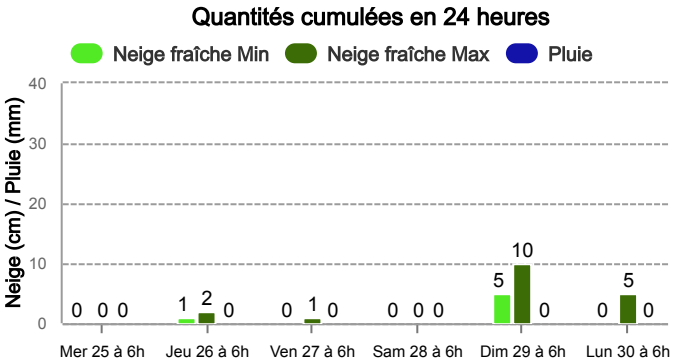

Tendance du lundi 30 mars

2 **Indice de risque limité**

Risque en hausse mais restant a priori limité. Formation de nouvelles plaques avec le vent de nord-ouest qui devient tempétueux en montagne au fil de l'après-midi de lundi.

Pour consulter la vigilance en cours, veuillez vous rendre sur le site https://vigilance.meteofrance.fr/fr

Météo-France - 73 avenue de Paris, 94165 Saint-Mandé cedex - Contact : contact@meteo.fr

Rédigé par Météo-France avec la contribution des observateurs du réseau nivo-météorologiques. Partenariat : ANMSM (Maires de Stations de Montagne), DSF (Domaines Skiables de France), ADSP (Directeurs de Pistes et de la Sécurité des Stations de Sports d'Hiver) et autres acteurs de la montagne.

Bulletin neige & avalanches par téléphone au **0 892 68 10 20** Service 0,35 € / min + prix appel

RÉPUBLIQUE FRANÇAISE
Liberté Égalité Fraternité

METEO FRANCE
À VOS CÔTÉS, DANS UN CLIMAT QUI CHANGE

Bulletin d'estimation du risque d'avalanche

(valable en dehors des pistes balisées et ouvertes)

MASSIF : Queyras

Rédigé le samedi 28 mars 2026 à 16h

Conditions nivo-météo des 7 derniers jours

	dim. 22/03				lun. 23/03				mar. 24/03				mer. 25/03				jeu. 26/03				ven. 27/03				sam. 28/03			
	03h	09h	15h	21h	03h	09h	15h	21h	03h	09h	15h	21h	03h	09h	15h	21h	03h	09h	15h	21h	03h	09h	15h	21h	03h	09h	15h	21h
Météo																												
Vent (km/h)	20	30	40	35	25	20	20	15	15	10	15	10	25	40	70	80	85	75	65	60	50	20	10	10	15	20	30	25
à 3000m	←	←	←	←	←	↙	↙	←	←	↘	→	→	→	→	→	↘	↘	↓	↓	↓	↙	↙	↙	←	→	↘	↘	↘
Vent (km/h)	15	25	30	30	20	15	20	10	10	10	15	5	10	20	50	60	65	60	50	50	40	20	10	10	10	15	25	20
à 2000m	←	←	↙	↙	↙	↙	←	←	←	↗	↗	→	→	→	→	↓	→	↓	↓	↘	↓	↓	↓	←	→	↓	↓	↓

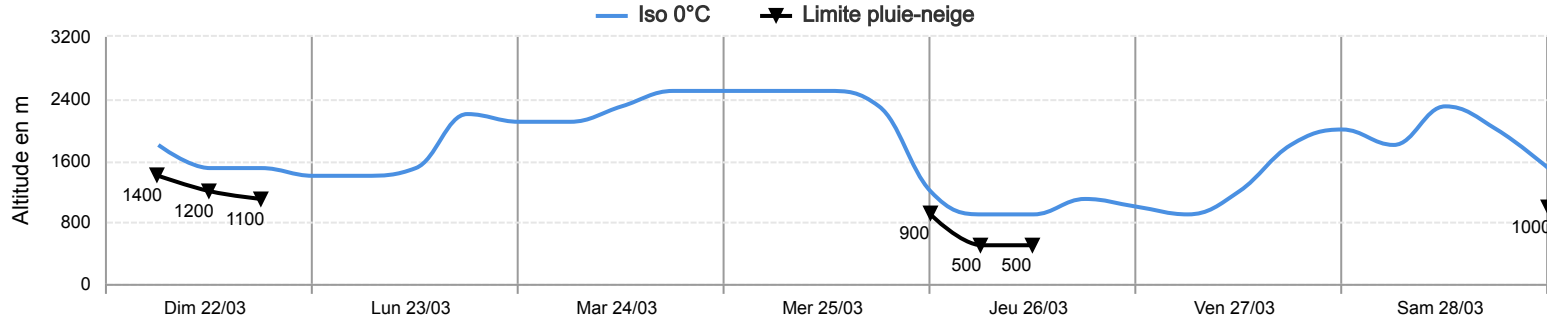

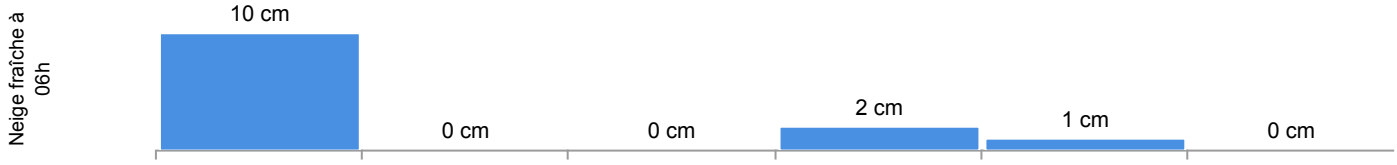

Risque d'avalanche	dim. 22/03	lun. 23/03	mar. 24/03	mer. 25/03	jeu. 26/03	ven. 27/03	sam. 28/03
	3	3	2	2	3	2	2

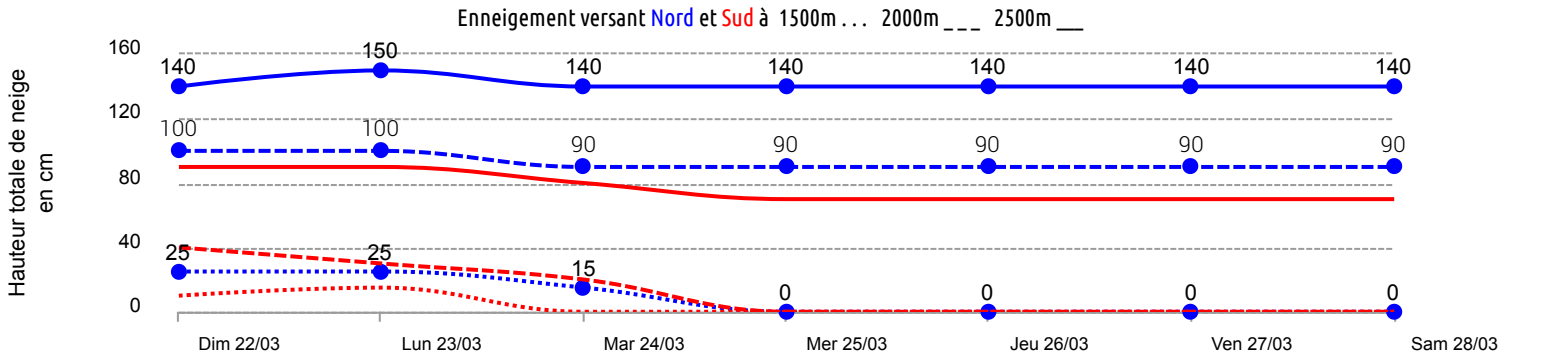

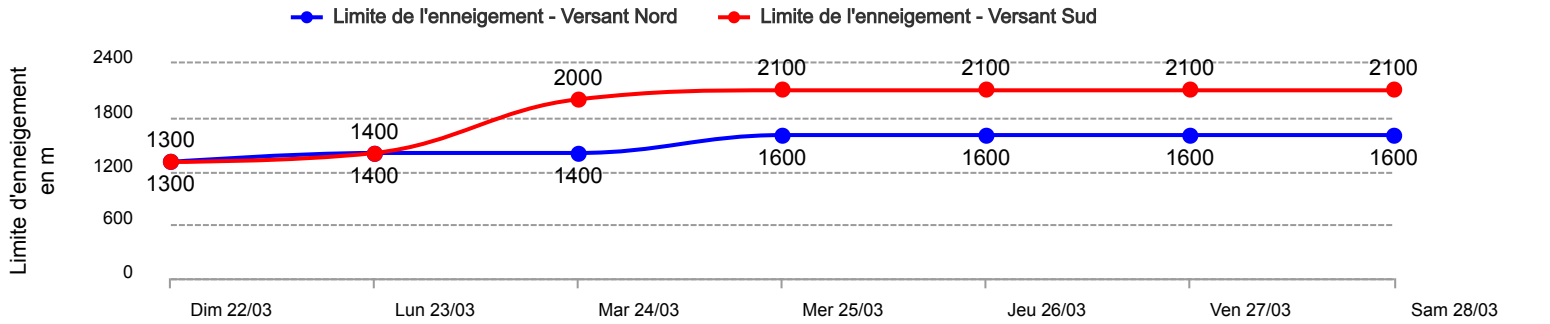

Pour consulter la vigilance en cours, veuillez vous rendre sur le site https://vigilance.meteofrance.fr/fr

Météo-France - 73 avenue de Paris, 94165 Saint-Mandé cedex - Contact : contact@meteo.fr

Bulletin neige & avalanches par téléphone au

0 892 68 10 20 Service 0,35 € / min + prix appel

Rédigé par Météo-France avec la contribution des observateurs du réseau nivo-météorologiques. Partenariat : ANMSM (Maires de Stations de Montagne), DSF (Domaines Skiables de France), ADSP (Directeurs de Pistes et de la Sécurité des Stations de Sports d'Hiver) et autres acteurs de la montagne.