Bulletin d'estimation du risque d'avalanche

(valable en dehors des pistes balisées et ouvertes)

MASSIF : Renoso Incudine

Rédigé le samedi 28 mars 2026 à 16h

Estimation des risques pour le : DIMANCHE 29 MARS

INSTABILITÉS EN ALTITUDE

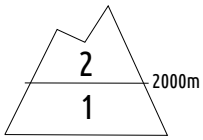

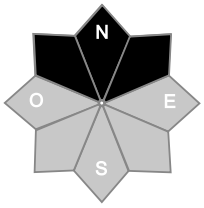

Au-dessus de 2000m indice de risque limité, plus bas indice faible.

Départs spontanés : rares coulées de neige récente

Déclenchements provoqués : plaques à vent difficilement sollicitables, encore présentes en altitude au-dessus de 2000 m

Indices de risque : 5 très fort - 4 fort - 3 marqué - 2 limité - 1 faible -- En noir : les pentes les plus dangereuses

Stabilité du manteau neigeux

Situation avalancheuse typique : neige ventée

Déclenchements provoqués : de fines plaques à vent sont en place dans les pentes raides en toutes orientations, majoritairement au-dessus de 2000 m issues des chutes de neige précédentes. Elles peuvent engendrer des avalanches de taille petite à moyenne (taille 1 à 2) avec des cassures de 10/20 cm voire 30 cm en versants ombragés.
Départs spontanés : peu probable en matinée avec une croute parfois épaisse puis d'éventuels départs de coulées ou avalanche de neige humide sont possibles si le relatif et temporaire redoux s'accompagnant d'éclaircies l'après midi permet une humidification de la neige récente.
Autres : Nombreuses surfaces dures et glacées, pouvant être recouvertes de quelques centimètres de neige récente. Présence de corniches.

Qualité de la neige

Qualification de l'enneigement : L'enneigement est excellent pour la saison au-dessus de 1600 m. Au Val d'Ese, on estime à un peu plus de 2m00 la hauteur de neige à 1800 m. À Ghisoni Capanelle, on mesure environ 3m00 dans les combes abritées.
Limite d'enneigement skiable : 1500 m.
État de la neige : En surface, on trouve dix à vingt cm de neige récente, voire plus par endroits, ils recouvrent un manteau neigeux dure bien regelé. Cette couche de neige récente, ventée surtout en très haute montagne, poursuit son tassement. En surface, elle peut être partiellement croûtée le matin après le regel nocturne puis le manque de soleil limite la transformation de cette neige avec un décaillage superficiel. En secteurs plus ombragés ou à soleil plus rasant, elle reste lourde et profonde, ou bien partiellement densifiée par le vent. Neige restant croûtée dans les secteurs ombragés raides.

Aperçu météo pour le dimanche 29 mars

	nuit	matin	après-midi	soir
Pluie-Neige				
Iso 0 °C	1 800 m	1 700 m	1 900 m	1 900 m
Vent 1500 m	30 km/h	40 km/h	50 km/h	30 km/h
Vent 2000 m	30 km/h	40 km/h	50 km/h	40 km/h

Épaisseur de neige hors-piste

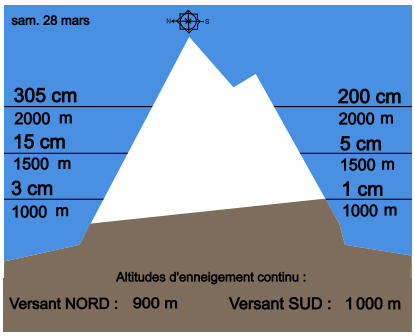

Précipitations à 1800 m

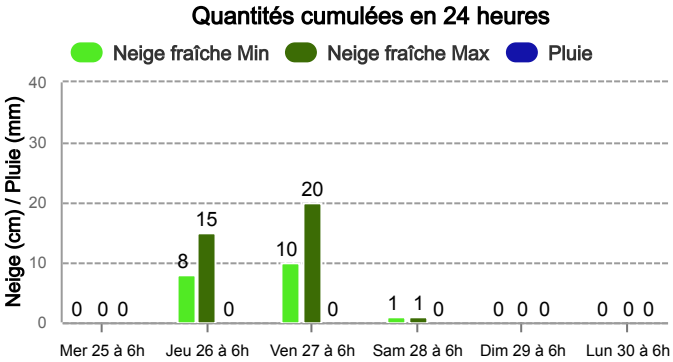

Tendance du lundi 30 mars

Indice de risque limité

Pas dévolution notable en termes de risque.

Pour consulter la vigilance en cours, veuillez vous rendre sur le site https://vigilance.meteofrance.fr/fr

Météo-France - 73 avenue de Paris, 94165 Saint-Mandé cedex - Contact : contact@meteo.fr

Rédigé par Météo-France avec la contribution des observateurs du réseau nivo-météorologiques. Partenariat : ANMSM (Maires de Stations de Montagne), DSF (Domaines Skiables de France), ADSP (Directeurs de Pistes et de la Sécurité des Stations de Sports d'Hiver) et autres acteurs de la montagne.

Bulletin neige & avalanches par téléphone au 0 892 68 10 20 Service 0,35 € / min + prix appel

RÉPUBLIQUE FRANÇAISE
Liberté Égalité Fraternité

METEO FRANCE
À VOS CÔTÉS, DANS UN CLIMAT QUI CHANGE

Bulletin d'estimation du risque d'avalanche

(valable en dehors des pistes balisées et ouvertes)

MASSIF : Renoso Incudine

Rédigé le samedi 28 mars 2026 à 16h

Conditions nivo-météo des 7 derniers jours

	dim. 22/03				lun. 23/03				mar. 24/03				mer. 25/03				jeu. 26/03				ven. 27/03				sam. 28/03			
	03h	09h	15h	21h	03h	09h	15h	21h	03h	09h	15h	21h	03h	09h	15h	21h	03h	09h	15h	21h	03h	09h	15h	21h	03h	09h	15h	21h
Météo																												
Vent (km/h)	15	15	15	10	10	15	20	30	30	30	10	10	25	60	95	130	115	65	45	65	25	30	10	40	40	15	10	10
à 2000m																												
Vent (km/h)	10	15	10	5	5	10	15	25	10	15	5	10	10	55	70	120	80	60	40	45	10	5	5	10	25	15	25	10
à 1500m																												

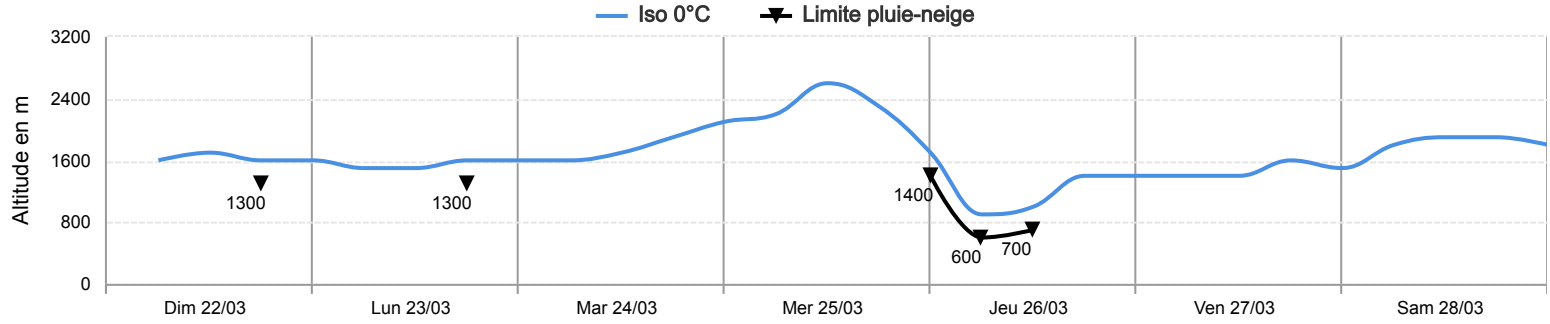

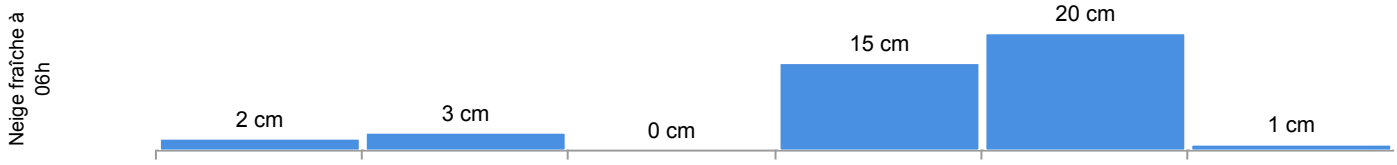

Risque d'avalanche	dim. 22/03	lun. 23/03	mar. 24/03	mer. 25/03	jeu. 26/03	ven. 27/03	sam. 28/03
	2	2	2	2	2	2	2

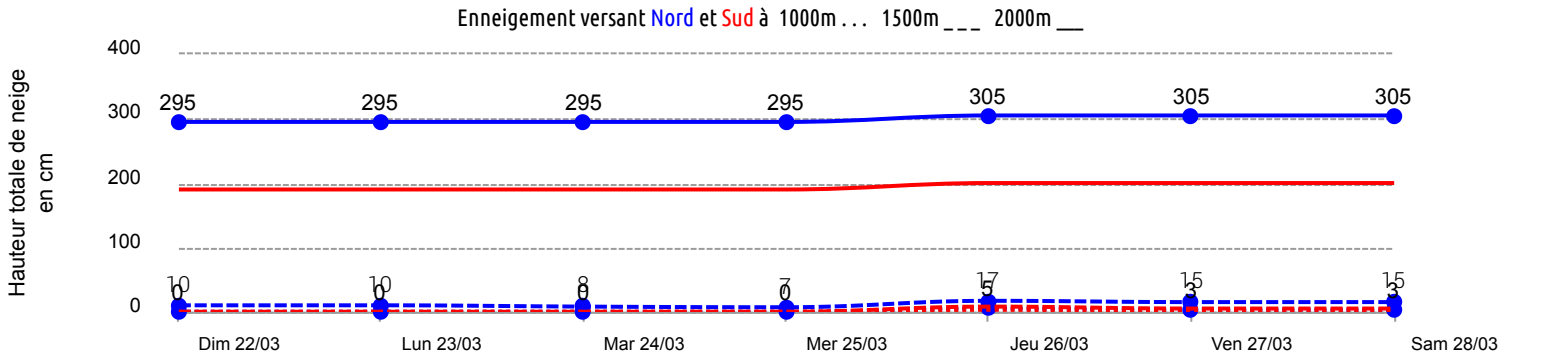

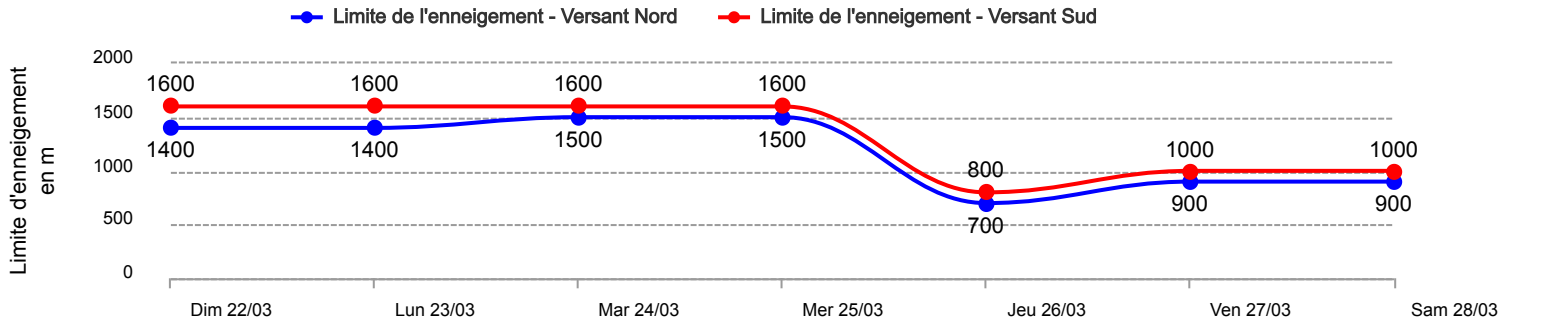

Pour consulter la vigilance en cours, veuillez vous rendre sur le site https://vigilance.meteofrance.fr/fr

Météo-France - 73 avenue de Paris, 94165 Saint-Mandé cedex - Contact : contact@meteo.fr

Bulletin neige & avalanches par téléphone au

0 892 68 10 20 Service 0,35 € / min + prix appel

Rédigé par Météo-France avec la contribution des observateurs du réseau nivo-météorologiques. Partenariat : ANMSM (Maires de Stations de Montagne), DSF (Domaines Skiables de France), ADSP (Directeurs de Pistes et de la Sécurité des Stations de Sports d'Hiver) et autres acteurs de la montagne.