Bulletin d'estimation du risque d'avalanche

(valable en dehors des pistes balisées et ouvertes)

MASSIF : Thabor

Rédigé le samedi 28 mars 2026 à 16h

Estimation des risques pour le : DIMANCHE 29 MARS

PLAQUES EN PLACE DANS LA NEIGE VENTÉE - DE NOUVELLES PEU ÉPAISSES EN FORMATION VERS LA SAVOIE

2

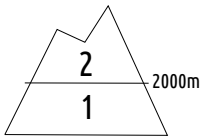

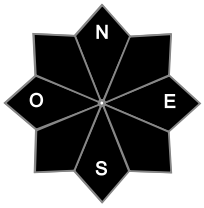

Au-dessus de 2000m indice de risque limité, plus bas indice faible.

Départs spontanés : petites avalanches de neige récente au fil des éclaircies l'après-midi.

Déclenchements provoqués : instabilités superficielles dans la neige ventée, plus nombreuses vers la Savoie.

Indices de risque : 5 très fort - 4 fort - 3 marqué - 2 limité - 1 faible -- En noir : les pentes les plus dangereuses

Stabilité du manteau neigeux

Situation avalancheuse typique : neige ventée

Déclenchements provoqués : à proximité de la Savoie uniquement, de rares plaques minces se forment avec les faibles chutes de neige dans la nuit de samedi à dimanche. Présentes en toutes orientations, elles peuvent être faciles à déclencher par le passage d'un skieur, mais engendrent des avalanches de taille petite uniquement (taille 1).
De plus et sur l'ensemble du massif, des instabilités sont encore en place dans la neige récente ventée. Elles sont présentes en toutes orientations au-dessus de 2000/2200 m environ. Sous forme de plaques dures, elles sont facilement identifiables, localisées même loin des crêtes et ruptures de pente, et encore facilement déclenchables par un seul skieur. Elles génèrent des avalanches de petite taille (taille 1), voire moyenne (taille 2) en allant vers la Savoie.

Départs spontanés : peu probables le matin. À proximité de la Savoie, quelques avalanches de neige récente l'après-midi au fil des éclaircies qui se développent. Petite taille uniquement.

Qualité de la neige

L'enneigement est proche des normales pour une fin mars.
Hauteurs de neige observées vers 2500 m : 173 cm dans le vallon du Chardonnet, 115 cm à la nivôse des Rochilles, 82 cm à la Nivôse du Galibier (secteurs fortement ventés).

Limite d'enneigement skiable : dès 1400 m en ubacs favorables (terrains herbeux, pistes forestières), 1800/1900 m en adrets pas trop raides.

État de la neige de surface : 5/10 cm de neige fraîche à proximité de la Savoie. Sinon, neige récente fortement travaillée par le vent, mais localement encore légère dans les secteurs bien abrités. Sur les crêtes, d'épaisses corniches côtoient des zones pelées par le vent.
En versant sud, neige croutée sous 2200/2400, s'humidifiant en journée.

Aperçu météo pour le dimanche 29 mars

Faibles chutes de neige dans la nuit de samedi à dimanche, plutôt en bordure de la Savoie. Retour de belles éclaircies en cours de journée.

	nuit	matin	après-midi	soir
Pluie-Neige	900 m			
Iso 0 °C	1 300 m	1 300 m	2 000 m	2 000 m
Vent 2000 m	↓ 35 km/h	↓ 20 km/h	↘ 30 km/h	↘ 25 km/h
Vent 3000 m	↘ 45 km/h	↓ 20 km/h	↘ 30 km/h	↘ 30 km/h

Épaisseur de neige hors-piste

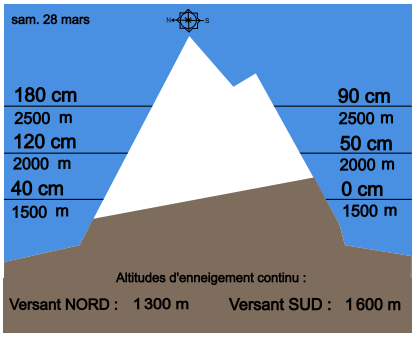

Précipitations à 1800 m

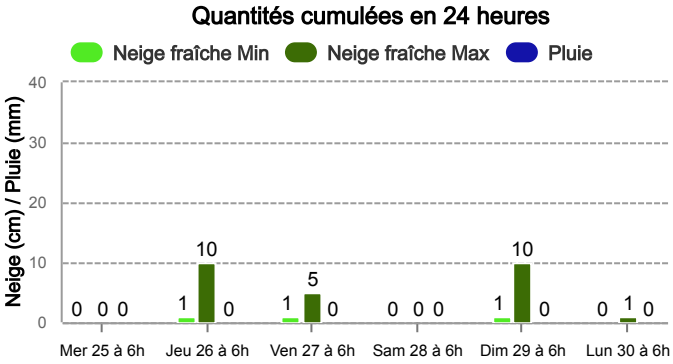

Tendance du lundi 30 mars

2

Indice de risque limité

Risque en hausse mais restant a priori limité. Formation de nouvelles plaques avec le vent de nord-ouest qui devient tempétueux en montagne au fil de l'après-midi de lundi.

Pour consulter la vigilance en cours, veuillez vous rendre sur le site https://vigilance.meteofrance.fr/fr

Météo-France - 73 avenue de Paris, 94165 Saint-Mandé cedex - Contact : contact@meteo.fr

Rédigé par Météo-France avec la contribution des observateurs du réseau nivo-météorologiques. Partenariat : ANMSM (Maires de Stations de Montagne), DSF (Domaines Skiables de France), ADSP (Directeurs de Pistes et de la Sécurité des Stations de Sports d'Hiver) et autres acteurs de la montagne.

Bulletin neige & avalanches par téléphone au 0 892 68 10 20 Service 0,35 € / min + prix appel

RÉPUBLIQUE FRANÇAISE
Liberté Égalité Fraternité

METEO FRANCE
À VOS CÔTÉS, DANS UN CLIMAT QUI CHANGE

Bulletin d'estimation du risque d'avalanche

(valable en dehors des pistes balisées et ouvertes)

MASSIF : Thabor

Rédigé le samedi 28 mars 2026 à 16h

Conditions nivo-météo des 7 derniers jours

	dim. 22/03				lun. 23/03				mar. 24/03				mer. 25/03				jeu. 26/03				ven. 27/03				sam. 28/03			
	03h	09h	15h	21h	03h	09h	15h	21h	03h	09h	15h	21h	03h	09h	15h	21h	03h	09h	15h	21h	03h	09h	15h	21h	03h	09h	15h	21h
Météo																												
Vent (km/h)	25	30	35	35	30	15	20	20	20	15	15	15	30	50	70	80	90	90	80	70	65	50	30	30	30	40	50	60
à 3000m																												
Vent (km/h)	10	20	25	25	20	15	20	15	10	10	15	10	15	25	70	70	60	55	50	45	40	35	15	15	20	30	40	35
à 2000m																												

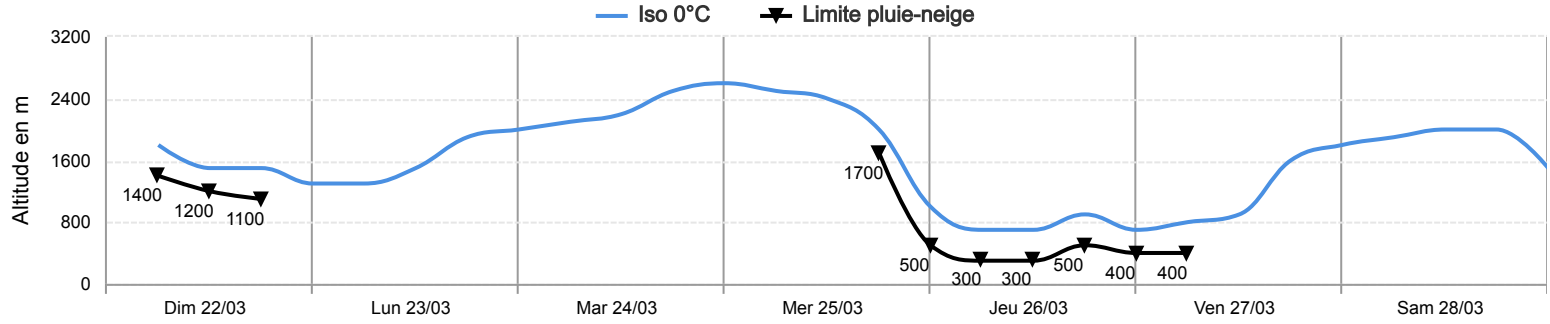

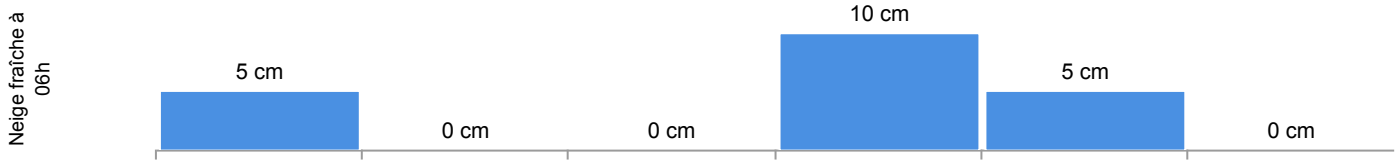

Risque d'avalanche	dim. 22/03	lun. 23/03	mar. 24/03	mer. 25/03	jeu. 26/03	ven. 27/03	sam. 28/03
	2	2	2	2	3	3	2

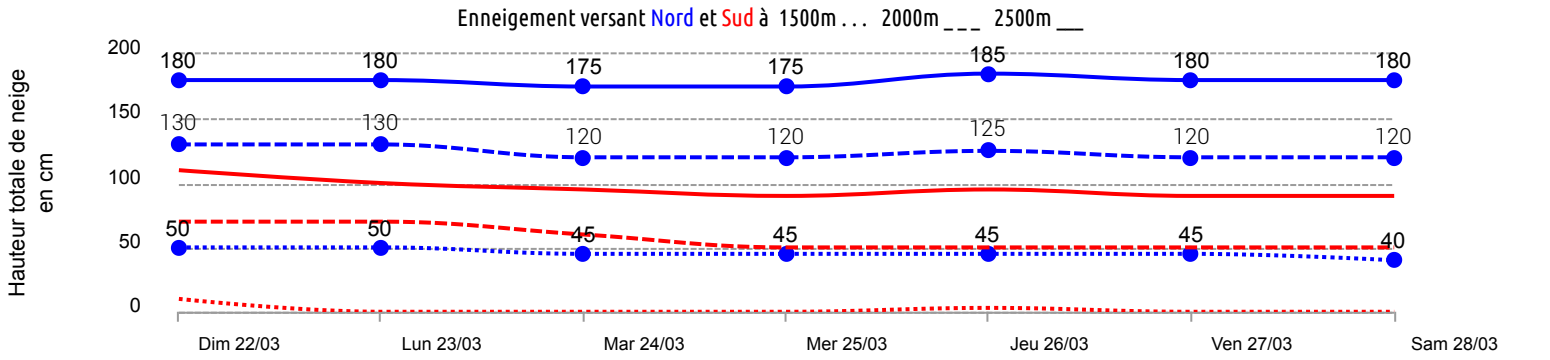

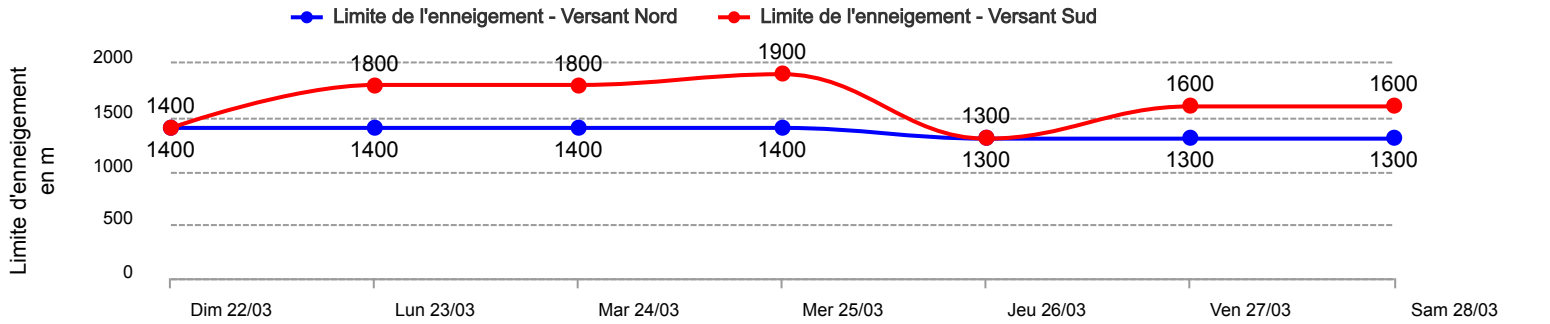

Pour consulter la vigilance en cours, veuillez vous rendre sur le site https://vigilance.meteofrance.fr/fr

Météo-France - 73 avenue de Paris, 94165 Saint-Mandé cedex - Contact : contact@meteo.fr

Rédigé par Météo-France avec la contribution des observateurs du réseau nivo-météorologiques. Partenariat : ANMSM (Maires de Stations de Montagne), DSF (Domaines Skiables de France), ADSP (Directeurs de Pistes et de la Sécurité des Stations de Sports d'Hiver) et autres acteurs de la montagne.

Bulletin neige & avalanches par téléphone au

0 892 68 10 20 Service 0,35 € / min + prix appel