GOBIERNO DE ESPAÑA
VICEPRESIDENCIA TERCERA DEL GOBIERNO
MINISTERIO PARA LA TRANSICIÓN ECOLÓGICA Y EL RETO DEMOGRÁFICO

Boletín de información nivológica y de peligro de aludes

Pirineo Catalán

aemet Agencia Estatal de Meteorología

domingo, 29 de marzo de 2026

Pronóstico hasta las 24 horas del lunes, día 30 de marzo

(Válido fuera de pistas de esquí balizadas y abiertas)

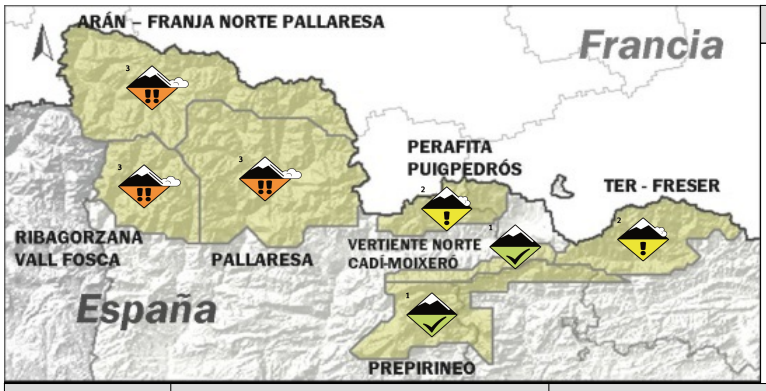

Problemas de aludes

Placas de viento

Nieve reciente

Macizo	Peligro	Problemas de aludes, cota, orientación, tamaño	Innivación observada (m)
Arán - Franja norte Pallaresa	3 Notable	Placas de viento: 2 Nieve reciente: 2	2026-03-29 N / S Cota más baja caras N
Ribagorzana - Vall Fosca	3 Notable	Placas de viento: 2 Nieve reciente: 2	2026-03-29 N / S Cota más baja caras N
Pallaresa	3 Notable	Placas de viento: 2 Nieve reciente: 2	2026-03-29 N / S Cota más baja caras N

AEMET. Se autoriza la reproducción de su contenido citando la fuente.

Boletín de información nivológica y de peligro de aludes

Pirineo Catalán

Perafita - Puigpedrós	2 **Limitado**	**Placas de viento**  **Nieve reciente** 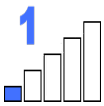	2026-03-29 Cota más baja caras N
Ter - Freser	2 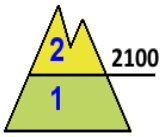 **Limitado**	**Placas de viento** 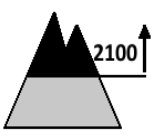  **Nieve reciente** 	2026-03-29 Cota más baja caras N
Vertiente norte Cadí - Moixeró	1 **Débil**	**Placas de viento**  **Nieve reciente** 	2026-03-29 Cota más baja caras N
Prepirineo	1 **Débil**	**Placas de viento** 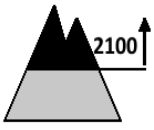  **Nieve reciente** 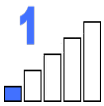	2026-03-29 Cota más baja caras N

Estado del manto y observaciones recientes

Ayer por la tarde se inició un episodio de nieve acompañado de ventiscas con viento fuerte o muy fuerte de componente norte. Hasta las 8 UTC de hoy los espesores medidos en la red de observación han aumentado en 20-30 cm en el Arán-F.N.Pallaresa y norte de los macizos ilerdenses, donde las nevadas han sido más intensas. En el resto de sectores las nevadas han sido débiles o localmente moderadas.

AEMET. Se autoriza la reproducción de su contenido citando la fuente.

Mala cohesión entre la nieve reciente distribuida muy heterogéneamente por los fuertes vientos y el manto previo mayoritariamente encostrado excepto en umbrías de las cotas altas más altas.
En umbrías de cotas altas, todavía pueden existir capas débiles internas que pueden colapsar ante sobrecargas fuertes.
En cuanto su continuidad, el manto se inicia en cotas medias, algo más arriba en las laderas norte que en las sur. Los espesores siguen estando muy por encima de lo habitual para la época, superándose los 150-200 cm en cota 2200 en la mayoría de zonas.

Evolución del manto y peligro de aludes para el lunes, día 30

Problemas de nieve reciente y de placas de viento en cotas altas.

Se esperan entre hoy domingo y mañana lunes acumulaciones de nieve reciente en cotas altas de 20 a 30 cm en el Arán-F.N.Pallaresa y de 10 a 15 cm al norte de los macizos ilerdenses. En el resto, no se esperan acumulaciones superiores a los 5-10 cm.
Con el acusado aumento térmico, serán probables aludes naturales de nieve reciente seca y húmeda en laderas inclinadas poco afectadas por el viento. Los aludes serían de tamaño pequeño en el área oriental y mediano en la occidental.
Se han formando numerosas placas de viento con mal contacto sobre el manto previo endurecido, incluso en cotas medias y en todas las orientaciones, más probables en orientaciones sur, este y oeste. Se localizarán bajo collados y crestas no venteadas donde haya predominado la acumulación. Se irán engrosando y siendo más sensibles, capaces de colapsar accidentalmente ante sobrecargas débiles o de forma natural incluso y serán susceptibles de desencadenar aludes de tamaño pequeño o mediano, localmente grande donde las acumulaciones hayan sido mayores o si implican capas débiles internas.

Predicción meteorológica para el lunes, día 30

Muy nuboso o cubierto en el Pirineo occidental, con visibilidad localmente reducida. Nuboso en la mitad oriental.
Precipitaciones débiles o moderadas, más frecuentes e intensas en el Arán y norte de la Pallaresa, donde podrían ser localmente persistentes, y con baja probabilidad en el Ripollés y Prepirineo. Cota de nieve en ascenso hasta los 1600-1800 metros.
Temperaturas mínimas en ligero ascenso. Máximas en ascenso notable. Heladas débiles, moderadas en cotas altas, donde podrán ser localmente fuertes y persistentes.
Viento moderado o fuerte del norte y noroeste, con rachas muy fuertes en cotas altas y zonas expuestas que podrían superar los 100 km/h.

Datos en la atmósfera libre:

Altitud de la isoterma de 0 ºC: 2000 m
Altitud de la isoterma de -10 ºC: 4400 m

Viento a 1500 m: N 30 km/h
Viento a 3000 m: N 100 km/h

AEMET. Se autoriza la reproducción de su contenido citando la fuente.

Evolución para el martes día 31

Nivel de peligro sin cambios o en ligero ascenso.

Escala europea de peligro de aludes

Débil | Limitado | Notable | Fuerte | Muy Fuerte

Problemas de aludes

Nieve reciente | Placas de viento | Capas débiles persistentes | Nieve húmeda | Deslizamientos basales | Sin problema evidente

Nota1: Se recuerda que, siempre que haya nieve, la ausencia total de peligro no existe. Hay que tener presente que en circunstancias desfavorables, con aludes de tamaño 1 (alud pequeño o colada) y tamaño 2 (alud mediano), se pueden sufrir severos daños personales.

Nota2: Los BPA se elaboran en base a información meteorológica así como al estado del manto nivoso a través de sondeos puntuales. Se advierte a los usuarios de la variabilidad de esta información al extrapolarla a zonas extensas de montaña. Por ello, AEMET no se hace responsable de su uso para la toma de decisiones que conciernen a la seguridad personal, ni de los riesgos físicos o materiales de ellas derivadas.

AEMET. Se autoriza la reproducción de su contenido citando la fuente.