GOBIERNO DE ESPAÑA
VICEPRESIDENCIA TERCERA DEL GOBIERNO
MINISTERIO PARA LA TRANSICIÓN ECOLÓGICA Y EL RETO DEMOGRÁFICO

Boletín de información nivológica y de peligro de aludes

Pirineo Navarro y Aragonés

aemet Agencia Estatal de Meteorología

domingo, 29 de marzo de 2026

Pronóstico hasta las 24 horas del lunes, día 30 de marzo

(Válido fuera de pistas de esquí balizadas y abiertas)

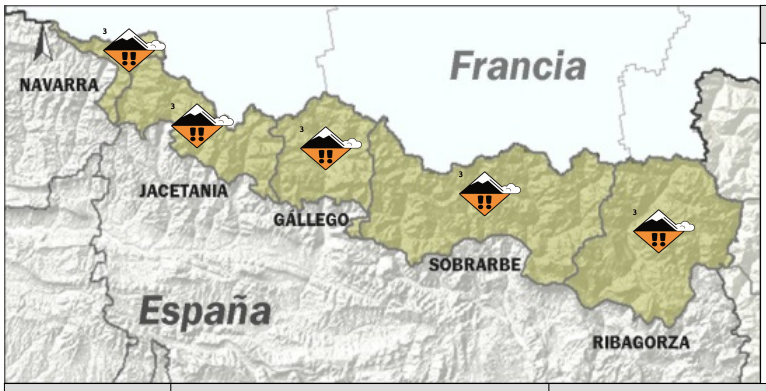

Problemas de aludes

Placas de viento

Nieve reciente

Macizo	Peligro	Problemas de aludes, cota, orientación, tamaño	Innivación observada (m)
Navarra	3 / 3 (1800) / 2 Notable	Placas de viento: 1800, N O E S, 2 Nieve reciente: N O E S, 2	2026-03-29 N S Cota más baja caras N
Jacetania	3 / 3 (1800) / 2 Notable	Placas de viento: 1800, N O E S, 2 Nieve reciente: N O E S, 2	2026-03-29 N S Cota más baja caras N
Gállego	3 / 3 (1800) / 2 Notable	Placas de viento: 1800, N O E S, 2 Nieve reciente: N O E S, 2	2026-03-29 N S Cota más baja caras N

AEMET. Se autoriza la reproducción de su contenido citando la fuente.

Boletín de información nivológica y de peligro de aludes

Pirineo Navarro y Aragonés

Sobrarbe	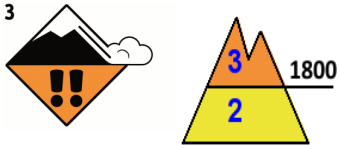 **Notable**	**Placas de viento** **Nieve reciente** 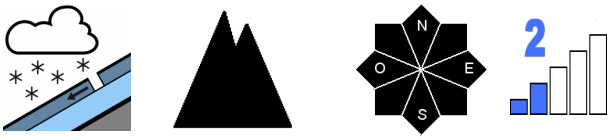	2026-03-29 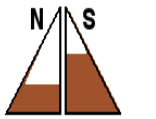 Cota más baja caras N
Ribagorza	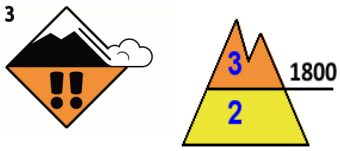 **Notable**	**Placas de viento** **Nieve reciente** 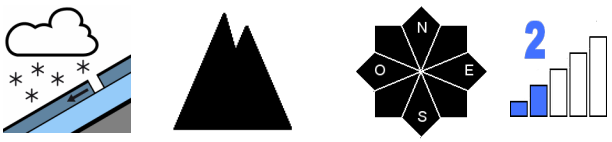	2026-03-29 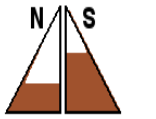 Cota más baja caras N

Estado del manto y observaciones recientes

Ayer por la tarde se inició un episodio de nieve acompañado de ventiscas con viento fuerte o muy fuerte de componente norte. Hasta las 8 UTC de hoy los espesores medidos en la red de observación han aumentado localmente en 15-30 cm. Mala cohesión entre la nieve reciente distribuida muy heterogéneamente por los fuertes vientos y el manto previo mayoritariamente encostrado excepto en umbrías de las cotas altas más altas, por encima de 2500 m.
Capas débiles persistentes en la base del manto aún presentes en cotas altas, ECTP difícil en algunos puntos, en otros ECTX con la capa ya endurecida.
En cuanto a su continuidad, el manto se inicia en cotas medias, algo más arriba en laderas norte (1600 m) que en las sur (1800 m). Los espesores siguen estando por encima de lo habitual para la época, con valores de 150-200 cm en cota 2200. Parte oriental-norte con más grueso que el resto.
No se han reportado aludes en las últimas 24 h.

Evolución del manto y peligro de aludes para el lunes, día 30

Problemas de nieve reciente y de placas de viento en cotas altas.

Se esperan entre hoy domingo y mañana lunes acumulaciones de nieve reciente de 10 a 15 cm, localmente 20-25 cm.
Con el acusado aumento térmico, serán probables aludes naturales de nieve reciente seca y húmeda en laderas inclinadas poco afectadas por el viento. Los aludes serían de tamaño mediano en general.
Se han formando numerosas placas de viento con mal contacto sobre el manto previo endurecido, incluso en cotas medias por encima de los 1800 m y en todas las orientaciones, más probables en orientaciones sur, este y oeste. Se localizarán bajo collados y crestas no venteadas donde haya predominado la acumulación. Se irán engrosando y siendo más sensibles, capaces de colapsar accidentalmente ante sobrecargas débiles o de forma natural

AEMET. Se autoriza la reproducción de su contenido citando la fuente.

incluso y serán susceptibles de desencadenar aludes de tamaño mediano, localmente grande donde las acumulaciones hayan sido mayores o si implican capas débiles internas.

Predicción meteorológica para el lunes, día 30

Pirineo navarro:
Muy nuboso o cubierto, con visibilidad localmente reducida. Precipitaciones débiles o moderadas, que podrían ser persistentes localmente. Cota de nieve en ascenso hasta los 1800-2000 metros. Temperaturas en ascenso, ligero de las mínimas. Heladas débiles, moderadas en cotas altas. Viento fuerte o muy fuerte del norte y noroeste, con rachas en cotas altas y zonas expuestas que podrían superar los 100 km/h.
Pirineo aragonés:
Muy nuboso o cubierto, con visibilidad localmente reducida. Precipitaciones débiles o moderadas, más frecuentes e intensas en la divisoria fronteriza, donde podrían ser localmente persistentes. Cota de nieve en ascenso hasta los 1800-2000 metros. Temperaturas mínimas en ligero ascenso. Máximas en ascenso notable. Heladas débiles, moderadas en cotas altas, donde podrán ser localmente fuertes y persistentes. Viento moderado o fuerte del norte y noroeste, con rachas muy fuertes en cotas altas y zonas expuestas que podrían superar los 100 km/h.

Datos en la atmósfera libre:

Altitud de la isoterma de 0 ºC: 2000 m
Altitud de la isoterma de -10 ºC: 4800 m

Viento a 1500 m: N 30 km/h
Viento a 3000 m: N 100 km/h

Evolución para el martes día 31

Nivel de peligro con pocos cambios.

(Información elaborada a partir de los datos recibidos de los refugios de Lizara, Panticosa, Bachimaña, Góriz, Pineta, Estós, Angel Orús, La Renclusa, Cap de Llauset y Belagua, de las estaciones de esquí de Astún y Panticosa (lagos) y de Ordesa Pradera)

Escala europea de peligro de aludes

Débil | Limitado | Notable | Fuerte | Muy Fuerte

Problemas de aludes

Nieve reciente | Placas de viento | Capas débiles persistentes | Nieve húmeda | Deslizamientos basales | Sin problema evidente

Nota1: Se recuerda que, siempre que haya nieve, la ausencia total de peligro no existe. Hay que tener presente que en circunstancias desfavorables, con aludes de tamaño 1 (alud pequeño o colada) y tamaño 2 (alud mediano), se pueden sufrir severos daños personales.

Nota2: Los BPA se elaboran en base a información meteorológica así como al estado del manto nivoso a través de sondeos puntuales. Se advierte a los usuarios de la variabilidad de esta información al extrapolarla a zonas extensas de montaña. Por ello, AEMET no se hace responsable de su uso para la toma de decisiones que conciernen a la seguridad personal, ni de los riesgos físicos o materiales de ellas derivadas.

AEMET. Se autoriza la reproducción de su contenido citando la fuente.