aineva.it

Montag 30.03.2026

Aktualisiert am 29.03.2026 um 23:42

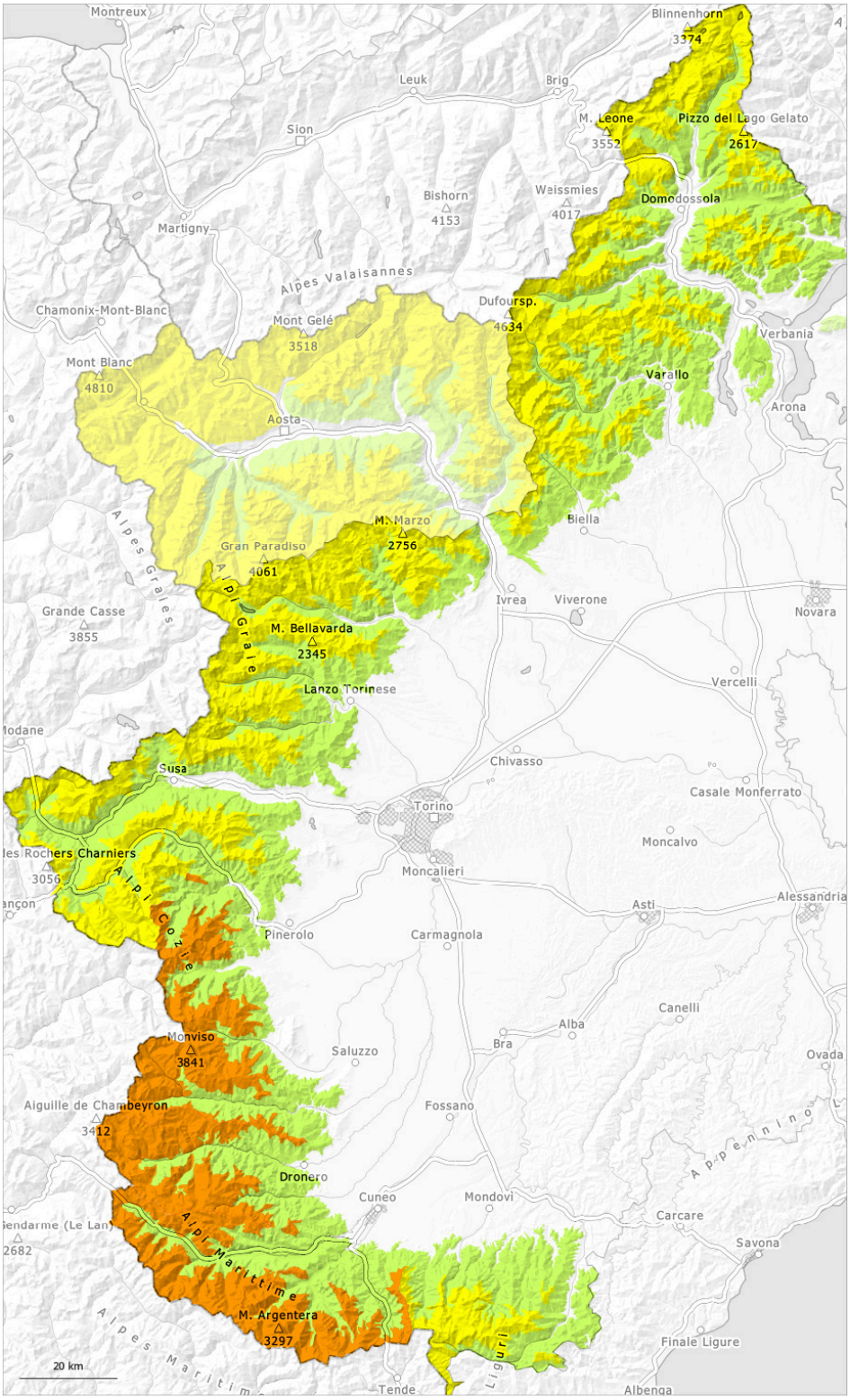

1	2	3	4	5
gering	mäßig	erheblich	groß	sehr groß

Gefahrenstufe 3 - Erheblich

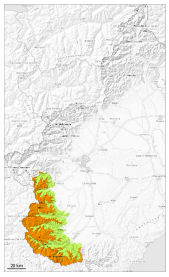

Tendenz: Lawinengefahr bleibt gleich
am Dienstag, den 31.03.2026

Triebschnee

2000m

Mit dem Nordostwind nimmt die Anzahl der Gefahrenstellen im Tagesverlauf zu.

Mit auffrischendem Wind aus nordöstlichen Richtungen entstehen im Tagesverlauf weitere Triebschneeansammlungen. Diese können stellenweise schon von einzelnen Wintersportlern ausgelöst werden.

Die Lawinen können vor allem an steilen Hängen in den verschiedenen Triebschneeschichten anreißen und vereinzelt groß werden.

An sehr steilen Hängen sind mehrere meist kleine spontane trockene Lawinen möglich.

Hohe Lagen und Hochgebirge: Touren erfordern eine vorsichtige Routenwahl.

Schneedecke

Gefahrenmuster gm.6: lockerer schnee und wind

Gestern fielen gebietsweise oberhalb von rund 1600 m 10 bis 15 cm Schnee.

Mit Neuschnee und mäßigem bis starkem Wind aus nordöstlichen Richtungen entstehen weitere Triebschneeansammlungen. Hohe Lagen und Hochgebirge: Verschiedene Triebschneeschichten liegen verbreitet auf einer harten Kruste.

In Gipfellagen liegen je nach Windeinfluss sehr unterschiedliche Schneehöhen.

In der Altschneedecke sind v.a. an Schattenhängen einzelne Schwachschichten vorhanden.

Gefahrenstufe 2 - Mäßig

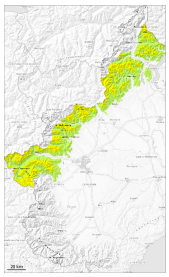

2200m

Tendenz: Lawinengefahr bleibt gleich
am Dienstag, den 31.03.2026

Triebschnee

2200m

Altschnee

2200m

Die Triebschneeansammlungen sind vorsichtig zu beurteilen.

Die harten Triebschneeansammlungen liegen vor allem an Sonnenhängen und in hohen Lagen auf einer Kruste.
Diese können vereinzelt schon von einzelnen Wintersportlern ausgelöst werden und mittlere Größe erreichen. Die Gefahrenstellen liegen vor allem in Rinnen und Mulden sowie an Triebschneehängen.
Entlang der Grenze zu Frankreich ist die Auslösebereitschaft höher.

Schneedecke

Gefahrenmuster gm.6: lockerer schnee und wind

Der Triebschnee liegt verbreitet auf einer harten Kruste, besonders an Sonnenhängen in allen Höhenlagen und in Kamm- und Passlagen in der Höhe.

Hohe Lagen Schattenhänge: Der untere Teil der Schneedecke ist kantig aufgebaut.
Im mittleren Teil der Schneedecke sind besonders an West-, Nord- und Nordosthängen einzelne Schwachschichten vorhanden.

An sonnigeren Hängen, wo die Temperaturen weniger kalt sind, wird die harte Oberfläche der Schneedecke im Tagesverlauf langsam weicher.

V.a. in Kammlagen in hohen Lagen liegen je nach Windeinfluss sehr unterschiedliche Schneehöhen.

Gefahrenstufe 2 - Mäßig

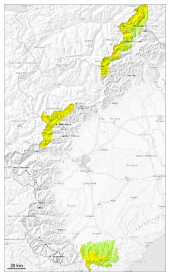

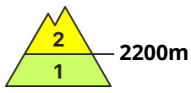

Tendenz: Lawinengefahr bleibt gleich
am Dienstag, den 31.03.2026

Triebschnee

2200m

Einzelne Gefahrenstellen liegen an Triebschneehängen in der Höhe.

Gestern fielen lokal oberhalb von rund 1700 m 5 bis 10 cm Schnee. Mit Neuschnee und Wind aus nordöstlichen Richtungen entstanden eher kleine Triebschneeansammlungen. Diese können stellenweise vor allem mit großer Belastung ausgelöst werden. Die Lawinen können vor allem an Triebschneehängen in den verschiedenen Triebschneeschichten anreißen und mittlere Größe erreichen.

Schneedecke

Gefahrenmuster gm.6: lockerer schnee und wind

Gestern fielen gebietsweise oberhalb von rund 1700 m 5 bis 10 cm Schnee.
Hohe Lagen und Hochgebirge: Verschiedene Triebschneeschichten liegen verbreitet auf einer harten Kruste.

In Gipfellagen liegen je nach Windeinfluss sehr unterschiedliche Schneehöhen.