Montag 30.03.2026

Aktualisiert am 29.03.2026 um 23:42

Vormittag

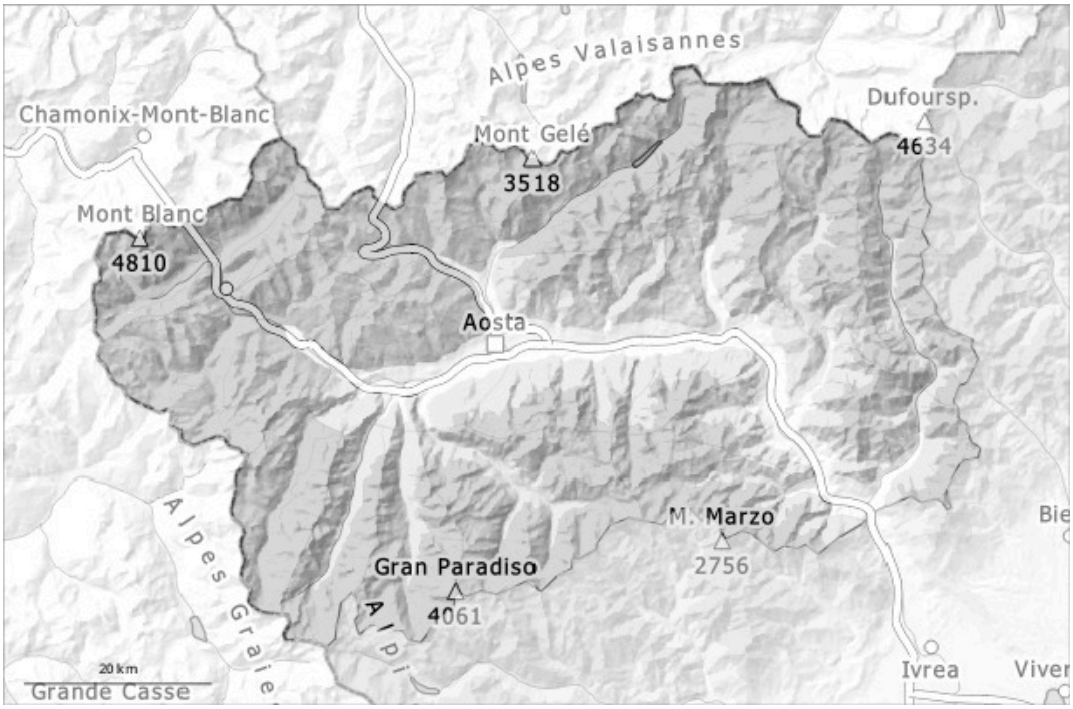

Nachmittag

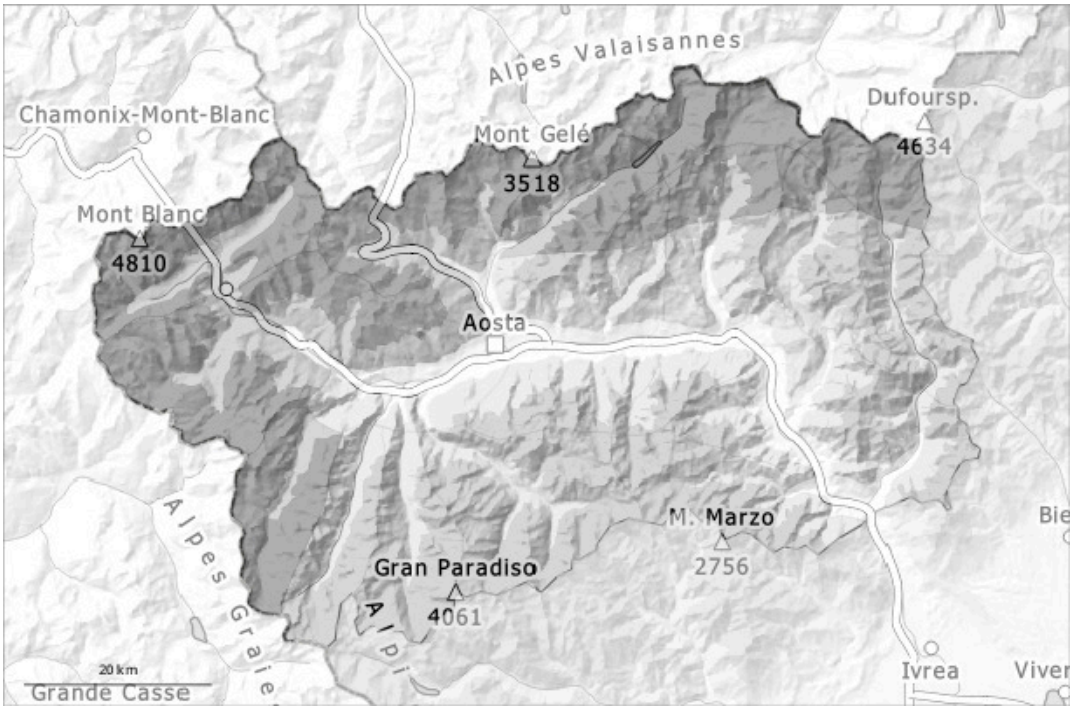

1	2	3	4	5
gering	mäßig	erheblich	groß	sehr groß

Gefahrenstufe 3 - Erheblich

AM:

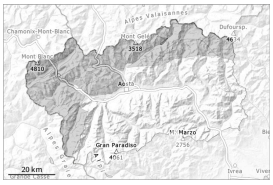

Tendenz: Lawinengefahr bleibt gleich
am Dienstag, den 31.03.2026

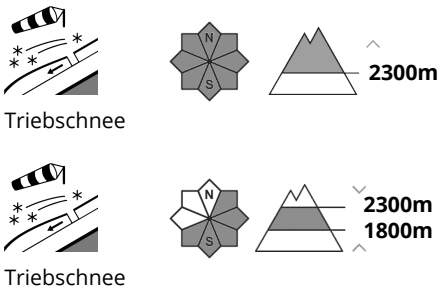

PM:

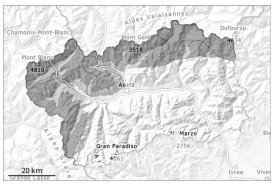

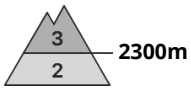

Tendenz: Lawinengefahr bleibt gleich
am Dienstag, den 31.03.2026

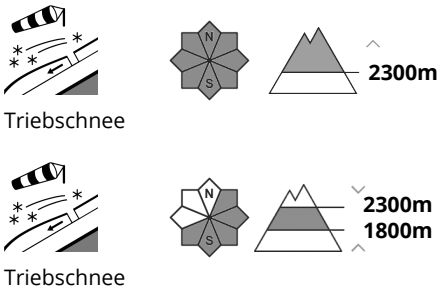

Triebschnee ist die Hauptgefahr. Der Wind bläst stark.

Ab dem Mittag fallen lokal oberhalb von rund 1600 m 5 bis 15 cm Schnee. Der Wind bläst stark. Mit Neuschnee und starkem Wind aus nördlichen Richtungen entstehen auch kammfern weitere Triebschneeansammlungen. Stellenweise wachsen die Triebschneeansammlungen im Tagesverlauf etwas an. Entlang der Grenze zu Frankreich und entlang der Grenze zur Schweiz sind diese Gefahrenstellen häufiger. Sie werden teils überschneit und damit schwierig zu erkennen.
Die frischeren Triebschneeansammlungen können ausgelöst werden, Vorsicht an Übergängen von wenig zu viel Schnee wie z.B. bei der Einfahrt in Rinnen und Mulden. Wummgeräusche sind Alarmzeichen.
Die trockenen Lawinen können besonders an Triebschneehängen in den verschiedenen Triebschneeschichten anreißen und mittlere Größe erreichen.
Touren erfordern Vorsicht und Zurückhaltung.

Schneedecke

Gefahrenmuster gm.6: lockerer schnee und wind

Am Sonntag fielen lokal oberhalb von rund 2000 m 2 bis 5 cm Schnee, lokal auch mehr.
Am Donnerstag fielen oberhalb von rund 2000 m 20 bis 30 cm Schnee, lokal auch weniger. Der Wind blies verbreitet stark bis stürmisch. Der Wind hat Neu- und Altschnee intensiv verfrachtet. Verbreitet liegen je

nach Windeinfluss sehr unterschiedliche Schneehöhen.
Der obere Teil der Schneedecke ist hart, mit einer oft tragfähigen Kruste an der Oberfläche, v.a. in Kamm- und Passlagen.
Der obere Teil der Schneedecke ist weich, mit einer lockeren Oberfläche, besonders in windgeschützten Lagen.
Die Sonneneinstrahlung führte zu einer Setzung der Schneedecke. An Südost- und Südwesthängen unterhalb von rund 2400 m ist der Schnee feucht.
In der Schneedecke sind v.a. an steilen Schattenhängen Schwachschichten vorhanden.

Tendenz

Der Wind bläst stark. Die Gefahrenstellen liegen an Triebschneehängen in der Höhe.

Gefahrenstufe 2 - Mäßig

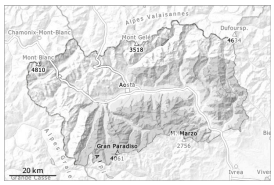

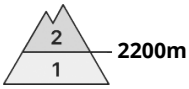

Tendenz: Lawinengefahr bleibt gleich
am Dienstag, den 31.03.2026

Triebschnee

Triebschnee ist die Hauptgefahr.

Ab dem Mittag fallen lokal oberhalb von rund 1600 m 5 bis 10 cm Schnee, lokal auch weniger. Der Wind bläst stark. Stellenweise wachsen die Triebschneeansammlungen im Tagesverlauf etwas an. Diese können stellenweise von einzelnen Wintersportlern ausgelöst werden, Vorsicht an Übergängen von wenig zu viel Schnee wie z.B. bei der Einfahrt in Rinnen und Mulden.
Die trockenen Lawinen können besonders an Triebschneehängen in den verschiedenen Triebschneeschichten anreißen und mittlere Größe erreichen.
Touren erfordern Vorsicht.

Schneedecke

Gefahrenmuster gm.6: lockerer schnee und wind

Am Sonntag fielen lokal oberhalb von rund 2000 m 2 bis 5 cm Schnee, lokal auch weniger.
Am Donnerstag fielen oberhalb von rund 2000 m 5 bis 10 cm Schnee, lokal auch weniger.
Der Wind blies verbreitet stark bis stürmisch. Der Wind hat Neu- und Altschnee intensiv verfrachtet.
Verbreitet liegen je nach Windeinfluss sehr unterschiedliche Schneehöhen.
Der obere Teil der Schneedecke ist hart, mit einer oft tragfähigen Kruste an der Oberfläche, v.a. in Kamm- und Passlagen.
Der obere Teil der Schneedecke ist weich, mit einer lockeren Oberfläche, besonders in windgeschützten Lagen.
Die Sonneneinstrahlung führte zu einer Setzung der Schneedecke. An Südost- und Südwesthängen unterhalb von rund 2400 m ist der Schnee feucht.
In der Schneedecke sind v.a. an steilen Schattenhängen Schwachschichten vorhanden.

Tendenz

Der Wind bläst stark. Die Gefahrenstellen liegen an Triebschneehängen in der Höhe.