ICGC Institut Cartogràfic i Geològic de Catalunya

Servei Meteorològic de Catalunya meteo.cat

Boletín de peligro de aludes para el Pirineo de Catalunya
Del 29/03/2026 al 30/03/2026

(Válido fuera pistas de esquí y zonas no controladas)

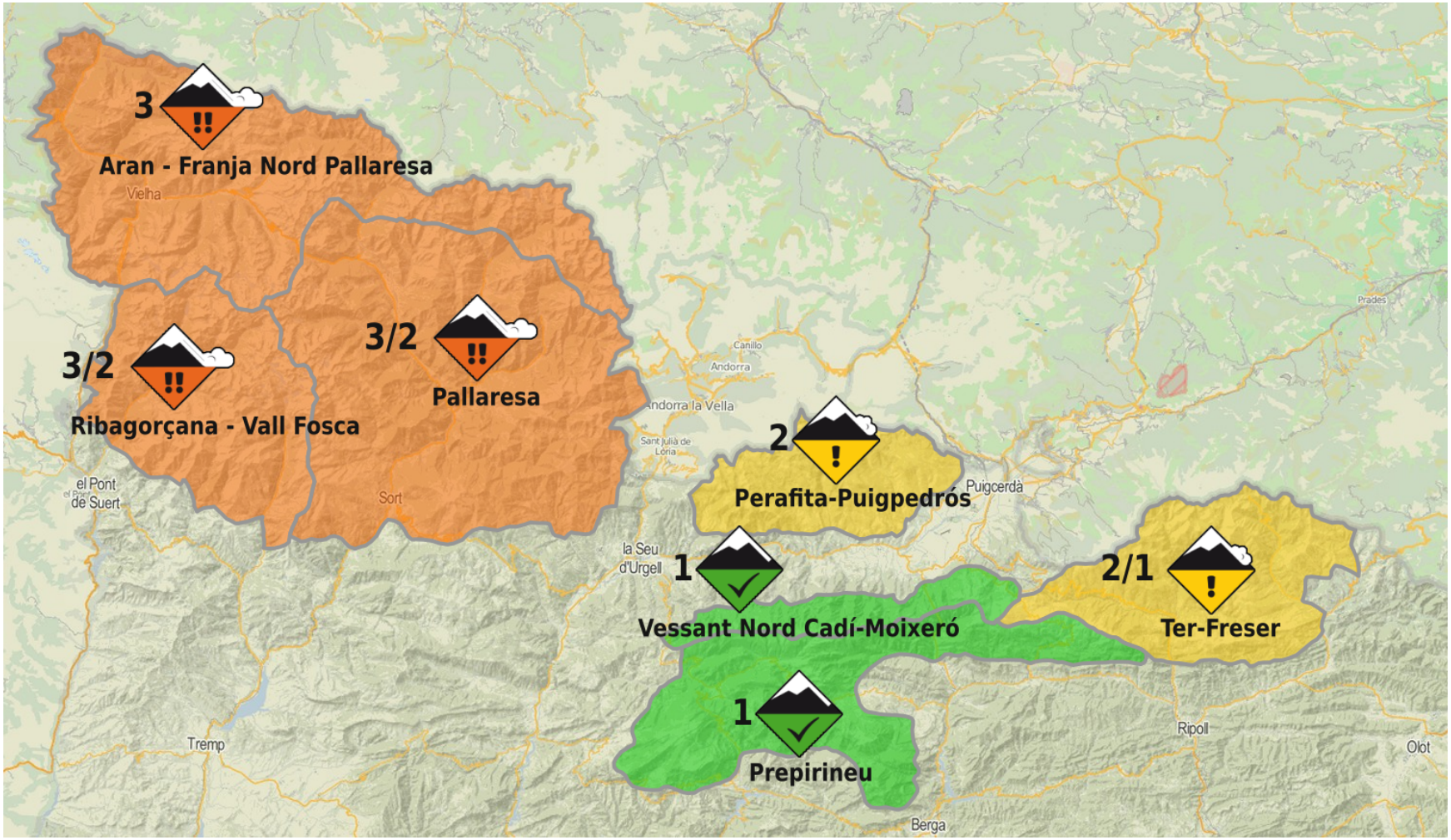

5 MUY FUERTE	4 FUERTE	3 NOTABLE	2 LIMITADO	1 DÉBIL

ICGC Institut Cartogràfic i Geològic de Catalunya

meteo.cat Servei Meteorològic de Catalunya

Boletín de peligro de aludes Aran - Franja Nord Pallaresa Del 29/03/2026 al 30/03/2026

(Válido fuera pistas de esquí y zonas no controladas)

NOTABLE (3)

Situación primaria

Nieve venteada

Distribución

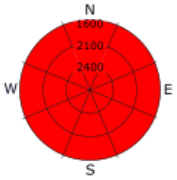

Tamaño

Origen

Tendencia

Situación secundaria

Nieve reciente

Distribución

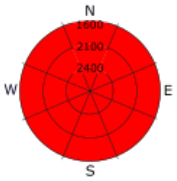

Tamaño

Origen

Tendencia

Estado del manto nivoso

La nevada ha sido importante en todo el sector con un viento muy variable en intensidad según el lugar, de moderado a muy fuerte.

Se han podido formar placas de viento en cualquier cota y orientación, más frecuentes y probables en S y E, en sectores más resguardados del viento intenso. Las placas de nueva formación serán muy sensibles y podrán desencadenarse muy fácilmente de forma accidental e incluso de forma natural. Los aludes de placa alcanzarán tamaño medio en general, localmente hasta tamaño grande, donde las acumulaciones hayan sido mayores o donde impliquen capas débiles internas.

Con el aumento térmico acusado y claros para el lunes, son probables aludes naturales de nieve reciente y reciente húmeda, en cualquier orientación y cota, pero más frecuentes en S, sobre todo en vertientes inclinadas poco afectadas por el viento. Los aludes serían de tamaño medio en general.

Distribución del manto nivoso

Ha nevado hasta cotas bajas de todo el sector. Los espesores a unos 2.200 m son ligeramente superiores a los normales en la Franja Norte de la Pallaresa y en la mitad sur de Arán, donde rondan los 180-240 cm. En la mitad norte de Arán son los normales por estas fechas con unos 130-150 cm de espesor total.

Tendencia para las próximas 48-72h

Continuarán las nevadas y el viento fuerte en los próximos días, manteniendo el manto inestable. Peligro: en leve AUMENTO.

El próximo boletín será emitido el día 2026-03-30

5 MUY FUERTE	4 FUERTE	3 NOTABLE	2 LIMITADO	1 DÉBIL

EAWS EUROPEAN AVALANCHE WARNING SERVICES

ICGC Institut Cartogràfic i Geològic de Catalunya

meteo.cat Servei Meteorològic de Catalunya

Boletín de peligro de aludes Ribagorçana - Vall Fosca Del 29/03/2026 al 30/03/2026

(Válido fuera pistas de esquí y zonas no controladas)

NOTABLE (3) en el extremo norte, LIMITADO (2) en el resto

Situación primaria

Nieve venteada

Distribución

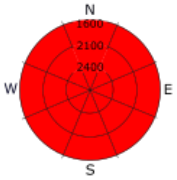

Tamaño

Origen

Tendencia

Situación secundaria

Nieve reciente

Distribución

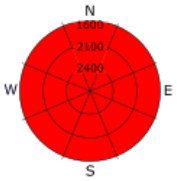

Tamaño

Origen

Tendencia

Estado del manto nivoso

El episodio de nieve y viento, hasta cotas bajas, ha afectado sobre todo al extremo norte del sector, con nevadas importantes y transporte de nieve muy efectivo en los lugares más venteados.

Se han podido formar placas de viento en cualquier orientación y cota, pero más probables y frecuentes en S y E, bajo collados y cordales, y canales y vertientes más resguardados. Estas placas a menudo se han formado sobre un manto con mal contacto. Pueden ser placas muy sensibles, cediendo muy fácilmente al paso de una persona y desecadenándose incluso de forma natural, dando lugar a aludes de tamaño medio en general, localmente hasta tamaño grande en el extremo N.

Con el aumento térmico acusado y claros para el lunes, son probables aludes naturales de nieve reciente y reciente húmeda en laderas inclinadas poco afectadas por el viento. Los aludes serían de tamaño medio en general.

Distribución del manto nivoso

Ha nevado hasta cotas bajas en el extremo norte del sector. Los grosores alcanzan los 100-120 cm a unos 2.200 m. Estos valores se acercan a los normales para la época.

Tendencia para las próximas 48-72h

Continuarán las nevadas y el viento fuerte, sobre todo en el norte del sector, manteniendo el manto inestable. Peligro: en leve AUMENTO.

El próximo boletín será emitido el día 2026-03-30

5 MUY FUERTE	4 FUERTE	3 NOTABLE	2 LIMITADO	1 DÉBIL

EAWS EUROPEAN AVALANCHE WARNING SERVICES

ICGC Institut Cartogràfic i Geològic de Catalunya

meteo.cat Servei Meteorològic de Catalunya

Boletín de peligro de aludes Pallaresa
Del 29/03/2026 al 30/03/2026

(Válido fuera pistas de esquí y zonas no controladas)

NOTABLE (3) en el extremo norte, LIMITADO (2) en el resto

Situación primaria

Nieve venteada

Distribución

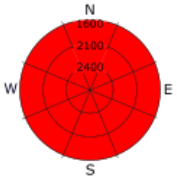

Tamaño

Origen

Tendencia

Situación secundaria

Nieve reciente

Distribución

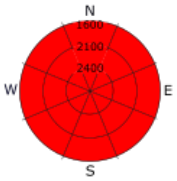

Tamaño

Origen

Tendencia

Estado del manto nivoso

El episodio de nieve y viento, hasta cotas bajas, ha afectado sobre todo al extremo norte del sector, con nevadas importantes y transporte de nieve muy efectivo en los lugares más venteados.

Se han podido formar placas de viento en cualquier orientación y cota, pero más probables y frecuentes en S y E, bajo collados y cordales, y canales y vertientes más resguardados. Estas placas a menudo se han formado sobre un manto con mal contacto. Pueden ser placas muy sensibles, cediendo muy fácilmente al paso de una persona y desecadenándose incluso de forma natural, dando lugar a aludes de tamaño medio en general, localmente hasta tamaño grande en el extremo N.

Con el aumento térmico acusado y claros para el lunes, son probables aludes naturales de nieve reciente y reciente húmeda en laderas inclinadas poco afectadas por el viento. Los aludes serían de tamaño medio en general.

Distribución del manto nivoso

Ha nevado hasta cotas bajas en el extremo norte. Los espesores alcanzan los 110-150 cm en cotas medias, puntualmente más, variable según los efectos del viento.

Tendencia para las próximas 48-72h

Continuarán las nevadas y el viento fuerte, sobre todo en el norte del sector, manteniendo el manto inestable. Peligro: en leve AUMENTO.

El próximo boletín será emitido el día 2026-03-30

5 MUY FUERTE	4 FUERTE	3 NOTABLE	2 LIMITADO	1 DÉBIL

EAWS EUROPEAN AVALANCHE WARNING SERVICES

ICGC Institut Cartogràfic i Geològic de Catalunya

meteo.cat Servei Meteorològic de Catalunya

Boletín de peligro de aludes Perafita-Puigpedrós Del 29/03/2026 al 30/03/2026

(Válido fuera pistas de esquí y zonas no controladas)

LIMITADO (2)

Situación primaria

Nieve venteada

Distribución

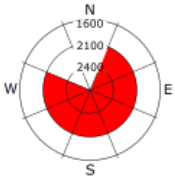

Tamaño

Origen

Tendencia

Situación secundaria

Nieve reciente

Distribución

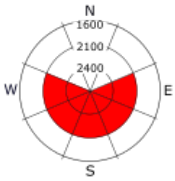

Tamaño

Origen

Tendencia

Estado del manto nivoso

El intenso episodio de viento y nevadas débiles o moderadas en el sector, que puede repetirse el lunes, ha provocado transporte de nieve intenso, con extensos sectores deflactados y sobreacumulaciones locales en lugares más resguardados.

Se mantienen las condiciones de placa de viento, inestables, en las laderas resguardadas, preferentemente por encima del límite de bosque, y bajo collados y crestas no venteadas donde haya predominado la acumulación. Se localizarán sobre todo en orientaciones S y E, menos frecuentes en el resto. Estas placas serán reactivas al paso de una persona, sin descartar desencadenamientos naturales puntualmente, generando aludes de tamaño pequeño o medio en sectores más propicios de sobreacumulación y menos venteados.

Con el aumento térmico acusado y claros para el lunes, son probables purgas pequeñas de nieve reciente y nieve reciente húmeda y caída de bolas, menos probables en orientaciones N, más afectadas por el viento y menos expuestas a la radiación.

Distribución del manto nivoso

Hay nieve por encima de unos 1.900 m, discontinua hasta 2.200 m en solanas. Es esquiable a partir de unos 2.000 m en N. Los espesores, aunque irregulares, rondan los 70-100 cm en umbrías, a 2.300 m. Son grosores por encima de los habituales en esta época.

Tendencia para las próximas 48-72h

La estabilidad del manto no variará demasiado con las débiles precipitaciones y viento fuerte previstos. Peligro: ESTACIONARIO.

El próximo boletín será emitido el día 2026-03-30

5 MUY FUERTE	4 FUERTE	3 NOTABLE	2 LIMITADO	1 DÉBIL

EAWS EUROPEAN AVALANCHE WARNING SERVICES

ICGC Institut Cartogràfic i Geològic de Catalunya

Servei Meteorològic de Catalunya meteo.cat

Boletín de peligro de aludes
Vessant Nord Cadí-Moixeró
Del 29/03/2026 al 30/03/2026

(Válido fuera pistas de esquí y zonas no controladas)

DÉBIL (1)

Situación primaria

Nieve venteada

Distribución

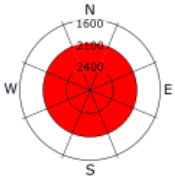

Tamaño

Origen

Tendencia

Situación secundaria

Nieve reciente

Distribución

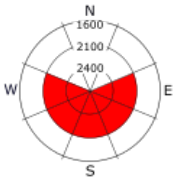

Tamaño

Origen

Tendencia

Estado del manto nivoso

Las nevadas han sido muy débiles en el sector, acompañadas de viento de N-NW, moderado-fuerte en el sector del cadí y muy fuerte en el sector del Moixeró, que ha podido provocar pequeñas sobreacumulaciones de nieve en lugares más resguardados.

Se mantienen las condiciones de placa de viento locales y pequeñas, en las laderas resguardadas, preferentemente por encima del límite de bosque, bajo collados y crestas no venteadas y dentro de las canales resguardadas, donde haya predominado la acumulación. Se localizarán en cualquier orientación pero más probables en S y E. Las placas pueden ser reactivas, fácilmente desencadenables al paso de una persona, puntualmente de forma natural, y serían de pequeño tamaño.

Con el aumento térmico acusado y claros para el lunes, son probables purgas pequeñas de nieve reciente y nieve reciente húmeda y caída de bolas, menos probables en orientaciones N, más afectadas por el viento y menos expuestas a la radiación.

Distribución del manto nivoso

En umbrías hay presencia discontinua de nieve por encima de unos 1.700 m y es esquiable por encima de unos 1.900 m. Los grosores están alrededor de 160-180 cm a 2.200 m. Estos valores son muy excedentarios para la época del año.

Tendencia para las próximas 48-72h

La estabilidad del manto no variará mucho con las débiles precipitaciones y viento fuerte previstos, con alguna pequeña nueva placa. Peligro: ESTACIONARIO.

El próximo boletín será emitido el día 2026-03-30

5 MUY FUERTE	4 FUERTE	3 NOTABLE	2 LIMITADO	1 DÉBIL

EAWS EUROPEAN AVALANCHE WARNING SERVICES

ICGC Institut Cartogràfic i Geològic de Catalunya

meteo.cat Servei Meteorològic de Catalunya

Boletín de peligro de aludes Prepirineu
Del 29/03/2026 al 30/03/2026

(Válido fuera pistas de esquí y zonas no controladas)

DÉBIL (1)

Situación primaria

Nieve venteada

Distribución

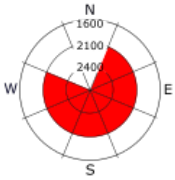

Tamaño

Origen

Tendencia

Situación secundaria

Nieve reciente

Distribución

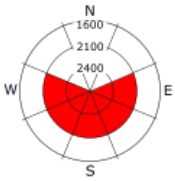

Tamaño

Origen

Tendencia

Estado del manto nivoso

Las nevadas han sido débiles en el sector, acompañadas de viento muy fuerte de NW-N, que ha podido provocar pequeñas sobreacumulaciones de nieve en lugares más resguardados.

Se mantienen las condiciones de placa de viento locales y pequeñas, en las laderas resguardadas, preferentemente por encima del límite de bosque, y bajo collados y crestas no venteadas donde haya predominado la acumulación. Se localizarán sobre todo en orientaciones S y E, menos frecuentes en el resto. Las placas pueden ser reactivas, fácilmente desencadenables al paso de una persona, puntualmente de forma natural, y serían de pequeño tamaño.

Con el aumento térmico acusado y claros para el lunes, son probables purgas muy pequeñas de nieve reciente y reciente húmeda, y caída de bolas, sobre todo en vertientes soleadas inclinadas donde se haya podido acumular nieve reciente del último episodio.

Distribución del manto nivoso

En umbrías hay nieve por encima de unos 1.700 m. En solanas la nieve está presente por encima de unos 1.900 m, discontinua. Los espesores, aunque irregulares, rondan los 90-120 cm a 2.300 m.

Tendencia para las próximas 48-72h

La estabilidad del manto no experimentará variaciones significativas. Peligro: en LEVE DESCENSO.

El próximo boletín será emitido el día 2026-03-30

5 MUY FUERTE	4 FUERTE	3 NOTABLE	2 LIMITADO	1 DÉBIL

EAWS EUROPEAN AVALANCHE WARNING SERVICES

ICGC Institut Cartogràfic i Geològic de Catalunya

Servei Meteorològic de Catalunya

Boletín de peligro de aludes Ter-Freser Del 29/03/2026 al 30/03/2026

(Válido fuera pistas de esquí y zonas no controladas)

LIMITADO (2) por encima del límite de bosque, DÉBIL (1) por debajo

Situación primaria

Nieve venteada

Distribución

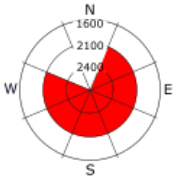

Tamaño

Origen

Tendencia

Situación secundaria

Nieve reciente

Distribución

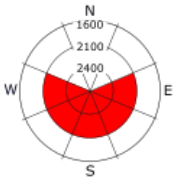

Tamaño

Origen

Tendencia

Estado del manto nivoso

El intenso episodio de viento y nevadas débiles en el sector ha provocado transporte de nieve, con extensos sectores deflactados y sobreacumulaciones locales en lugares más resguardados.

Se mantienen las condiciones de placa de viento, inestables y generalmente pequeñas, en las laderas resguardadas, preferentemente por encima del límite de bosque, y bajo collados y cordales no venteados donde haya predominado la acumulación. Se localizarán sobre todo en orientaciones S y E, menos frecuentes en el resto. Las placas pueden ser reactivas, fácilmente desencadenables al paso de una persona, puntualmente de forma natural, y serían de pequeño tamaño en general, localmente de tamaño medio.

Con el aumento térmico acusado y claros para el lunes, son probables purgas de nieve reciente y reciente húmeda, y caída de bolas, sobre todo en vertientes soleadas inclinadas donde se haya podido acumular nieve reciente del último episodio.

Distribución del manto nivoso

Hay nieve en el suelo por encima de unos 1.700 m. El manto es esquiable en umbrías a partir de unos 1.800 m. Los grosores son muy excedentarios para la época del año y en lugares no afectados por el viento oscilan entre 60-80 cm a unos 2.000 m y más de 150 cm por encima de 2.400 m.

Tendencia para las próximas 48-72h

La estabilidad del manto no variará demasiado con las débiles precipitaciones y viento fuerte previstos. Peligro: ESTACIONARIO.

El próximo boletín será emitido el día 2026-03-30

5 MUY FUERTE	4 FUERTE	3 NOTABLE	2 LIMITADO	1 DÉBIL

EAWS EUROPEAN AVALANCHE WARNING SERVICES