BUTLLETÍ DEL PERILL D'ALLAUS DEL PRINCIPAT D'ANDORRA

Servei meteorològic nacional
Principat d'Andorra

Elaborat el 29/03/2026 16:00
Propera actualització 30/03/2026 a les 16h

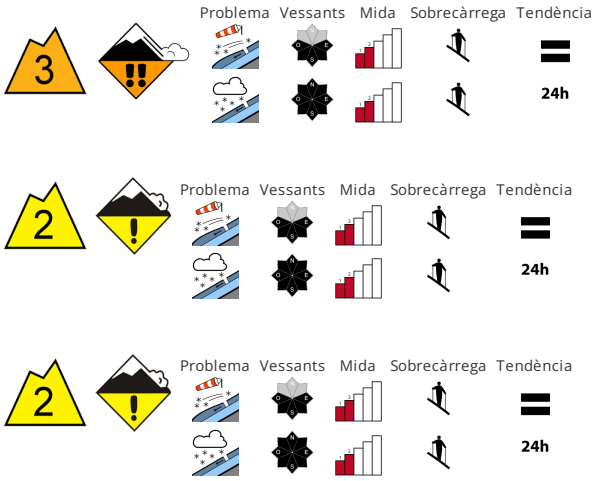

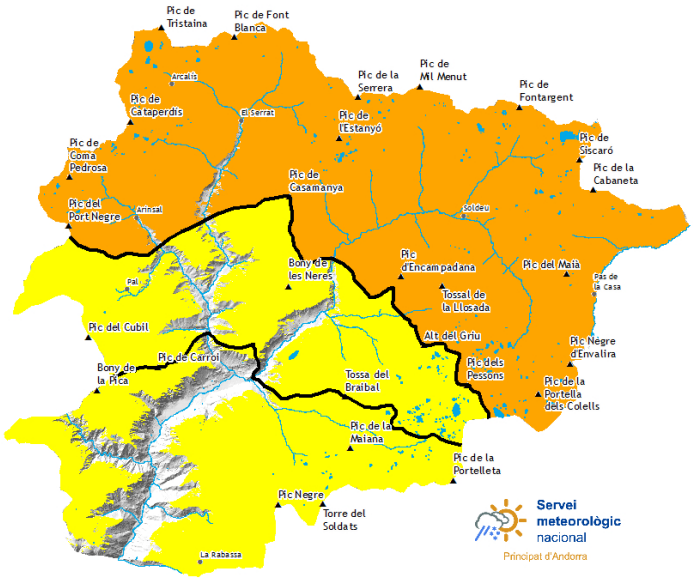

ESTABILITAT DEL MANTELL NIVAL

Les zones de sortida han estat novament carregades a causa de la nevada i el vent. El vent amb ratxes molt fortes transportarà intensament la neu recent i la neu vella. Les condicions per les excursions són en alguns casos desfavorables. Els indrets perillosos es troben en totes les orientacions prop del límit del bosc i també a l'entrada de canals i cubetes. La neu recent i les plaques de vent representen la principal font de perill. Les plaques de vent poden ser desencadenades fàcilment i assolir mida mitjana.

QUALITAT DE LA NEU

Els indrets perillosos són força freqüents i difícils de reconèixer. El mantell de neu roman extremadament variable en pocs metres de manera generalitzada. Prop de les carenes els gruixos de neu varien molt per la influència del vent.

GRUIXOS DEL MANTELL NIVAL FORA DE PISTA

Zona nord		Gruix neu		
Mantell Nival		1500m	2000m	2500m
N	1300 m	10 cm	150 cm	200 cm
S	1500 m	5 cm	100 cm	150 cm

Zona centre		Gruix neu		
Mantell Nival		1500m	2000m	2500m
N	1300 m	10 cm	150 cm	200 cm
S	1500 m	5 cm	100 cm	150 cm

Zona sud		Gruix neu		
Mantell Nival		1500m	2000m	2500m
N	1300 m	10 cm	120 cm	150 cm
S	1500 m	5 cm	60 cm	100 cm

Govern d'Andorra

EAWS EUROPEAN AVALANCHE WARNING SERVICES

Aquest butlletí ha estat elaborat seguint les normes i recomanacions de l'**European Avalanche Warning Services**, del qual el **Servei meteorològic Nacional** n'és membre

BUTLLETÍ DEL PERILL D'ALLAUS DEL PRINCIPAT D'ANDORRA

Servei meteorològic nacional
Principat d'Andorra

Informació detallada per espais naturals protegits

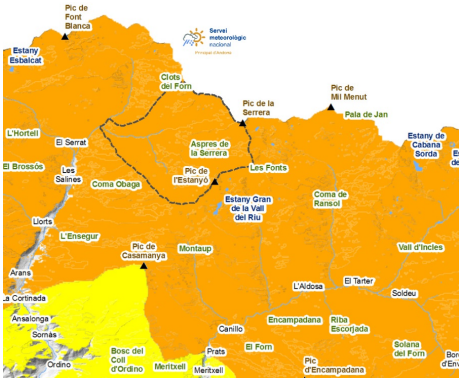

SORTENY

El vent ha modelat la neu recent i ho continuarà fent durant els propers dies, per tant les plaques de vent estaran en constant evolució. A causa del vent que encara bufarà fort en altura durant aquesta primera meitat de Setmana Santa i de les nevades successives que sobretot afectaran el nord d´Andorra, no és recomanable sortir del terreny simple.

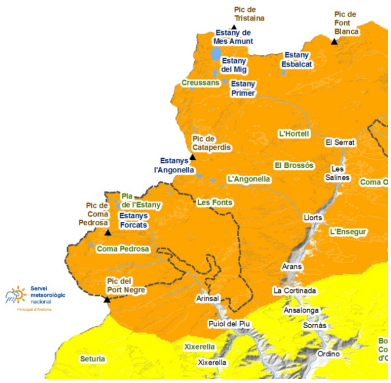

COMAPEDROSA

Es preveu que el vent encara sigui intens en altura durant els propers dies i es continuïn formant plaques de vent.

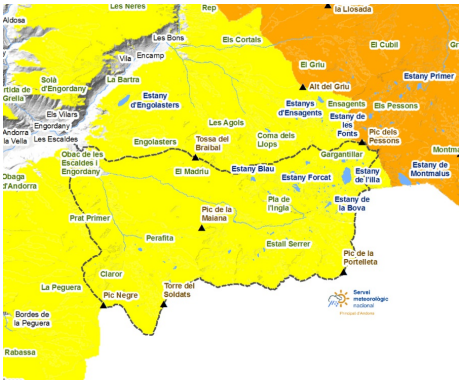

MADRIU-PERAFITA-CLAROR

La neu ha tornat a totes les cotes de la vall, però fins que el vent no amaini no s´aconsellen les excursions a la muntanya.

Govern d'Andorra

EAWS
EUROPEAN AVALANCHE WARNING SERVICES

Aquest butlletí ha estat elaborat seguint les normes i recomanacions de l'**European Avalanche Warning Services**, del qual el **Servei meteorològic Nacional** n'és membre

BUTLLETÍ DEL PERILL D'ALLAUS DEL PRINCIPAT D'ANDORRA

Servei meteorològic nacional
Principat d'Andorra

Gruixos de neu nova dels darrers dies (de les últimes 24h mesurat a les 06:00h UTC)

	25/03/2026	26/03/2026	27/03/2026	28/03/2026
FEDA (Central)	0 cm	0 cm	0 cm	0 cm
Engolasters - FEDA	0 cm	0 cm	0 cm	7 cm
Bony de les Neres	0 cm	0 cm	0 cm	20 cm
Les Fonts d'Arinsal	1 cm	0 cm	0 cm	4 cm
Perafita	0 cm	0 cm	0 cm	0 cm
Tossa Espiolets	0 cm	0 cm	0 cm	34 cm
Grau Roig - FEDA	0 cm	0 cm	0 cm	16 cm
Fontverd	0 cm	0 cm	0 cm	17 cm
Coll Ordino	0 cm	0 cm	0 cm	25 cm
Ransol - FEDA	0 cm	0 cm	0 cm	18 cm
Setúria	0 cm	0 cm	0 cm	21 cm
Caborreu	0 cm	0 cm	0 cm	23 cm
La Solana	2 cm	1 cm	1 cm	30 cm
Coll Pa	4 cm	0 cm	6 cm	21 cm
Envalira Antenes	0 cm	0 cm	0 cm	27 cm
Vall del Riu FEDA	2 cm	0 cm	0 cm	10 cm