BUTLLETÍ DEL PERILL D'ALLAUS DEL PRINCIPAT D'ANDORRA

Elaborado el 29/03/2026 16:00
Proxima actualización 30/03/2026 a las 16h

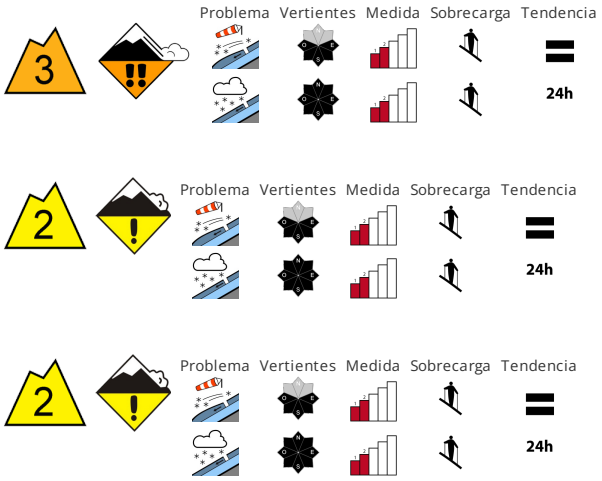

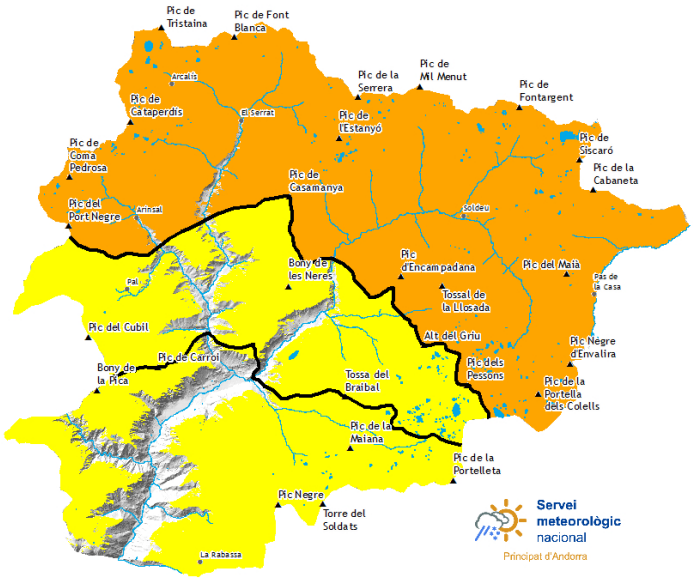

CALIDAD DE LA NIEVE

Las zonas de salida se han visto nuevamente cargadas a causa de la nevada y el viento. El viento con rachas muy fuertes transportará intensamente la nieve reciente y la nieve antigua. Las condiciones para las excursiones son en algunos casos desfavorables. Los lugares peligrosos se encuentran en todas las orientaciones cerca del límite del bosque y en la entrada de canales y cubetas. La nieve reciente y las placas de viento representan la principal fuente de peligro. Las placas de viento pueden ser desencadenadas fácilmente y alcanzar un tamaño mediano.

ESTABILIDAD DEL MANTO NIVOSO

Los lugares peligrosos son bastante frecuentes y resultan difíciles de reconocer. El manto de nieve permanece extremadamente variable en pocos metros en general. Cerca de los cordales los espesores de nieve varían mucho por la influencia del viento.

ESPESORES DEL MANTO NIVOSO FUERA DE PISTA

Zona norte		Espesor nieve		
Manto Nival		1500m	2000m	2500m
N	1300 m	10 cm	150 cm	200 cm
S	1500 m	5 cm	100 cm	150 cm

zona centro		Espesor nieve		
Manto Nival		1500m	2000m	2500m
N	1300 m	10 cm	150 cm	200 cm
S	1500 m	5 cm	100 cm	150 cm

Zona sur		Espesor nieve		
Manto Nival		1500m	2000m	2500m
N	1300 m	10 cm	120 cm	150 cm
S	1500 m	5 cm	60 cm	100 cm

Govern d'Andorra

EAWS EUROPEAN AVALANCHE WARNING SERVICES

Aquest butlletí ha estat elaborat seguint les normes i recomanacions de l'**European Avalanche Warning Services**, del qual el **Servei meteorològic Nacional** n'és membre

Información detallada por espacios naturales protegidos

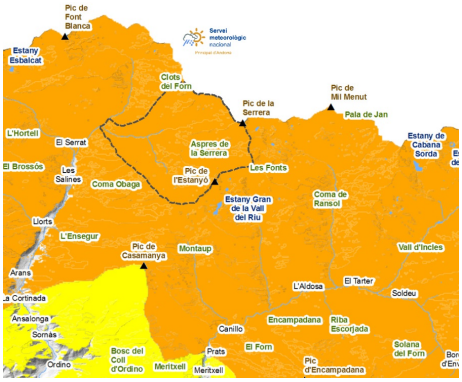

SORTENY

El viento ha moldeado la nieve reciente y lo seguirá haciendo durante los próximos días, por tanto las placas de viento estarán en constante evolución. Debido al viento que aún soplará fuerte en altura durante esta primera mitad de Semana Santa y de las sucesivas nevadas que sobre todo afectarán al norte de Andorra, no es recomendable salir del terreno simple.

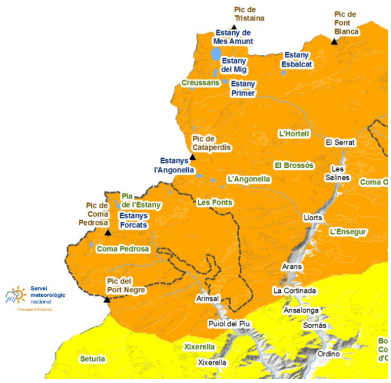

COMAPEDROSA

Se prevé que el viento sea aún intenso en altura durante los próximos días y se sigan formando placas de viento.

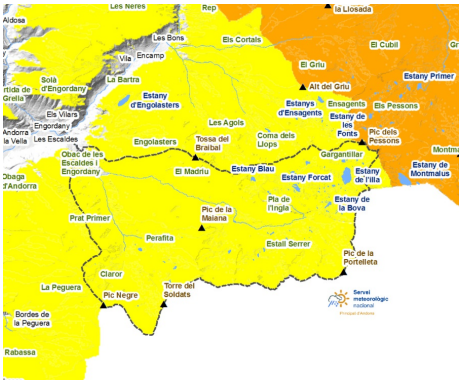

MADRIU-PERAFITA-CLAROR

La nieve ha vuelto a todas las cotas del valle, pero hasta que el viento no amaine no se aconsejan las excursiones a la montaña.

BUTLLETÍ DEL PERILL D'ALLAUS DEL PRINCIPAT D'ANDORRA

Servei meteorològic nacional
Principat d'Andorra

Espesores de nieve nueva de los últimos días (de las ultimas 24h mesurado a las 06:00h UTC)

	25/03/2026	26/03/2026	27/03/2026	28/03/2026
FEDA (Central)	0 cm	0 cm	0 cm	0 cm
Engolasters - FEDA	0 cm	0 cm	0 cm	7 cm
Bony de les Neres	0 cm	0 cm	0 cm	20 cm
Les Fonts d'Arinsal	1 cm	0 cm	0 cm	4 cm
Perafita	0 cm	0 cm	0 cm	0 cm
Tossa Espiolets	0 cm	0 cm	0 cm	34 cm
Grau Roig - FEDA	0 cm	0 cm	0 cm	16 cm
Fontverd	0 cm	0 cm	0 cm	17 cm
Coll Ordino	0 cm	0 cm	0 cm	25 cm
Ransol - FEDA	0 cm	0 cm	0 cm	18 cm
Setúria	0 cm	0 cm	0 cm	21 cm
Caborreu	0 cm	0 cm	0 cm	23 cm
La Solana	2 cm	1 cm	1 cm	30 cm
Coll Pa	4 cm	0 cm	6 cm	21 cm
Envalira Antenes	0 cm	0 cm	0 cm	27 cm
Vall del Riu FEDA	2 cm	0 cm	0 cm	10 cm