BUTLLETÍ DEL PERILL D'ALLAUS DEL PRINCIPAT D'ANDORRA

Servei meteorològic nacional
Principat d'Andorra

Préparé le 29/03/2026 16:00
Prochaine mise à jour le 30/03/2026 à 16h

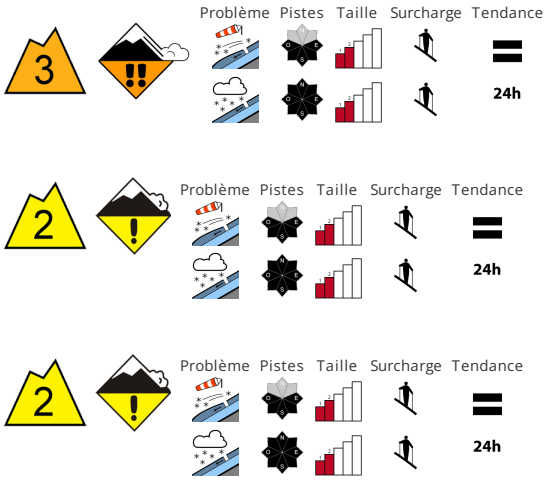

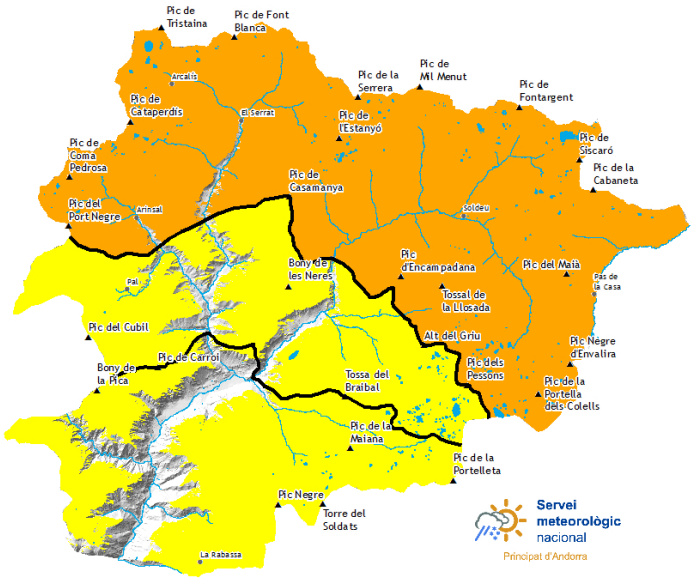

STABILITÉ DU MANTEAU NEIGEUX

Les zones de départ ont été à nouveau rechargées avec les chutes de neige et le vent. Le vent parfois tempétueux transporte la neige fraîche et ancienne de manière intensive.. Les conditions de randonnées sont partiellement défavorables. Les endroits dangereux se situent à toutes les expositions dans la zone de la limite de la forêt ainsi qu'aux transitions vers les combes et couloirs. La neige fraîche et les accumulations de neige soufflée constituent le danger principal. Les accumulations de neige soufflée peuvent peut être déchaîné facilement et atteindre une taille moyenne..

QUALITÈ DE LA NEIGE

Les endroits dangereux sont assez fréquents et difficilement identifiables.. De manière généralisée le manteau neigeux reste très variable à petite échelle.. À proximité des crêtes on trouve suivant l'influence du vent des hauteurs de neiges très différentes.

EPAISSEUR DE NEIGE HORS PISTE

Zone nord		Epaisseur de neige		
Nival manteau		1500m	2000m	2500m
N	1300 m	10 cm	150 cm	200 cm
S	1500 m	5 cm	100 cm	150 cm

Zone centre		Epaisseur de neige		
Nival manteau		1500m	2000m	2500m
N	1300 m	10 cm	150 cm	200 cm
S	1500 m	5 cm	100 cm	150 cm

Zone sud		Epaisseur de neige		
Nival manteau		1500m	2000m	2500m
N	1300 m	10 cm	120 cm	150 cm
S	1500 m	5 cm	60 cm	100 cm

Govern d'Andorra

EAWS EUROPEAN AVALANCHE WARNING SERVICES

Aquest butlletí ha estat elaborat seguint les normes i recomanacions de l'**European Avalanche Warning Services**, del qual el **Servei meteorològic Nacional** n'és membre

BUTLLETÍ DEL PERILL D'ALLAUS DEL PRINCIPAT D'ANDORRA

Servei meteorològic nacional
Principat d'Andorra

Des informations détaillées par espace naturel protégé

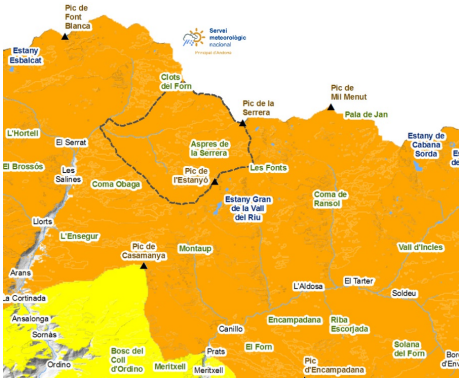

SORTENY

Le vent a façonné la neige récente et continuera de le faire au cours des prochains jours, les zones de vent seront donc en constante évolution. En raison du vent qui soufflera encore fort en altitude durant cette première moitié de la Semaine Sainte et des chutes de neige successives qui affecteront principalement le nord d'Andorre, il n'est pas recommandé de quitter le terrain plat. , , ,

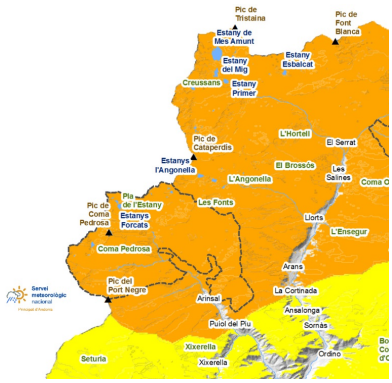

COMAPEDROSA

On s'attend à ce que le vent soit encore fort en altitude au cours des prochains jours et que des plaques de vent continuent de se former. ,

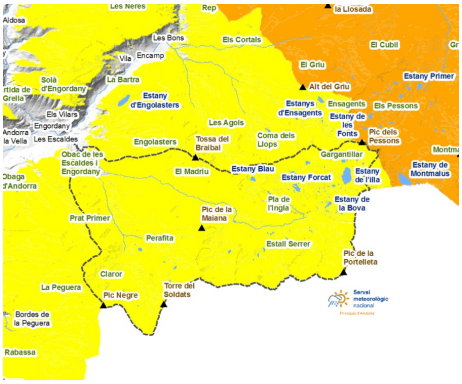

MADRIU-PERAFITA-CLAROR

La neige est revenue à toutes les altitudes de la vallée, mais jusqu'à ce que le vent se calme, il n'est pas conseillé de faire de la randonnée en montagne. ,

Govern d'Andorra

EAWS
EUROPEAN AVALANCHE WARNING SERVICES

Aquest butlletí ha estat elaborat seguint les normes i recomanacions de l'**European Avalanche Warning Services**, del qual el **Servei meteorològic Nacional** n'és membre

BUTLLETÍ DEL PERILL D'ALLAUS DEL PRINCIPAT D'ANDORRA

Servei meteorològic nacional
Principat d'Andorra

Couche de neige fraiche des derniers jours (De 24 h mesurée à 06:00 h UTC)

	25/03/2026	26/03/2026	27/03/2026	28/03/2026
FEDA (Central)	0 cm	0 cm	0 cm	0 cm
Engolasters - FEDA	0 cm	0 cm	0 cm	7 cm
Bony de les Neres	0 cm	0 cm	0 cm	20 cm
Les Fonts d'Arinsal	1 cm	0 cm	0 cm	4 cm
Perafita	0 cm	0 cm	0 cm	0 cm
Tossa Espiolets	0 cm	0 cm	0 cm	34 cm
Grau Roig - FEDA	0 cm	0 cm	0 cm	16 cm
Fontverd	0 cm	0 cm	0 cm	17 cm
Coll Ordino	0 cm	0 cm	0 cm	25 cm
Ransol - FEDA	0 cm	0 cm	0 cm	18 cm
Setúria	0 cm	0 cm	0 cm	21 cm
Caborreu	0 cm	0 cm	0 cm	23 cm
La Solana	2 cm	1 cm	1 cm	30 cm
Coll Pa	4 cm	0 cm	6 cm	21 cm
Envalira Antenes	0 cm	0 cm	0 cm	27 cm
Vall del Riu FEDA	2 cm	0 cm	0 cm	10 cm