MINISTERO DELLA DIFESA

meteomont Servizio Nazionale di previsione neve e valanghe

EAWS EUROPEAN AVALANCHE WARNING SERVICES

CARABINIERI

In collaborazione con: arpav

# PREALPI

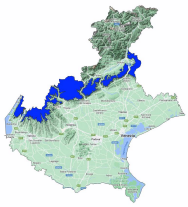

Bollettino Valanghe N. 385/2026 del 29/03/2026 ore 14.00
Validità 48 ore prossima emissione 30/03/2026

**A cura del Servizio METEOMONT dell'ARMA dei CARABINIERI**
**In collaborazione con Servizio Meteorologico dell'Aeronautica militare**

## SITUAZIONE alle 14:00 del 29/03/2026

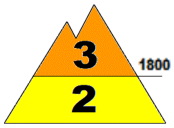


**SITUAZIONE TIPO: neve a debole coesione e vento.**

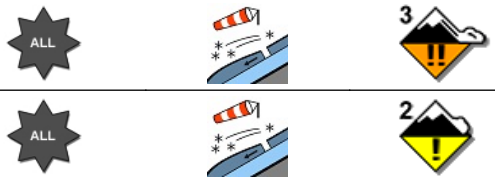


**SITUAZIONE TIPO: neve a debole coesione e vento.**

| Quota neve (mslm) | Nord | Sud |
|---|---|---|
| | 1200 - 1400 | 1400 - 1800 |

| Altezza Neve (cm) | Neve al suolo | Neve Fresca | Quota (mslm) |
|---|---|---|---|
| | 90 | 000 | 2000 |
| | 60 | 000 | 1550 |

**VALANGHE OSSERVATE: Nessuna valanga.**

## PREVISIONI 30/03/2026

# GRADO DI PERICOLO: MARCATO 3

## SITUAZIONE TIPO: neve a debole coesione e vento.

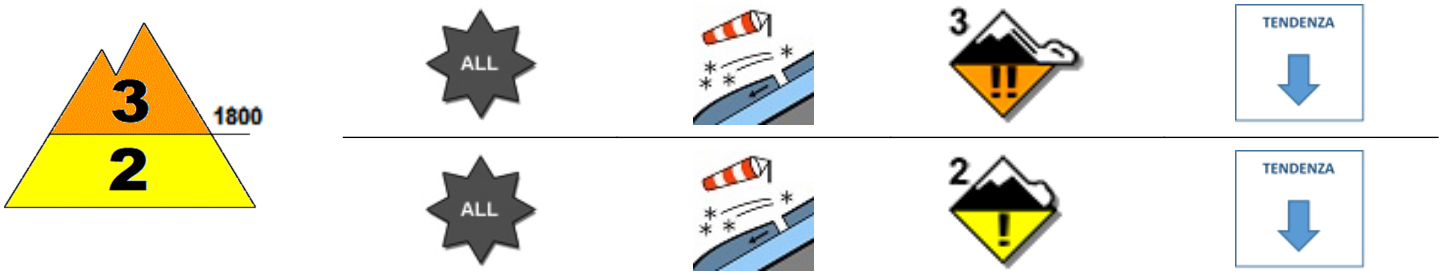


## SITUAZIONE TIPO: neve a debole coesione e vento.

**MANTO NEVOSO: La stabilità del manto nevoso è scarsa su alcuni punti (aree) per tutte le esposizioni al di sopra di 1800 mslm, possibili valanghe di dimensioni grandi.**
**La stabilità del manto nevoso è scarsa su pochi punti (aree) per tutte le esposizioni al di sotto di 1800 mslm, possibili valanghe di dimensioni grandi.**

## AVVERTENZE

In considerazione degli importanti accumuli di neve ventata in conche, canaloni, cambi di pendenza e pendii sotto vento in genere, è richiesta un'ottima valutazione locale della stabilità ed individuazione dell'itinerario.

## SCALA EUROPEA DEL GRADO DI PERICOLO VALANGHE

## LEGENDA PROBLEMA

**Bollettino realizzato su scala sinottica-regionale (standard EAWS). La sua valutazione non può escludere in alcun modo la necessità di una seria e capace valutazione locale del pericolo (singolo pendio) che può essere anche sensibilmente diverso. Le previsioni meteorologiche sono relative all'orario UTC (per l'Italia +1 in inverno e +2 in estate).**

MINISTERO DELLA DIFESA

meteomont
Servizio Nazionale di previsione neve e valanghe

EAWS EUROPEAN AVALANCHE WARNING SERVICES

CARABINIERI

In collaborazione con: arpav

# PREALPI

## PREVISIONE METEO

| Quota | | 30/03/2026 h6:00 | 30/03/2026 h12:00 | 30/03/2026 h18:00 |
|---|---|---|---|---|
| 1000 | Venti | 02 Nodi da N-Est | 02 nodi da N-Ovest | 03 Nodi da N-Est |
| | Temperature | +01 °C | +07 °C | +04 °C |
| | Temp.percepita | 1 °C | 7 °C | 3 °C |
| 2000 | Venti | 03 nodi da Ovest | 04 nodi da N-Ovest | 13 Nodi da Nord |
| | Temperature | -03 °C | -02 °C | -03 °C |
| | Temp.percepita | -5 °C | -5 °C | -10 °C |
| 3000 | Venti | 08 nodi da N-Ovest | 12 Nodi da Nord | 16 Nodi da Nord |
| | Temperature | -09 °C | -10 °C | -11 °C |
| | Temp.percepita | -15 °C | -18 °C | -21 °C |
| Zero termico | | 1400-1600 m. | 1700-1900 m. | 1500-1700 m. |
| Fenomeno | | — | — | — |
| Stato del cielo | | | | |

## LEGENDA FENOMENI

— Assenza Fenomeni · Nebbia · Foschia · Pioggia debole · Pioggia moderata · Pioggia forte · Temporali

Nevicata debole · Nevicata moderata · Nevicata forte

## STATO DEL CIELO

Sereno · Poco nuvoloso · Nuvoloso · Molto nuvoloso · Coperto

## Parametri meteonivometrici registrati presso i campi di rilevamento il 29/03/2026.

| Località | Comune | Quota (m.s.l.m.) | Altezza neve (cm) | Neve caduta nelle 24 ore (cm) | Temp. Min (°C) | Temp. Max (°C) | Condizioni del tempo |
|---|---|---|---|---|---|---|---|
| MONTE PIZZOC * | Fregona (TV) | 1468 | 29 | N.P. | N.P. | N.P. | Assenza di precipitazioni |
| PIAN CANSIGLIO | Tambre (BL) | 1025 | 0 | 0 | N.P. | N.P. | Assenza di precipitazioni |
| GALLIO - BUSA FONDA | Gallio (VI) | 1460 | 45 | 0 | -5 | +13 | Assenza di precipitazioni |

(*) Rilievi fuori campo

**L'INFORMAZIONE E' PREVENZIONE - LEGGI L'ATTUALE GRADO DI PERICOLO VALANGHE!**

**IL CAPO DEL CENTRO NAZIONALE METEOMONT**
**(Ten. Col. RFI Emanuela Gini)**
**FIRMA AUTOGRAFA OMESSA AI SENSI**
**DELL'ART.3 DEL D.LGS N.39/1993**

Bollettino realizzato su scala sinottica-regionale (standard EAWS). La sua valutazione non può escludere in alcun modo la necessità di una seria e capace valutazione locale del pericolo (singolo pendio) che può essere anche sensibilmente diverso. Le previsioni meteorologiche sono relative all'orario UTC (per l'Italia +1 in inverno e +2 in estate).