MINISTERO DELLA DIFESA

meteomont
Servizio Nazionale di previsione neve e valanghe

EAWS EUROPEAN AVALANCHE WARNING SERVICES

CARABINIERI

AERONAUTICA MILITARE SERVIZIO METEOROLOGICO

# ALPI OROBICHE

Bollettino Valanghe N. 388/2026 del 29/03/2026 ore 14.00
Validità 48 ore prossima emissione 30/03/2026

**A cura del Servizio METEOMONT dell'ARMA dei CARABINIERI**
**In collaborazione con Servizio Meteorologico dell'Aeronautica militare**

## SITUAZIONE alle 14:00 del 29/03/2026

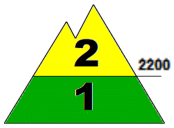


**SITUAZIONE TIPO: neve a debole coesione e vento.**

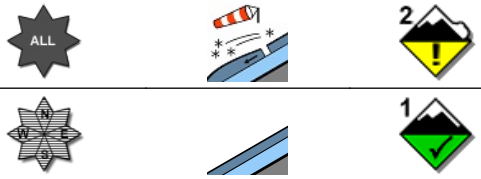


**SITUAZIONE TIPO: nessuna situazione tipo evidente.**

| Quota neve (mslm) | Nord | Sud |
|---|---|---|
| | 1500 - 1600 | 1900 - 2200 |

| Altezza Neve (cm) | Neve al suolo | Neve Fresca | Quota (mslm) |
|---|---|---|---|
| | 155 | 0 | 2080 |
| | 60 | 0 | 1750 |

**VALANGHE OSSERVATE: Nessuna valanga.**

## PREVISIONI 30/03/2026

## GRADO DI PERICOLO: MODERATO 2

## SITUAZIONE TIPO: neve a debole coesione e vento.

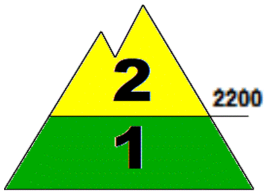


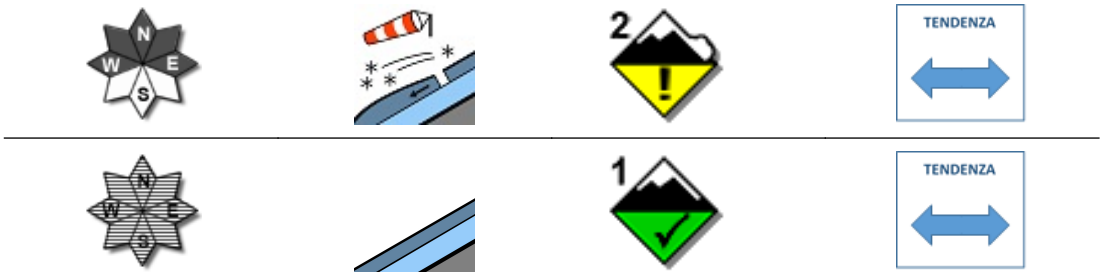


## SITUAZIONE TIPO: nessuna situazione tipo evidente.

**MANTO NEVOSO: La stabilità del manto nevoso è scarsa su pochi punti (aree) per versanti da ovest a est al di sopra di 2200 mslm, possibili valanghe di dimensioni grandi.**
**La stabilità del manto nevoso è discreta su pochissimi punti (aree) per isolati pendii al di sotto di 2200 mslm, possibili valanghe di dimensioni medie.**

## AVVERTENZE

A seguito dell'attività eolica registrata sono da evitare le zone di accumulo, conche, canaloni, cambi di pendenza e pendii sotto vento in genere.

## SCALA EUROPEA DEL GRADO DI PERICOLO VALANGHE

5 - MOLTO FORTE | 4 - FORTE | 3 - MARCATO | 2 - MODERATO | 1 - DEBOLE | NO NEVE | NO INFO

## LEGENDA PROBLEMA

NEVE FRESCA | LASTRONI DA VENTO | STRATI DEBOLI PERSISTENTI | NEVE BAGNATA | SLITTAMENTO | CORNICI | NESSUN PROBLEMA VALANGHIVO EVIDENTE | NO_INFO

**Bollettino realizzato su scala sinottica-regionale (standard EAWS). La sua valutazione non può escludere in alcun modo la necessità di una seria e capace valutazione locale del pericolo (singolo pendio) che può essere anche sensibilmente diverso. Le previsioni meteorologiche sono relative all'orario UTC (per l'Italia +1 in inverno e +2 in estate).**

MINISTERO DELLA DIFESA

meteomont
Servizio Nazionale di previsione neve e valanghe

EAWS EUROPEAN AVALANCHE WARNING SERVICES

CARABINIERI

# ALPI OROBICHE

## PREVISIONE METEO

| Quota | | 30/03/2026 h6:00 | 30/03/2026 h12:00 | 30/03/2026 h18:00 |
|---|---|---|---|---|
| 1000 | Venti | 03 Nodi da Nord | 04 nodi da N-Ovest | 04 Nodi da Nord |
| | Temperature | -03 °C | +00 °C | -04 °C |
| | Temp.percepita | -5 °C | -3 °C | -7 °C |
| 2000 | Venti | 06 Nodi da Nord | 11 nodi da N-Ovest | 10 Nodi da Nord |
| | Temperature | -03 °C | -02 °C | -05 °C |
| | Temp.percepita | -7 °C | -8 °C | -11 °C |
| 3000 | Venti | 09 nodi da N-Ovest | 16 Nodi da Nord | 20 Nodi da Nord |
| | Temperature | -08 °C | -11 °C | -12 °C |
| | Temp.percepita | -15 °C | -21 °C | -23 °C |
| Zero termico | | 1200-1400 m. | 1400-1600 m. | 1100-1300 m. |
| Fenomeno | | — | — | — |
| Stato del cielo | | | | |

## LEGENDA FENOMENI

— Assenza Fenomeni · Nebbia · Foschia · Pioggia debole · Pioggia moderata · Pioggia forte · Temporali

Nevicata debole · Nevicata moderata · Nevicata forte

## STATO DEL CIELO

Sereno · Poco nuvoloso · Nuvoloso · Molto nuvoloso · Coperto

## Parametri meteonivometrici registrati presso i campi di rilevamento il 29/03/2026.

| Località | Comune | Quota (m.s.l.m.) | Altezza neve (cm) | Neve caduta nelle 24 ore (cm) | Temp. Min (°C) | Temp. Max (°C) | Condizioni del tempo |
|---|---|---|---|---|---|---|---|
| QUARTA BAITA | Foppolo (BG) | 1760 | 61 | 0 | -3 | -1 | Assenza di precipitazioni |
| CIMA BIANCA | Colere (BG) | 2080 | 155 | 0 | -4 | 0 | Assenza di precipitazioni |

(*) Rilievi fuori campo

**L'INFORMAZIONE E' PREVENZIONE - LEGGI L'ATTUALE GRADO DI PERICOLO VALANGHE!**

IL CAPO DEL CENTRO NAZIONALE METEOMONT
(Ten. Col. RFI Emanuela Gini)
FIRMA AUTOGRAFA OMESSA AI SENSI
DELL'ART.3 DEL D.LGS N.39/1993

Bollettino realizzato su scala sinottica-regionale (standard EAWS). La sua valutazione non può escludere in alcun modo la necessità di una seria e capace valutazione locale del pericolo (singolo pendio) che può essere anche sensibilmente diverso. Le previsioni meteorologiche sono relative all'orario UTC (per l'Italia +1 in inverno e +2 in estate).