Bulletin d'estimation du risque d'avalanche
(valable en dehors des pistes balisées et ouvertes)

MASSIF : Mercantour

Rédigé le dimanche 29 mars 2026 à 15h

Estimation des risques pour le : LUNDI 30 MARS

RARES INSTABILITÉS EN ALTITUDE, DANS LA NEIGE VENTÉE

2

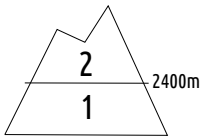

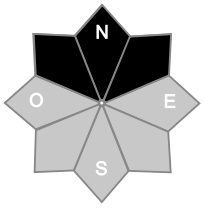

Au-dessus de 2400m indice de risque limité, plus bas indice faible.

Départs spontanés : rares et à haute altitude, en neige ventée

Déclenchements provoqués : instabilités de surface dans la neige ventée

Indices de risque : 5 très fort - 4 fort - 3 marqué - 2 limité - 1 faible -- En noir : les pentes les plus dangereuses

Stabilité du manteau neigeux

Situation avalancheuse typique : neige ventée

Déclenchements provoqués : instabilités limitées à de rares pentes d'altitude. Possibles surtout en large orientation nord au-dessus de 2400 m environ, parfois à distance des crêtes, ces instabilités sont plutôt bien identifiables dans la neige ventée. Un seul skieur peut parfois les déclencher, générant une avalanche de petite taille. Le vent souffle de plus en plus fort au fil des heures, mais ne mobilise que de faibles quantités de neige.

Départs spontanés : rares et restant peu volumineux dans les secteurs d'accumulation par le vent en altitude. Taille généralement petite.

Qualité de la neige

Enneigement plutôt excédentaire pour une fin mars.
Hauteurs de neige observées : 154 cm à la Nivôse de Millefonts à 2430 m, 108 cm à Isola 2000 à 1912 m.

Enneigement skiable : vers 1400/1500 m en terrain favorable en ubacs, 1800/1900 m en adrets peu pentus.

État de la neige en surface : manteau neigeux printanier en adrets, durcis par le vent en ubacs d'altitude. En journée de lundi, humidification restant superficielle avec le redoux temporaire et les éclaircies.

Aperçu météo pour le lundi 30 mars

	nuit	matin	après-midi	soir
Ensoleillé et doux, vent fort à haute altitude, surtout en fin de journée				
Pluie-Neige				
Iso 0 °C	2 200 m	2 600 m	2 700 m	2 200 m
Vent 2000 m	25 km/h	20 km/h	30 km/h	55 km/h
Vent 3000 m	40 km/h	50 km/h	50 km/h	90 km/h

Épaisseur de neige hors-piste

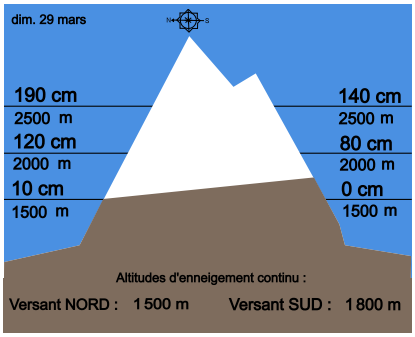

Précipitations à 1800 m

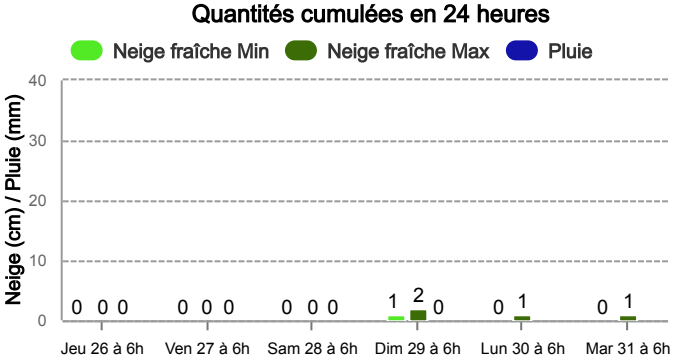

Tendance du mardi 31 mars

2

Indice de risque limité

Peu d'évolution de la situation nivologique. De rares instabilités persistent en altitude dans la neige ventée. Risque limité.

Pour consulter la vigilance en cours, veuillez vous rendre sur le site https://vigilance.meteofrance.fr/fr

Météo-France - 73 avenue de Paris, 94165 Saint-Mandé cedex - Contact : contact@meteo.fr

Rédigé par Météo-France avec la contribution des observateurs du réseau nivo-météorologiques. Partenariat : ANMSM (Maires de Stations de Montagne), DSF (Domaines Skiables de France), ADSP (Directeurs de Pistes et de la Sécurité des Stations de Sports d'Hiver) et autres acteurs de la montagne.

Bulletin neige & avalanches par téléphone au 0 892 68 10 20 Service 0,35 € / min + prix appel

RÉPUBLIQUE FRANÇAISE
Liberté Égalité Fraternité

METEO FRANCE
À VOS CÔTÉS, DANS UN CLIMAT QUI CHANGE

Bulletin d'estimation du risque d'avalanche
(valable en dehors des pistes balisées et ouvertes)

MASSIF : Mercantour

Rédigé le dimanche 29 mars 2026 à 15h

Conditions nivo-météo des 7 derniers jours

	lun. 23/03				mar. 24/03				mer. 25/03				jeu. 26/03				ven. 27/03				sam. 28/03				dim. 29/03			
	03h	09h	15h	21h	03h	09h	15h	21h	03h	09h	15h	21h	03h	09h	15h	21h	03h	09h	15h	21h	03h	09h	15h	21h	03h	09h	15h	21h
Météo																												
Vent (km/h)	40	30	35	40	20	10	15	20	30	40	70	100	100	80	70	60	55	50	40	30	25	25	25	25	40	35	35	15
à 3000m																												
Vent (km/h)	30	20	25	25	20	10	10	10	10	20	50	80	80	65	65	60	60	65	40	25	10	15	20	20	30	30	20	10
à 2000m																												

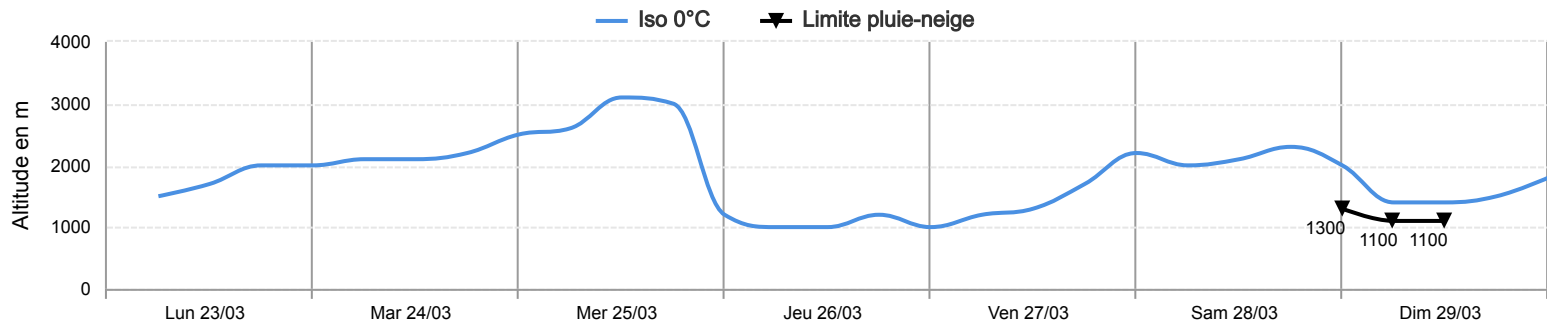

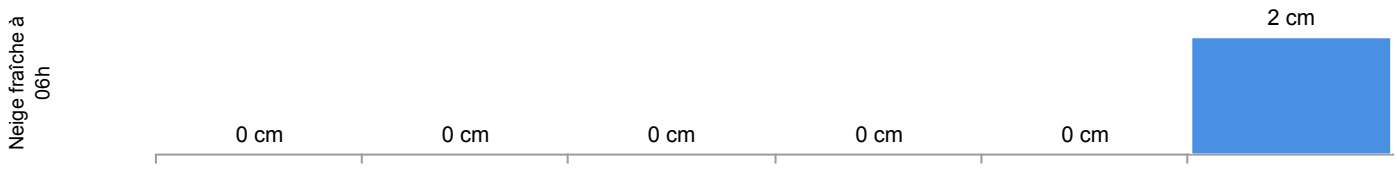

Risque d'avalanche	lun. 23/03	mar. 24/03	mer. 25/03	jeu. 26/03	ven. 27/03	sam. 28/03	dim. 29/03
	3	2	2	3	2	2	2

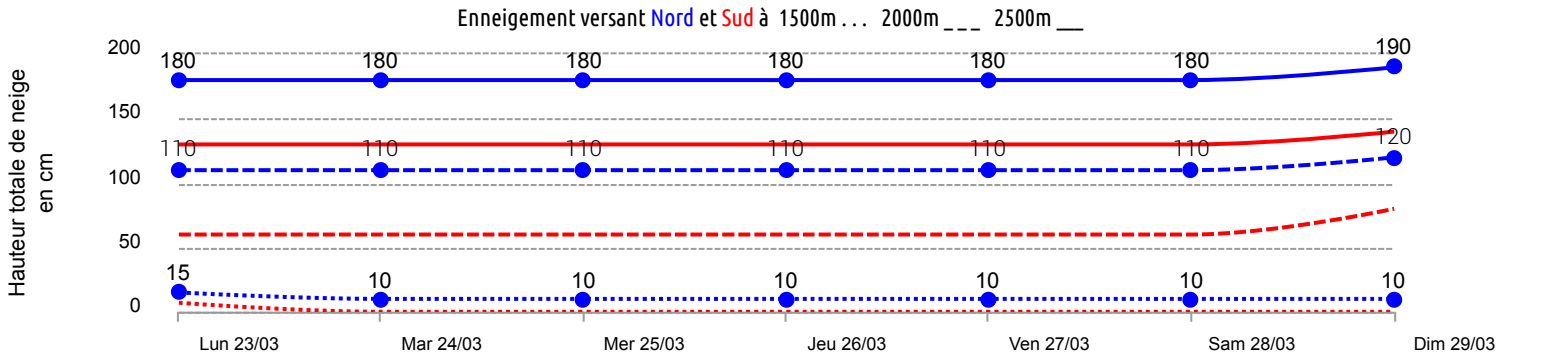

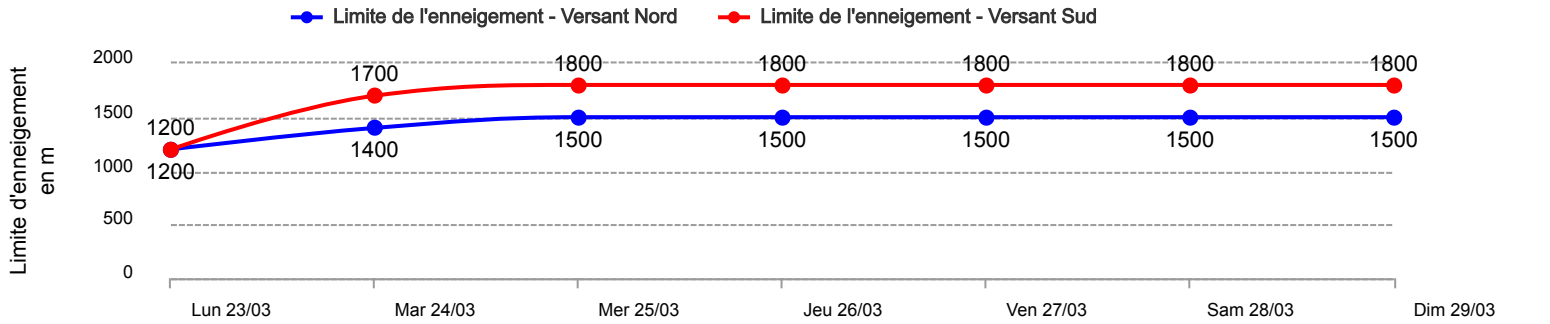

Pour consulter la vigilance en cours, veuillez vous rendre sur le site https://vigilance.meteofrance.fr/fr

Météo-France - 73 avenue de Paris, 94165 Saint-Mandé cedex - Contact : contact@meteo.fr

Rédigé par Météo-France avec la contribution des observateurs du réseau nivo-météorologiques. Partenariat : ANMSM (Maires de Stations de Montagne), DSF (Domaines Skiables de France), ADSP (Directeurs de Pistes et de la Sécurité des Stations de Sports d'Hiver) et autres acteurs de la montagne.

Bulletin neige & avalanches par téléphone au
0 892 68 10 20 Service 0,35 € / min + prix appel