Bulletin d'estimation du risque d'avalanche
(valable en dehors des pistes balisées et ouvertes)

MASSIF : Ubaye

Rédigé le dimanche 29 mars 2026 à 15h

Estimation des risques pour le : LUNDI 30 MARS

INSTABILITÉS EN ALTITUDE, DANS LA NEIGE VENTÉE

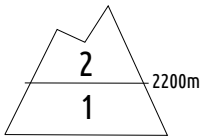

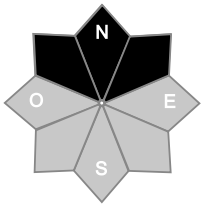

Au-dessus de 2200m indice de risque limité, plus bas indice faible.

Départs spontanés : rares et à haute altitude, en neige ventée

Déclenchements provoqués : instabilités de surface dans la neige ventée, ponctuellement volumineuses

Indices de risque : 5 très fort - 4 fort - 3 marqué - 2 limité - 1 faible -- En noir : les pentes les plus dangereuses

Stabilité du manteau neigeux

Situation avalancheuse typique : neige ventée

Déclenchements provoqués : instabilités limitées à quelques pentes d'altitude. Possibles surtout en large orientation nord au-dessus de 2200 m environ, parfois à distance des crêtes, ces instabilités sont plutôt bien identifiables dans la neige ventée. Un seul skieur peut parfois les déclencher, générant une avalanche de taille petite à moyenne. Le vent souffle de plus en plus fort au fil des heures, mobilisant la faible quantité de neige récente tombée la nuit de samedi à dimanche.

Départs spontanés : rares et restant peu volumineux dans les secteurs d'accumulation par le vent en altitude. Taille petite, plus rarement moyenne.

Qualité de la neige

Enneigement proche des normales.
Hauteurs de neige observées : 76 cm à la Nivôse de Restefond à 2550 m, secteur relativement peu enneigé cet hiver.

Enneigement skiable : vers 1500 m en ubacs, 1900/2000 m en adrets peu pentus.

État de la neige en surface : quelques cm de neige récente en altitude, tombés la nuit de samedi à dimanche sur un manteau neigeux printanier en adrets, durcis par le vent en ubacs d'altitude. En journée de lundi, humidification restant superficielle avec le redoux temporaire et les éclaircies.

Aperçu météo pour le lundi 30 mars

nuit	matin	après-midi	soir

Ensoleillé et doux, vent fort à haute altitude, surtout en fin de journée

Pluie-Neige				
Iso 0 °C	2 000 m	2 500 m	2 300 m	2 100 m
Vent 2000 m	↙ 10 km/h	↓ 25 km/h	↘ 45 km/h	↓ 80 km/h
Vent 3000 m	↓ 30 km/h	↘ 50 km/h	↘ 60 km/h	↓ 120 km/h

Épaisseur de neige hors-piste

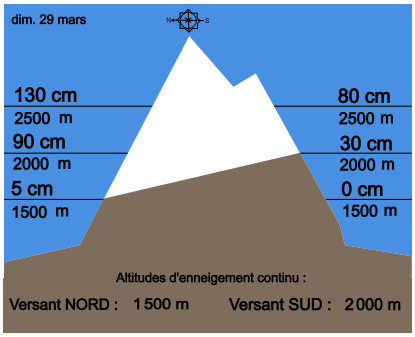

Précipitations à 1800 m

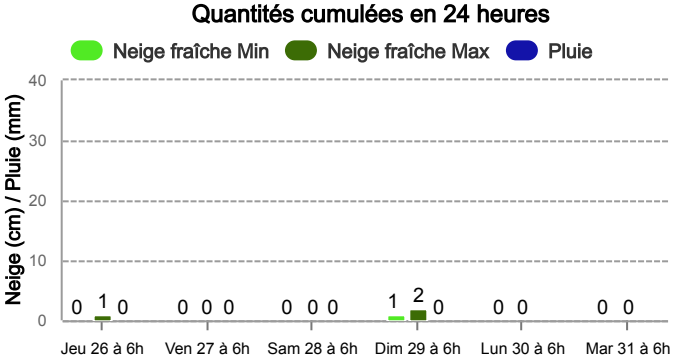

Tendance du mardi 31 mars

Indice de risque limité

Peu d'évolution de la situation nivologique. Quelques instabilités persistent en altitude dans la neige ventée. Risque limité.

Pour consulter la vigilance en cours, veuillez vous rendre sur le site https://vigilance.meteofrance.fr/fr

Météo-France - 73 avenue de Paris, 94165 Saint-Mandé cedex - Contact : contact@meteo.fr

Rédigé par Météo-France avec la contribution des observateurs du réseau nivo-météorologiques. Partenariat : ANMSM (Maires de Stations de Montagne), DSF (Domaines Skiables de France), ADSP (Directeurs de Pistes et de la Sécurité des Stations de Sports d'Hiver) et autres acteurs de la montagne.

Bulletin neige & avalanches par téléphone au
0 892 68 10 20 Service 0,35 € / min + prix appel

RÉPUBLIQUE FRANÇAISE
Liberté Égalité Fraternité

METEO FRANCE
À VOS CÔTÉS, DANS UN CLIMAT QUI CHANGE

Bulletin d'estimation du risque d'avalanche

(valable en dehors des pistes balisées et ouvertes)

MASSIF : Ubaye

Rédigé le dimanche 29 mars 2026 à 15h

Conditions nivo-météo des 7 derniers jours

	lun. 23/03				mar. 24/03				mer. 25/03				jeu. 26/03				ven. 27/03				sam. 28/03				dim. 29/03			
	03h	09h	15h	21h	03h	09h	15h	21h	03h	09h	15h	21h	03h	09h	15h	21h	03h	09h	15h	21h	03h	09h	15h	21h	03h	09h	15h	21h
Météo																												
Vent (km/h)	35	25	20	15	15	10	15	20	25	40	70	100	100	80	70	60	60	50	40	30	25	25	25	25	30	40	30	15
à 3000m																												
Vent (km/h)	25	15	15	10	5	5	5	5	10	20	50	80	80	60	50	50	45	35	20	10	10	10	20	15	20	40	25	15
à 2000m																												

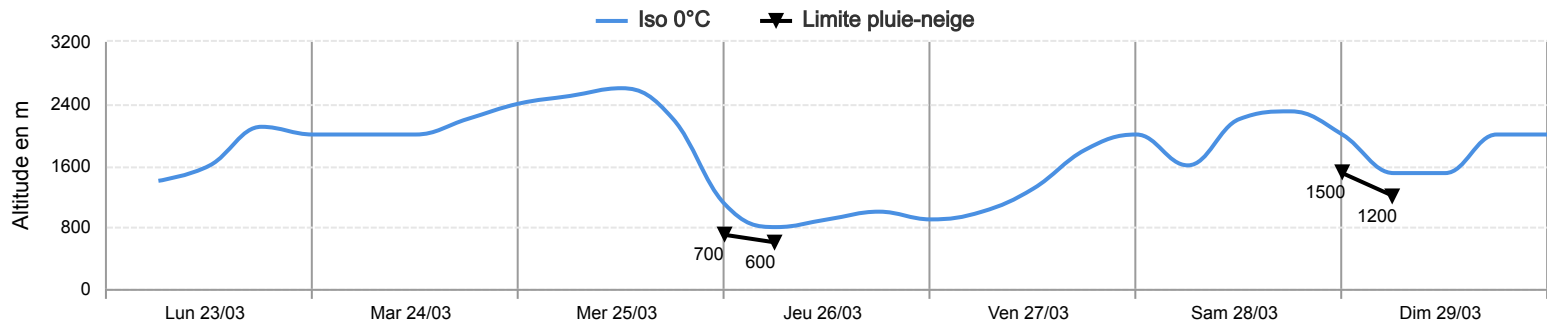

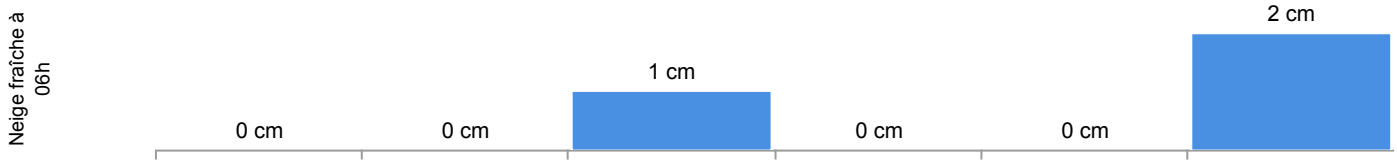

Risque d'avalanche	lun. 23/03	mar. 24/03	mer. 25/03	jeu. 26/03	ven. 27/03	sam. 28/03	dim. 29/03
	3	2	2	3	2	2	2

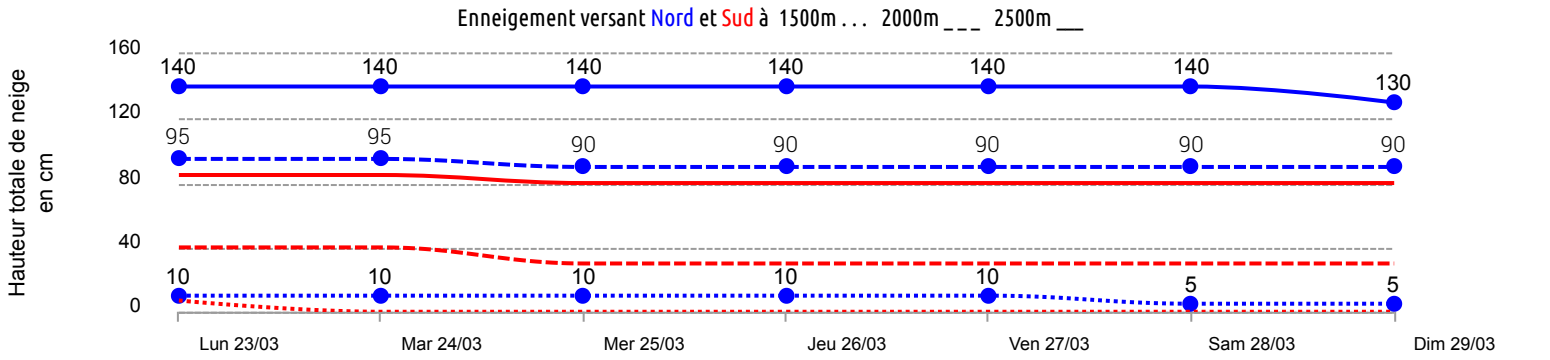

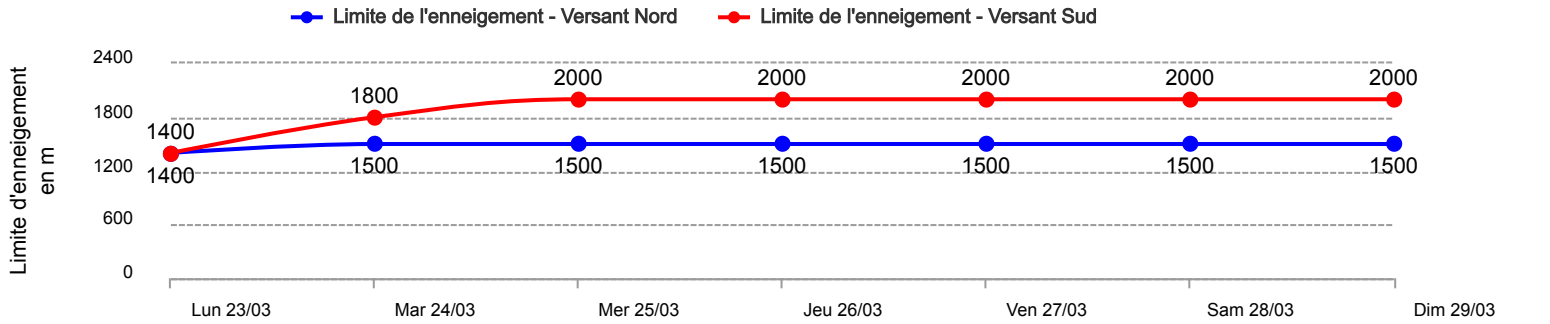

Pour consulter la vigilance en cours, veuillez vous rendre sur le site https://vigilance.meteofrance.fr/fr

Météo-France - 73 avenue de Paris, 94165 Saint-Mandé cedex - Contact : contact@meteo.fr

Rédigé par Météo-France avec la contribution des observateurs du réseau nivo-météorologiques. Partenariat : ANMSM (Maires de Stations de Montagne), DSF (Domaines Skiables de France), ADSP (Directeurs de Pistes et de la Sécurité des Stations de Sports d'Hiver) et autres acteurs de la montagne.

Bulletin neige & avalanches par téléphone au
0 892 68 10 20 Service 0,35 € / min + prix appel