Bulletin d'estimation du risque d'avalanche

(valable en dehors des pistes balisées et ouvertes)

MASSIF : Capcir Puymorens

Rédigé le dimanche 29 mars 2026 à 16h

Estimation des risques pour le : LUNDI 30 MARS

INSTABILITÉS DANS LES CHUTES DE NEIGE VENTÉE RÉCENTES ET STRUCTURES DE PLAQUES PARFOIS PLUS ÉPAISSES EN ALTITUDE

3

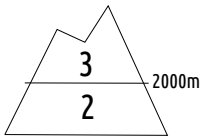

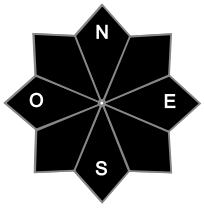

Au-dessus de 2000m indice de risque marqué, plus bas indice limité.

Départs spontanés : Départs ponctuels dans la neige récente dans les pentes raides soit par humidification dans les pentes raides ensoleillées soit par surcharge due au transport de neige par le vent

Déclenchements provoqués : Avalanches de plaques formées dans les chutes de neige ventée récentes

Indices de risque : 5 très fort - 4 fort - 3 marqué - 2 limité - 1 faible -- En noir : les pentes les plus dangereuses

Stabilité du manteau neigeux

Situation avalancheuse typique : neige ventée couche fragile persistante

Déclenchements provoqués :

Avalanches de plaques déclenchables au passage d'un skieur : de nouvelles structures de plaques, parfois loin des crêtes, sont en formation dans les chutes de neige ventée de samedi et dimanche. Les secteurs proches de l'Ariège sont les plus concernés (Nord du Capcir, vallée du Galbe). Les accumulations sont plutôt à attendre dans les versants d'un large Sud, mais pas seulement. De plus, au-dessus de 2000/2200m, des couches fragiles (grains anguleux, givre de surface voire neige roulée) sont encore présentes, pouvant donner des avalanches de taille plus importantes (taille 2 à rare 3). Ces plaques seront plutôt dures en altitude et à proximités des crêtes et ruptures de pentes, parfois plus friables et plus difficilement identifiables à plus basse altitude et dans les endroits abrités du vent.

Observables : neige travaillée par le vent en surface, fissures devant les skis, "woomfs", quantité de neige fraiche et accumulations.

Départs spontanés :

Avalanches de taille petite à moyenne possibles en neige humide le matin dans les pentes raides des secteurs Est prenant le soleil, puis en journée par humidification dans les nuages sous 2000m. Sinon, plus en altitude, des départs spontanés en neige sèche sont aussi possibles dans les pentes raides, par surcharge par transport de neige par le vent.

Qualité de la neige

Enneigement :

L'enneigement est excellent et parmi les meilleurs de ces 20 dernières années. En altitude, les cumuls sont très conséquents, mais les crêtes et sommets exposés au vent d'ouest à nord-ouest sont parfois complètement déneigés. Les nouvelles chutes de neige redonne un aspect blanc dès 1400/1500 m sans changer vraiment l'altitude de skiabilité qui est plutôt vers 1600/1700 m avec une sous-couche permettant de skier plus sereinement.

Qualité de la neige :

Lundi matin, la montagne garde un bel aspect hivernal avec la présence de neige dès les premières hauteurs, puis quelques cm de neige fraiche souvent sous forme de neige roulée dès 1400/1500m. Dès 1800 m, l'enneigement sera assez hétérogène sous l'action du vent soufflant depuis samedi, avec 10/20 cm de neige fraiche, voire localement plus proche de l'Ariège, mais des crêtes et sommets souvent pelés ou en neige dure. En journée, avec la remontée des températures, la neige va s'humidifier en surface jusqu'à 1800/2000m mais on devraient tout de même trouver quelques combes abritées en neige légère et poudreuse.

Aperçu météo pour le lundi 30 mars

	nuit	matin	après-midi	soir

Accalmie lundi matin avant le retour de nuages et de précipitations par le nord l'après-midi. Vent de nord à nord-ouest qui souffle toujours fort.

Pluie-Neige			1 800 m	1 700 m
Iso 0 °C	1 200 m	2 000 m	2 200 m	2 100 m
Vent 2000 m	↓ 70 km/h	↓ 70 km/h	↘ 80 km/h	↓ 85 km/h
Vent 3000 m	↘ 80 km/h	↓ 80 km/h	↘ 95 km/h	↘ 100 km/h

Épaisseur de neige hors-piste

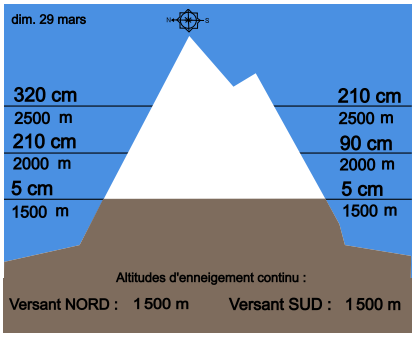

Précipitations à 1800 m

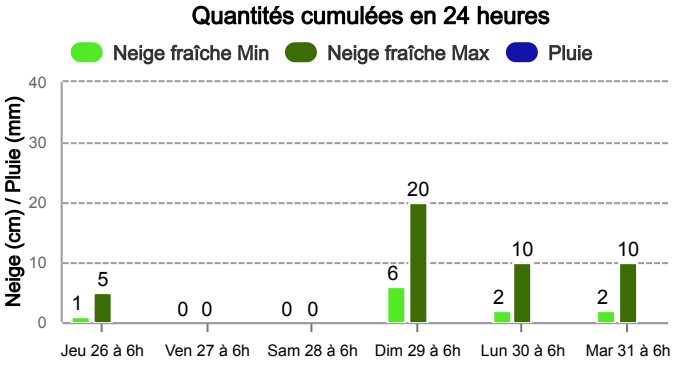

Tendance du mardi 31 mars

3 **Indice de risque marqué**

Stationnaire avec encore du vent et du transport de neige prévu pour mardi.

Pour consulter la vigilance en cours, veuillez vous rendre sur le site https://vigilance.meteofrance.fr/fr

Météo-France - 73 avenue de Paris, 94165 Saint-Mandé cedex - Contact : contact@meteo.fr

Rédigé par Météo-France avec la contribution des observateurs du réseau nivo-météorologiques. Partenariat : ANMSM (Maires de Stations de Montagne), DSF (Domaines Skiables de France), ADSP (Directeurs de Pistes et de la Sécurité des Stations de Sports d'Hiver) et autres acteurs de la montagne.

Bulletin neige & avalanches par téléphone au 0 892 68 10 20 Service 0,35 € / min + prix appel

RÉPUBLIQUE FRANÇAISE
Liberté Égalité Fraternité

METEO FRANCE
À VOS CÔTÉS, DANS UN CLIMAT QUI CHANGE

Bulletin d'estimation du risque d'avalanche

(valable en dehors des pistes balisées et ouvertes)

MASSIF : Capcir Puymorens

Rédigé le dimanche 29 mars 2026 à 16h

Conditions nivo-météo des 7 derniers jours

	lun. 23/03				mar. 24/03				mer. 25/03				jeu. 26/03				ven. 27/03				sam. 28/03				dim. 29/03			
	03h	09h	15h	21h	03h	09h	15h	21h	03h	09h	15h	21h	03h	09h	15h	21h	03h	09h	15h	21h	03h	09h	15h	21h	03h	09h	15h	21h
Météo																												
Vent (km/h)	50	40	35	25	20	20	20	20	30	55	75	90	90	100	95	105	95	95	85	70	60	70	85	105	115	110	95	85
à 3000m																												
Vent (km/h)	35	35	30	20	15	10	10	10	15	35	50	70	75	80	80	85	75	75	65	60	45	60	60	80	90	90	80	65
à 2000m																												

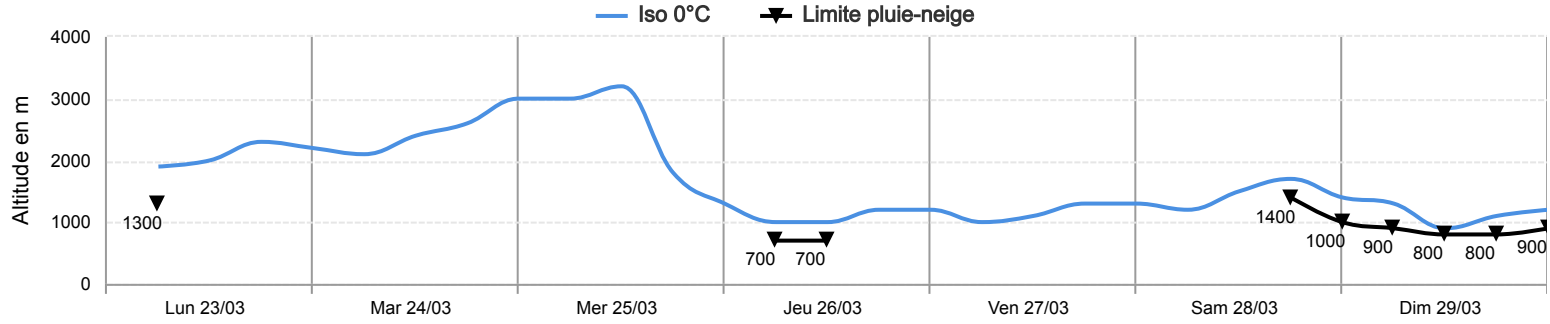

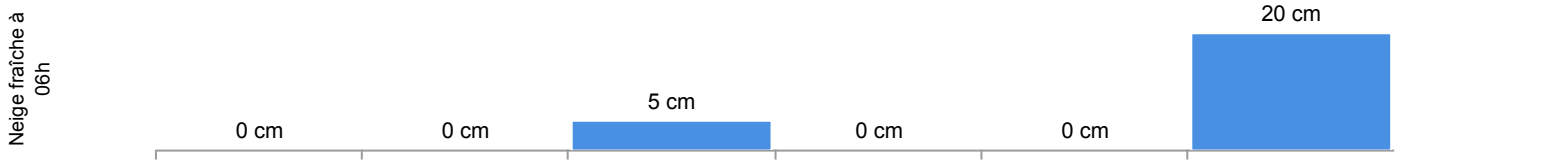

Risque d'avalanche	lun. 23/03	mar. 24/03	mer. 25/03	jeu. 26/03	ven. 27/03	sam. 28/03	dim. 29/03
	3	3	2	2	2	2	3

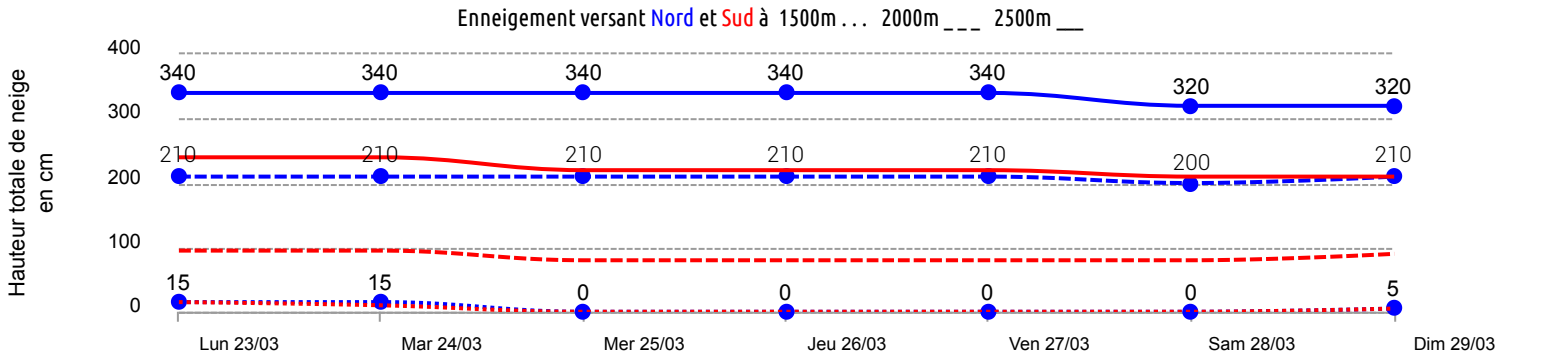

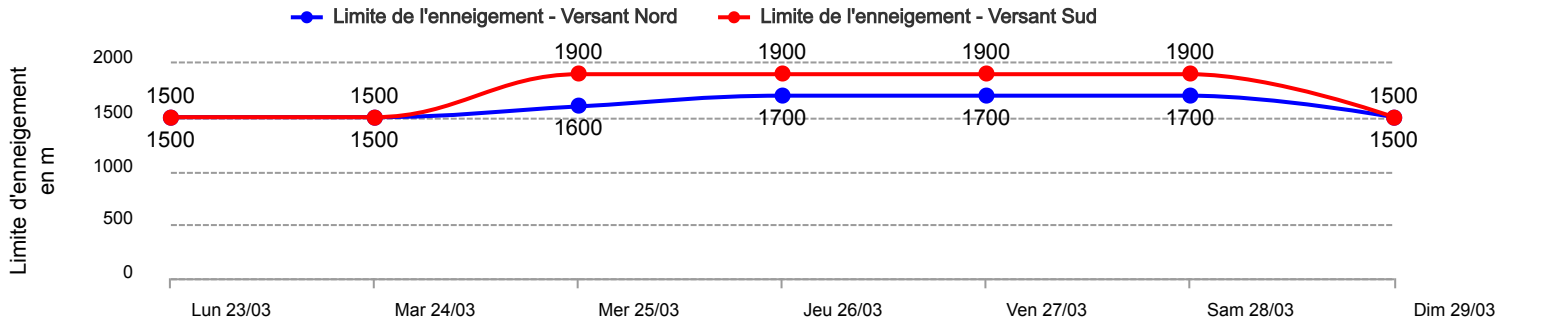

Pour consulter la vigilance en cours, veuillez vous rendre sur le site https://vigilance.meteofrance.fr/fr

Météo-France - 73 avenue de Paris, 94165 Saint-Mandé cedex - Contact : contact@meteo.fr

Bulletin neige & avalanches par téléphone au

0 892 68 10 20 Service 0,35 € / min + prix appel

Rédigé par Météo-France avec la contribution des observateurs du réseau nivo-météorologiques. Partenariat : ANMSM (Maires de Stations de Montagne), DSF (Domaines Skiables de France), ADSP (Directeurs de Pistes et de la Sécurité des Stations de Sports d'Hiver) et autres acteurs de la montagne.