Bulletin d'estimation du risque d'avalanche

(valable en dehors des pistes balisées et ouvertes)

MASSIF : Cerdagne Canigou

Rédigé le dimanche 29 mars 2026 à 16h

Estimation des risques pour le : LUNDI 30 MARS

STRUCTURES DE PLAQUES FORMÉES PAR LE TRANSPORT DE NEIGE PAR LE VENT

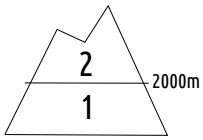

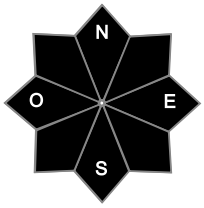

Au-dessus de 2000m indice de risque limité, plus bas indice faible.

Départs spontanés : Départs ponctuels en neige récente dans des couloirs raides

Déclenchements provoqués : Anciennes plaques en versants nord; nouvelles plaques à vent avec le transport de neige en cours depuis samedi

Indices de risque : 5 très fort - 4 fort - 3 marqué - 2 limité - 1 faible -- En noir : les pentes les plus dangereuses

Stabilité du manteau neigeux

Situation avalancheuse typique : neige ventée couche fragile persistante

Déclenchements provoqués :

De structures de plaques, plutôt dures proches des crêtes, parfois encore d'aspect friable loin des crêtes et dans des combes plus abritées, sont en place ou encore en formation sous l'action du vent qui souffle depuis plusieurs jours. Leurs déclenchements devraient se limiter à des avalanches de petites tailles toutefois suffisantes pour déséquilibrer ou faire chuter un pratiquant.

De plus, de rares avalanches de plaques plus épaisses (taille moyenne) sont possibles plutôt au-dessus de 2000/2200 m dans un large secteur nord. En effet, des couches fragiles persistantes sont présentes même si elles deviennent de plus en plus difficilement sollicitables par un skieur. Elles sont souvent difficiles à détecter, car masquées par les chutes de neige récente et le transport de neige par le vent.

Observables : neige en surface travaillée par le vent, fissures devant les skis ou "woomfs" éventuels.

Départs spontanés :

Des départs ponctuels spontanés de petite taille (taille 1) sont possibles soit par humidification dans les pentes raides prenant le soleil dès le matin puis en cours de journée, soit dans la neige sèche par surcharge par le vent dans les couloirs raides.

Qualité de la neige

Enneigement :

L'enneigement est excellent et parmi les meilleurs de ces 20 dernières années. En altitude, les cumuls sont encore conséquents, mais les crêtes et sommets exposés au vent d'ouest à nord-ouest sont souvent complètement déneigés. Avec les nouvelles chutes de neige datant samedi et dimanche matin, on retrouve un peu de neige au mieux vers 1400/1500 m mais on peut seulement chausser vers 1600/1700 m en Nord pour trouver une réelle sous-couche permettant de progresser à ski.

Qualité de la neige :

Lundi matin, la montagne a encore un bel aspect hivernal avec un saupoudrage visible autour de 1500 m et quelques cm de neige fraiche dès 1700/1800m. Plus haut, les cumuls de neige sont très hétérogènes sous l'action du vent, avec des zones d'accumulations. Les crêtes et sommets sont souvent bien pelés ou dégarnis avec de la neige dure et compacte voire glacée. En journée, on s'attend à une humidification de surface dans les versants ensoleillés au fur et à mesure de la journée jusqu'à 1900/2100 m. Ailleurs, on trouvera une neige dure et tassée par le vent sauf dans quelques combes abritées certainement encore poudreuses.

Aperçu météo pour le lundi 30 mars

nuit	matin	après-midi	soir

Temps plutôt bien lumineux même si les nuages se font plus présents l'après-midi. Ambiance encore froide avec le vent de nord-ouest soutenu.

Pluie-Neige				
Iso 0 °C	1 600 m	2 100 m	2 400 m	2 500 m
Vent 2000 m	↘ 60 km/h	↘ 60 km/h	↘ 70 km/h	↘ 75 km/h
Vent 3000 m	↓ 90 km/h	↓ 85 km/h	↘ 90 km/h	↓ 100 km/h

Épaisseur de neige hors-piste

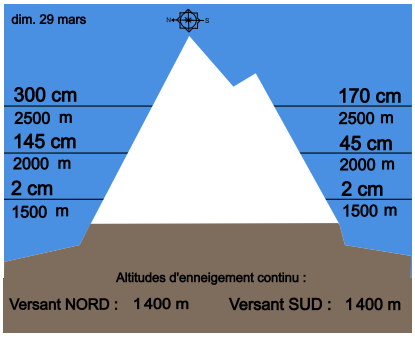

Précipitations à 1800 m

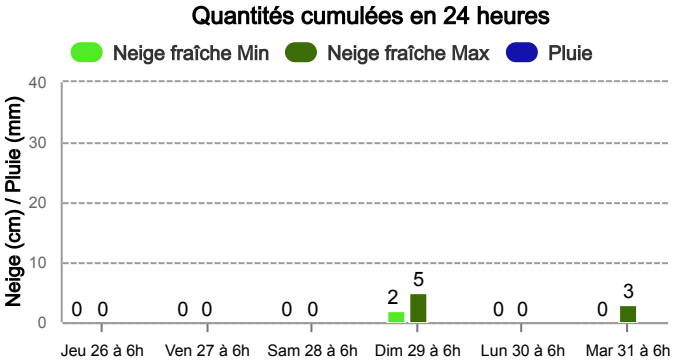

Tendance du mardi 31 mars

Indice de risque limité

Stationnaire sans apport de neige supplémentaire mais avec toujours un vent soutenu et du transport de neige par le vent.

Pour consulter la vigilance en cours, veuillez vous rendre sur le site https://vigilance.meteofrance.fr/fr

Météo-France - 73 avenue de Paris, 94165 Saint-Mandé cedex - Contact : contact@meteo.fr

Rédigé par Météo-France avec la contribution des observateurs du réseau nivo-météorologiques. Partenariat : ANMSM (Maires de Stations de Montagne), DSF (Domaines Skiables de France), ADSP (Directeurs de Pistes et de la Sécurité des Stations de Sports d'Hiver) et autres acteurs de la montagne.

Bulletin neige & avalanches par téléphone au

0 892 68 10 20 Service 0,35 € / min + prix appel

RÉPUBLIQUE FRANÇAISE
Liberté Égalité Fraternité

METEO FRANCE
À VOS CÔTÉS, DANS UN CLIMAT QUI CHANGE

Bulletin d'estimation du risque d'avalanche

(valable en dehors des pistes balisées et ouvertes)

MASSIF : Cerdagne Canigou

Rédigé le dimanche 29 mars 2026 à 16h

Conditions nivo-météo des 7 derniers jours

	lun. 23/03				mar. 24/03				mer. 25/03				jeu. 26/03				ven. 27/03				sam. 28/03				dim. 29/03			
	03h	09h	15h	21h	03h	09h	15h	21h	03h	09h	15h	21h	03h	09h	15h	21h	03h	09h	15h	21h	03h	09h	15h	21h	03h	09h	15h	21h
Météo																												
Vent (km/h)	50	50	40	30	25	20	20	20	25	35	40	70	90	100	95	105	95	95	85	70	75	70	80	105	120	110	90	90
à 3000m																												
Vent (km/h)	35	35	30	20	15	10	10	10	15	20	30	45	75	80	80	85	75	75	65	55	60	50	60	80	95	85	65	70
à 2000m																												

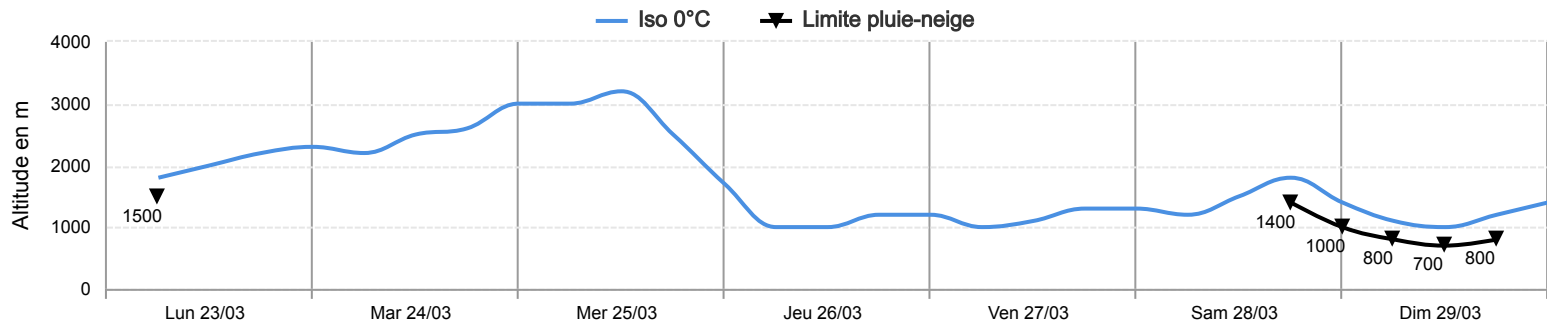

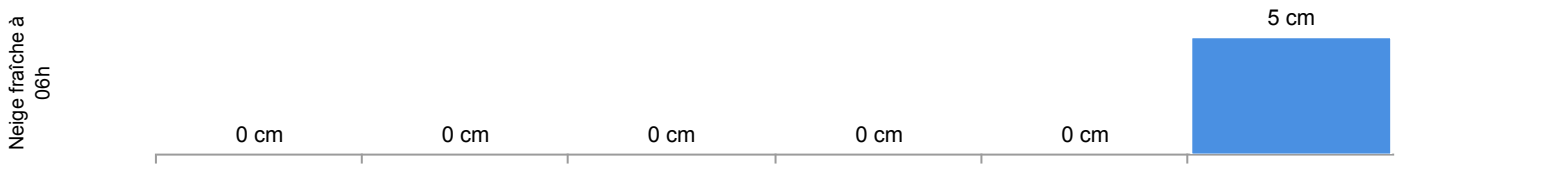

Risque d'avalanche	lun. 23/03	mar. 24/03	mer. 25/03	jeu. 26/03	ven. 27/03	sam. 28/03	dim. 29/03
	2	2	2	2	2	2	2

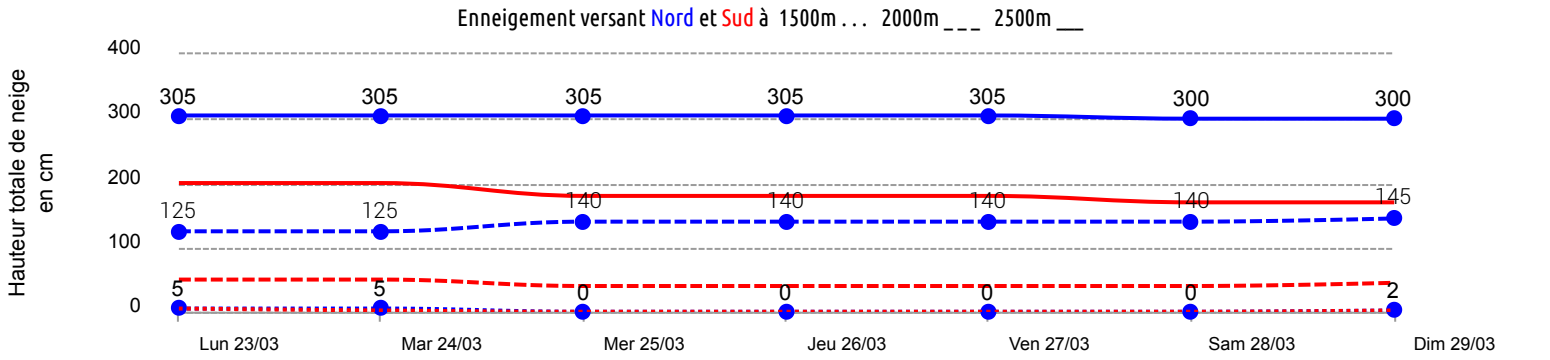

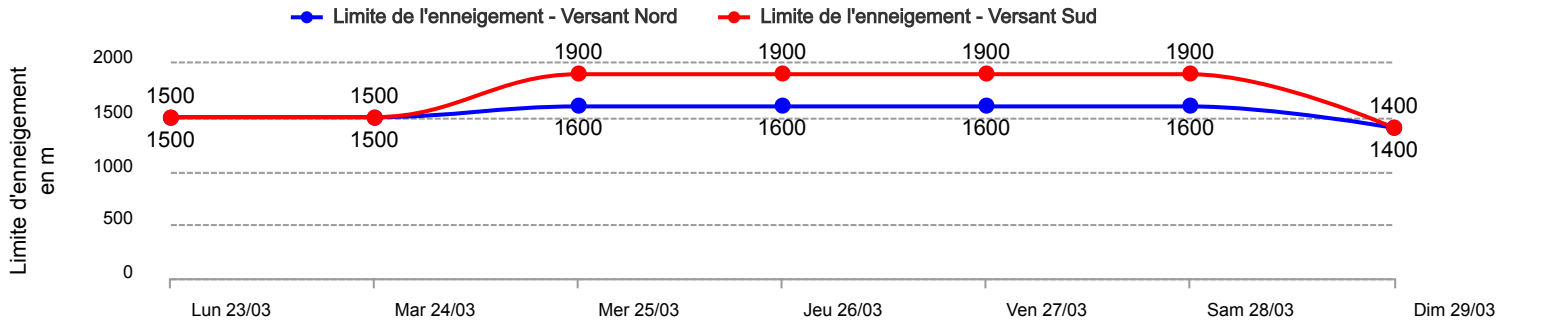

Pour consulter la vigilance en cours, veuillez vous rendre sur le site https://vigilance.meteofrance.fr/fr

Météo-France - 73 avenue de Paris, 94165 Saint-Mandé cedex - Contact : contact@meteo.fr

Bulletin neige & avalanches par téléphone au

0 892 68 10 20 Service 0,35 € / min + prix appel

Rédigé par Météo-France avec la contribution des observateurs du réseau nivo-météorologiques. Partenariat : ANMSM (Maires de Stations de Montagne), DSF (Domaines Skiables de France), ADSP (Directeurs de Pistes et de la Sécurité des Stations de Sports d'Hiver) et autres acteurs de la montagne.