Bulletin d'estimation du risque d'avalanche

(valable en dehors des pistes balisées et ouvertes)

MASSIF : Chartreuse

Rédigé le dimanche 29 mars 2026 à 16h

Estimation des risques pour le : LUNDI 30 MARS

QUELQUES NOUVELLES INSTABILITÉS DANS LA NEIGE VENTÉE, LOCALEMENT RÉACTIVES.

2

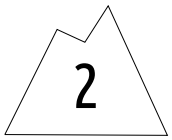

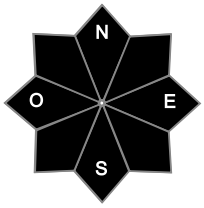

zones d'accumulation

Indices de risque : 5 très fort - 4 fort - 3 marqué - 2 limité - 1 faible -- En noir : les pentes les plus dangereuses

Indice de risque limité.

Départs spontanés : Rare rupture de plaque sous le vent de Nord. Rares coulées humides au soleil en cas d'éclaircies (surtout le matin).

Déclenchements provoqués : Quelques nouvelles plaques dans la neige ventée, parfois loin des crêtes.

Stabilité du manteau neigeux

Situation avalancheuse typique : neige ventée

Déclenchements provoqués : Quelques nouvelles plaques à vent se forment ce lundi, avec le renforcement du vent de Nord qui peut à nouveau transporter de la neige récente. Plus le vent est fort, plus elles ont tendance à être situées loin des crêtes et en bas de pente. Elles peuvent se retrouver en tout versant. Le plus souvent, elles sont difficiles à déclencher et d'aspect dur, mais localement il n'est pas exclu que de rares plaques présentent un aspect un peu plus friable, tout en étant plus réactives au passage d'un pratiquant. La petite couche de neige fraîche attendue en fin de journée et soirée de lundi (2 à 8 cm) tombe très ventée et ne vient pas fondamentalement changer la donne.
Observables : zones d'accumulations, congères, signes du travail par le vent...

Départs spontanés : - Lundi en cours de journée et soirée, une rare rupture de corniche et/ou de plaque, engendrant une avalanche de taille 1 à 2, est possible dans les pentes chargées par le vent de Nord, qui se renforce à nouveau nettement en altitude.
- Surtout lundi matin, rares coulées humides de taille 1 dans les pentes ensoleillées en cas d'éclaircies, dans la neige récente qui peut s'humidifier au soleil et près des rochers.

Autres : Les surfaces décapées par le vent près des crêtes sont parfois en glace, et peuvent être très glissantes.

Qualité de la neige

Qualification de l'enneigement : LL'enneigement est bon à basse altitude, et même très bon en haut du massif, mais avec des répartitions assez hétérogènes à cause du vent. Peu de sous couche sous 1700m en plein Sud.
Limites skiables : Vers 1000 / 1200m selon le versant, avec prudence en Sud / sous les sapins

Qualité de la neige lundi : Neige récente souvent travaillée ou soufflée par le vent dans de nombreux endroits. Le manteau neigeux est parfois très irrégulier. Présence de congères et de corniches. Certaines crêtes et pentes les plus ventées, où la neige a été arrachée, peuvent être dégarnies et le ski se fait parfois sur la vieille croûte de regel. Toutefois, on retrouve des secteurs en neige poudreuse plus agréable, surtout loin des crêtes /en bas de pentes / dans les arbres. A noter que dans certaines pentes ayant été exposées au soleil, la neige récente s'est parfois humidifiée, on peut alors y retrouver des surfaces croûtées glissantes. L'après-midi et le soir, une petite couche de neige fraîche peut se déposer, mais elle est souvent ventée.

Aperçu météo pour le lundi 30 mars

	nuit	matin	après-midi	soir

Renforcement progressif du vent de Nord. Eclaircies possibles jusqu'à lundi matin, puis plus nuageux avec un peu de neige l'après-midi et le soir.

Pluie-Neige			1 100 m	900 m
Iso 0 °C	1 200 m	1 200 m	1 400 m	1 300 m
Vent 1500 m	↓ 30 km/h	↓ 30 km/h	↓ 50 km/h	↓ 50 km/h
Vent 2000 m	↓ 45 km/h	↘ 40 km/h	↘ 60 km/h	↓ 65 km/h

Épaisseur de neige hors-piste

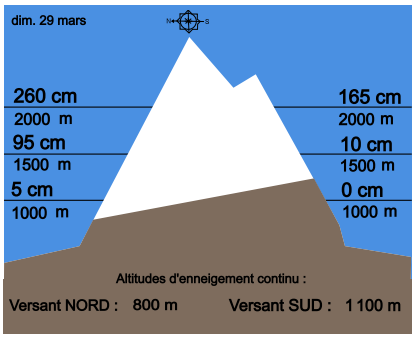

Précipitations à 1800 m

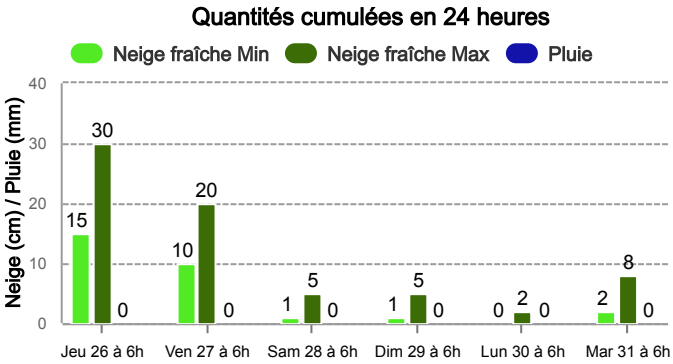

Tendance du mardi 31 mars

2 **Indice de risque limité**

Mardi, le risque devrait peu évoluer. La bise de Nord souffle fort en altitude, notamment vers les crêtes Temps plus ou moins nuageux avec quelques éclaircies par moments. Atmosphère toujours fraîche avec un isotherme 0°C vers 900 m le matin, 1300 m l'après-midi.

Pour consulter la vigilance en cours, veuillez vous rendre sur le site https://vigilance.meteofrance.fr/fr

Météo-France - 73 avenue de Paris, 94165 Saint-Mandé cedex - Contact : contact@meteo.fr

Rédigé par Météo-France avec la contribution des observateurs du réseau nivo-météorologiques. Partenariat : ANMSM (Maires de Stations de Montagne), DSF (Domaines Skiables de France), ADSP (Directeurs de Pistes et de la Sécurité des Stations de Sports d'Hiver) et autres acteurs de la montagne.

Bulletin neige & avalanches par téléphone au
0 892 68 10 20 Service 0,35 € / min + prix appel

RÉPUBLIQUE FRANÇAISE
Liberté Égalité Fraternité

METEO FRANCE
À VOS CÔTÉS, DANS UN CLIMAT QUI CHANGE

Bulletin d'estimation du risque d'avalanche

(valable en dehors des pistes balisées et ouvertes)

MASSIF : Chartreuse

Rédigé le dimanche 29 mars 2026 à 16h

Conditions nivo-météo des 7 derniers jours

	lun. 23/03				mar. 24/03				mer. 25/03				jeu. 26/03				ven. 27/03				sam. 28/03				dim. 29/03			
	03h	09h	15h	21h	03h	09h	15h	21h	03h	09h	15h	21h	03h	09h	15h	21h	03h	09h	15h	21h	03h	09h	15h	21h	03h	09h	15h	21h
Météo																												
Vent (km/h)	15	25	25	15	30	15	5	10	25	50	80	80	90	80	75	70	75	70	45	30	45	55	40	60	60	50	35	40
à 2000m																												
Vent (km/h)	5	10	20	10	15	10	15	10	10	25	55	50	50	45	55	45	40	55	35	20	35	40	25	40	40	35	20	30
à 1500m																												

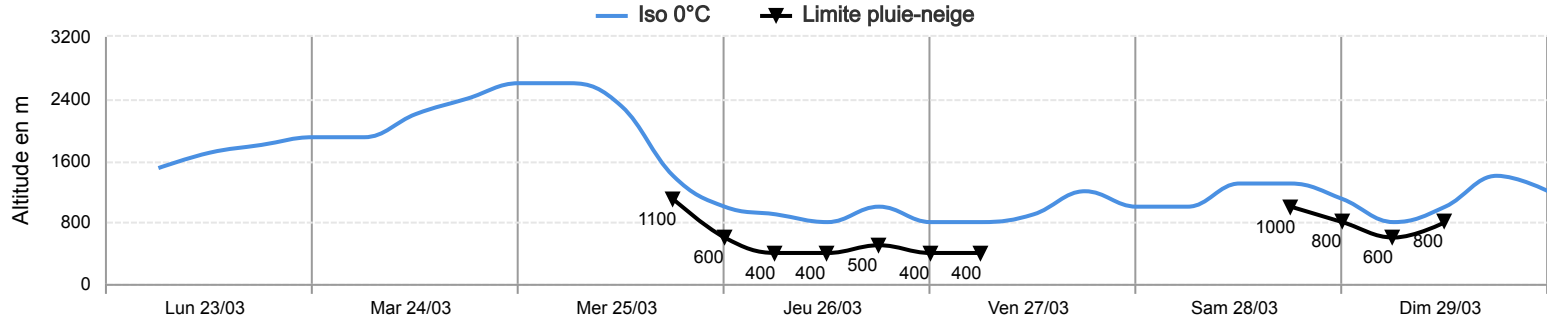

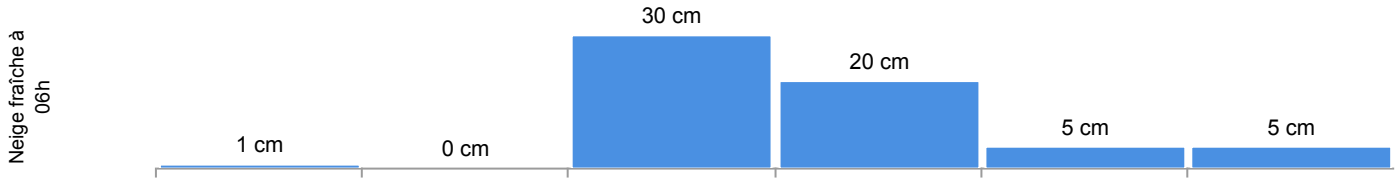

Risque d'avalanche	lun. 23/03	mar. 24/03	mer. 25/03	jeu. 26/03	ven. 27/03	sam. 28/03	dim. 29/03
	2	2	2	4	3	2	2

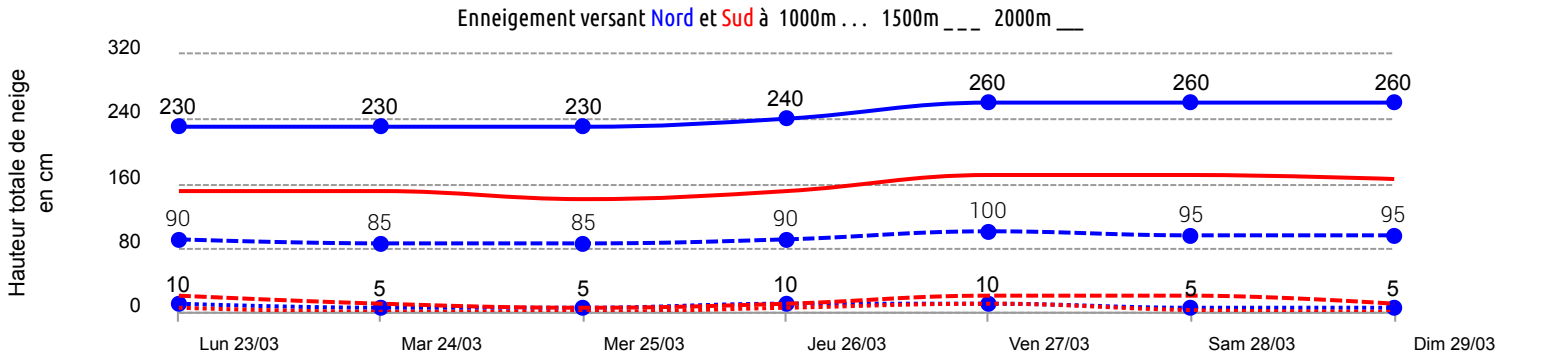

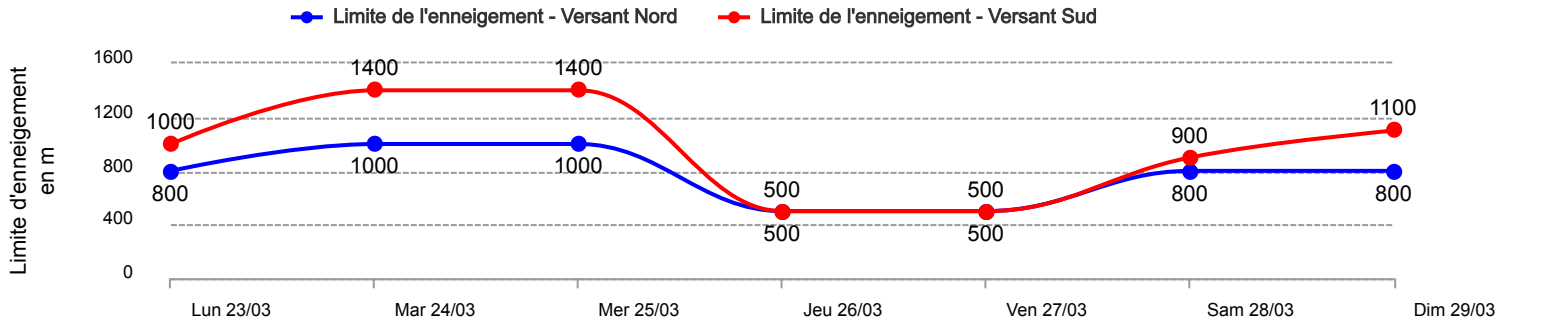

Pour consulter la vigilance en cours, veuillez vous rendre sur le site https://vigilance.meteofrance.fr/fr

Météo-France - 73 avenue de Paris, 94165 Saint-Mandé cedex - Contact : contact@meteo.fr

Rédigé par Météo-France avec la contribution des observateurs du réseau nivo-météorologiques. Partenariat : ANMSM (Maires de Stations de Montagne), DSF (Domaines Skiables de France), ADSP (Directeurs de Pistes et de la Sécurité des Stations de Sports d'Hiver) et autres acteurs de la montagne.

Bulletin neige & avalanches par téléphone au

0 892 68 10 20 Service 0,35 € / min + prix appel