Bulletin d'estimation du risque d'avalanche

(valable en dehors des pistes balisées et ouvertes)

MASSIF : Cinto Rotondo

Rédigé le dimanche 29 mars 2026 à 16h

Estimation des risques pour le : LUNDI 30 MARS

INSTABILITÉS EN ALTITUDE

2

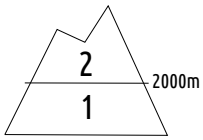

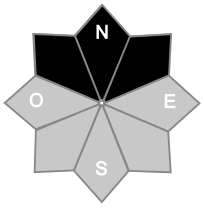

Au-dessus de 2000m indice de risque limité, plus bas indice faible.

Départs spontanés : rares coulées de neige récente humide

Déclenchements provoqués : plaques à vent difficilement sollicitables, encore présentes en altitude au-dessus de 2000 m

Indices de risque : 5 très fort - 4 fort - 3 marqué - 2 limité - 1 faible -- En noir : les pentes les plus dangereuses

Stabilité du manteau neigeux

Situation avalancheuse typique : neige ventée neige humide

Déclenchements provoqués : de fines plaques à vent sont en place dans les pentes raides en toutes orientations, majoritairement au-dessus de 2000 m issues des chutes de neige précédentes. Elles peuvent engendrer des avalanches de taille petite à moyenne (taille 1 à 2) avec des cassures de 10/20 cm voire 30 cm en versants ombragés.
Départs spontanés : peu probable en début de journée (excellent regel nocturne). Des départs spontanés d'avalanches de neige humide sont possibles ensuite dans les pentes ensoleillées raides en suivant la course du soleil (respecter les horaires selon l'orientation). Le plus souvent petites, une avalanche de taille moyenne reste possible. Ces départs sont facilités par la présence de rochers.
Autres : Nombreuses surfaces dures et glacées, pouvant être recouvertes de quelques centimètres de neige récente. Présence de corniches.

Qualité de la neige

Qualification de l'enneigement : L'enneigement est excellent pour la saison au-dessus de 1600 m. Sur la Maniccia, à 2400 m d'altitude dans le massif du Rotondo, on relève pratiquement 3m30 de hauteur de neige totale.
Limite d'enneigement skiable : 1400 à 1500 m selon le versant.
État de la neige : En surface, on trouve dix à vingt cm de neige récente, voire plus par endroits, ils recouvrent un manteau neigeux dure bien regelé. Cette couche de neige récente, ventée surtout en très haute montagne, poursuit son tassement. En surface, elle peut être partiellement croûtée le matin après le regel nocturne puis l'humidification reprend rapidement en versants ensoleillés. En secteurs plus ombragés ou à soleil plus rasant, elle reste lourde et profonde, ou bien partiellement densifiée par le vent. Neige restant croûtée dans les secteurs ombragés raides.

Aperçu météo pour le lundi 30 mars

	nuit	matin	après-midi	soir
Pluie-Neige				
Iso 0 °C	1 800 m	2 000 m	2 100 m	2 300 m
Vent 1500 m	↙ 10 km/h	→ 20 km/h	↗ 30 km/h	→ 35 km/h
Vent 3000 m	← 10 km/h	↘ 20 km/h	↘ 50 km/h	↙ 40 km/h

Épaisseur de neige hors-piste

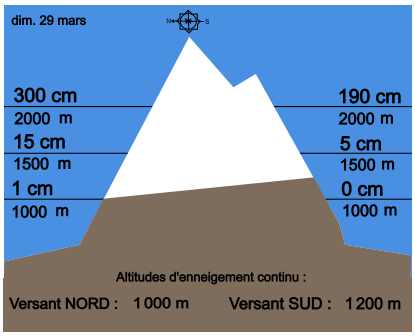

Précipitations à 1800 m

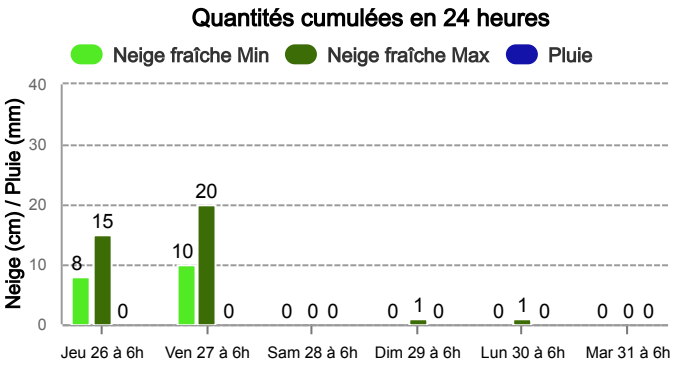

Tendance du mardi 31 mars

2 **Indice de risque limité**

Pas dévolution notable en termes de risque.

Pour consulter la vigilance en cours, veuillez vous rendre sur le site https://vigilance.meteofrance.fr/fr

Météo-France - 73 avenue de Paris, 94165 Saint-Mandé cedex - Contact : contact@meteo.fr

Rédigé par Météo-France avec la contribution des observateurs du réseau nivo-météorologiques. Partenariat : ANMSM (Maires de Stations de Montagne), DSF (Domaines Skiables de France), ADSP (Directeurs de Pistes et de la Sécurité des Stations de Sports d'Hiver) et autres acteurs de la montagne.

Bulletin neige & avalanches par téléphone au 0 892 68 10 20 Service 0,35 € / min + prix appel

RÉPUBLIQUE FRANÇAISE
Liberté Égalité Fraternité

METEO FRANCE
À VOS CÔTÉS, DANS UN CLIMAT QUI CHANGE

Bulletin d'estimation du risque d'avalanche

(valable en dehors des pistes balisées et ouvertes)

MASSIF : Cinto Rotondo

Rédigé le dimanche 29 mars 2026 à 16h

Conditions nivo-météo des 7 derniers jours

	lun. 23/03				mar. 24/03				mer. 25/03				jeu. 26/03				ven. 27/03				sam. 28/03				dim. 29/03			
	03h	09h	15h	21h	03h	09h	15h	21h	03h	09h	15h	21h	03h	09h	15h	21h	03h	09h	15h	21h	03h	09h	15h	21h	03h	09h	15h	21h
Météo																												
Vent (km/h)	10	15	20	40	30	25	20	20	20	60	80	120	110	85	90	90	50	40	35	50	30	15	20	10	15	35	40	30
à 3000m																												
Vent (km/h)	5	10	15	30	5	10	10	10	10	30	50	80	85	60	60	60	35	10	25	30	20	15	20	10	10	35	30	20
à 1500m																												

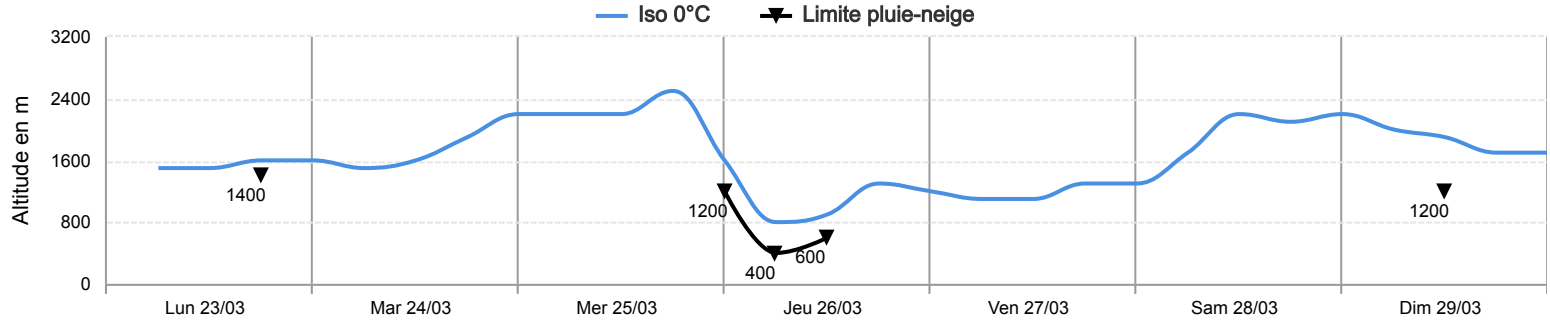

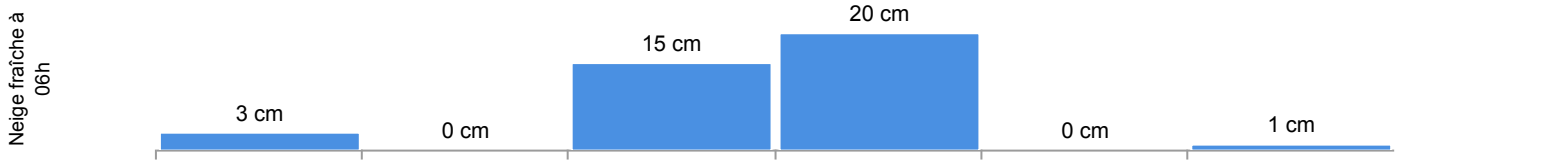

Risque d'avalanche	lun. 23/03	mar. 24/03	mer. 25/03	jeu. 26/03	ven. 27/03	sam. 28/03	dim. 29/03
	2	2	2	2	2	2	2

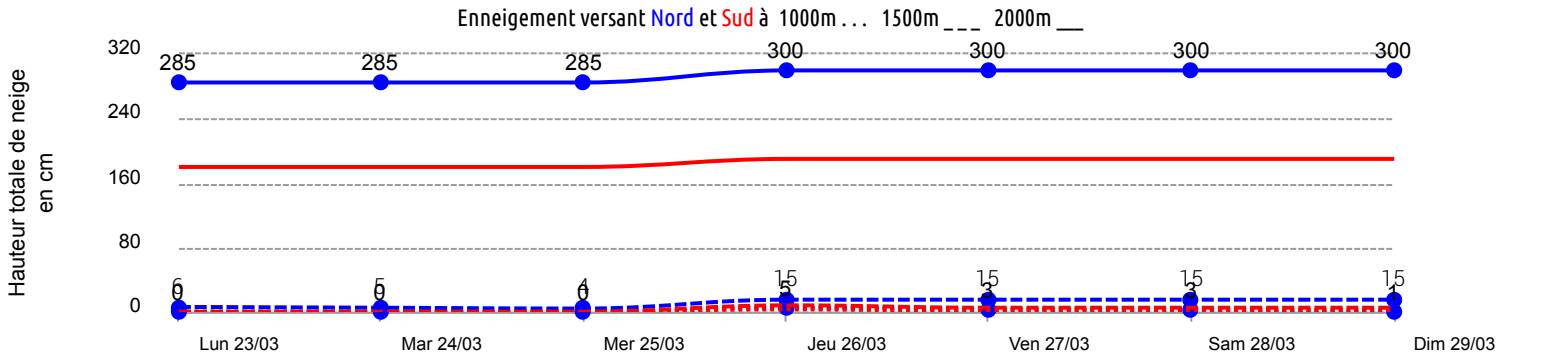

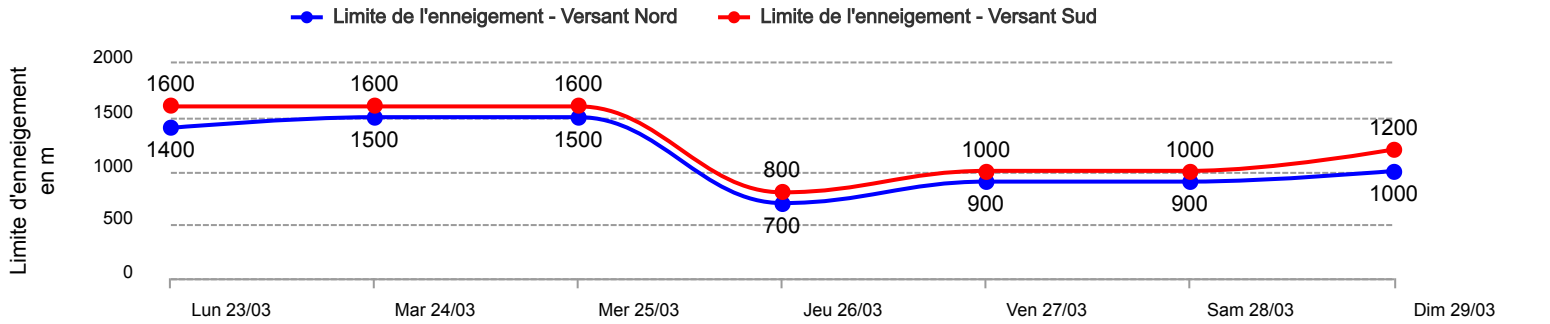

Pour consulter la vigilance en cours, veuillez vous rendre sur le site https://vigilance.meteofrance.fr/fr

Météo-France - 73 avenue de Paris, 94165 Saint-Mandé cedex - Contact : contact@meteo.fr

Rédigé par Météo-France avec la contribution des observateurs du réseau nivo-météorologiques. Partenariat : ANMSM (Maires de Stations de Montagne), DSF (Domaines Skiables de France), ADSP (Directeurs de Pistes et de la Sécurité des Stations de Sports d'Hiver) et autres acteurs de la montagne.

Bulletin neige & avalanches par téléphone au

0 892 68 10 20 Service 0,35 € / min + prix appel