# Bulletin d'estimation du risque d'avalanche

(valable en dehors des pistes balisées et ouvertes)

# MASSIF : Devoluy

Rédigé le dimanche 29 mars 2026 à 16h

## Estimation des risques pour le : LUNDI 30 MARS

**PLAQUES EN PLACE DANS LA NEIGE VENTÉE**

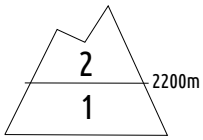


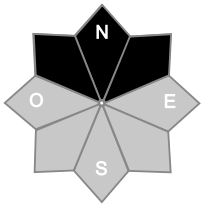


Au-dessus de 2200m indice de risque limité, plus bas indice faible.

**Départs spontanés :** départs superficiels au soleil ou par surcharge du au vent.

**Déclenchements provoqués :** instabilités superficielles dans la neige ventée.

Indices de risque : 5 très fort - 4 fort - 3 marqué - 2 limité - 1 faible -- En noir : les pentes les plus dangereuses

## Stabilité du manteau neigeux

**Situation avalancheuse typique :** neige ventée

**Déclenchements provoqués :** des instabilités sont en place dans la neige ventée, de rares en formation par le fort vent de nord-ouest là où il reste éventuellement encore de la neige légère et transportable. Elles sont présentes plutôt au-dessus de 2000/2200 m en versants froids, et en toutes orientations aux plus hautes altitudes du massif. Elles sont facilement identifiables, d'aspect durcie par le vent et localisées même loin des crêtes et ruptures de pentes. Elles peuvent encore être déclenchables par le passage d'un skieur et génèrent des avalanches de taille petite (taille 1), voire moyenne (taille 2) aux plus hautes altitudes du massif.

**Départs spontanés :** avalanches de petite taille ou sous forme de boulettes dans les pentes raides ensoleillées. Un départ par surcharge du au vent (rupture de corniche par exemple) est également possibles : avalanche petite à moyenne.

## Qualité de la neige

**L'enneigement** est excédentaire pour une fin mars.

**Limite d'enneigement skiable** : dès 1200/1300 m en ubacs favorables (terrains herbeux, pistes forestières), 1700/1800 m en adrets pas trop raides.

**État de la neige de surface** : neige récente fortement travaillée par le vent. Nombreuses congères dans les pentes. Sur les crêtes, d'épaisses corniches côtoient des zones dégarnies voire pelées par le vent.
En versant sud, neige croutée sous 2200/2400, s'humidifiant en journée.

## Aperçu météo pour le lundi 30 mars

| nuit | matin | après-midi | soir |
|---|---|---|---|
| | | | |

Ensoleillé en journée. Vent de nord devenant tempétueux l'après-midi. Quelques flocons vers l'Isère en soirée.

| | | | | |
|---|---|---|---|---|
| **Pluie-Neige** | | | | 1 000 m |
| **Iso 0 °C** | 2 000 m | 2 500 m | 2 200 m | 2 000 m |
| **Vent 2000 m** | ↓ 35 km/h | ↓ 55 km/h | ↓ 90 km/h | ↓ 90 km/h |
| **Vent 3000 m** | ↙ 50 km/h | ↓ 80 km/h | ↓ 100 km/h | ↓ 120 km/h |

## Épaisseur de neige hors-piste

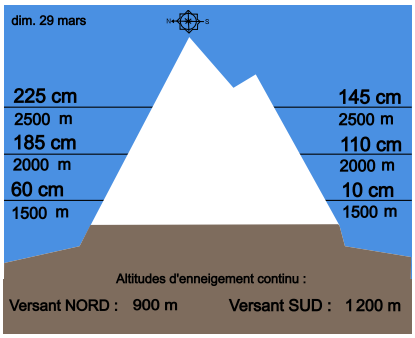


## Précipitations à 1800 m

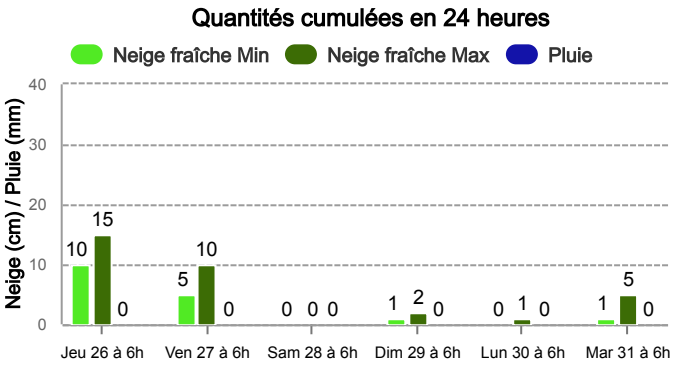


## Tendance du mardi 31 mars

**Indice de risque limité**

Maintien d'un risque limité. Les températures fraîches limitent l'activité en neige humide et le fort vent a de moins en moins d'influence sur un manteau neigeux déjà bien durci.

Pour consulter la vigilance en cours, veuillez vous rendre sur le site https://vigilance.meteofrance.fr/fr

Météo-France - 73 avenue de Paris, 94165 Saint-Mandé cedex - Contact : contact@meteo.fr

Rédigé par Météo-France avec la contribution des observateurs du réseau nivo-météorologiques. Partenariat : ANMSM (Maires de Stations de Montagne), DSF (Domaines Skiables de France), ADSP (Directeurs de Pistes et de la Sécurité des Stations de Sports d'Hiver) et autres acteurs de la montagne.

Bulletin neige & avalanches par téléphone au
0 892 68 10 20 Service 0,35 € / min + prix appel

RÉPUBLIQUE FRANÇAISE
*Liberté Égalité Fraternité*

METEO FRANCE
À VOS CÔTÉS, DANS UN CLIMAT QUI CHANGE

# Bulletin d'estimation du risque d'avalanche

## (valable en dehors des pistes balisées et ouvertes)

# MASSIF : Devoluy

Rédigé le dimanche 29 mars 2026 à 16h

## Conditions nivo-météo des 7 derniers jours

| | lun. 23/03 | | | | mar. 24/03 | | | | mer. 25/03 | | | | jeu. 26/03 | | | | ven. 27/03 | | | | sam. 28/03 | | | | dim. 29/03 | | | |
|---|---|---|---|---|---|---|---|---|---|---|---|---|---|---|---|---|---|---|---|---|---|---|---|---|---|---|---|---|
| | 03h | 09h | 15h | 21h | 03h | 09h | 15h | 21h | 03h | 09h | 15h | 21h | 03h | 09h | 15h | 21h | 03h | 09h | 15h | 21h | 03h | 09h | 15h | 21h | 03h | 09h | 15h | 21h |
| Météo | | | | | | | | | | | | | | | | | | | | | | | | | | | | |
| Vent (km/h) | 20 | 15 | 20 | 15 | 15 | 15 | 20 | 20 | 20 | 50 | 70 | 90 | 100 | 90 | 80 | 70 | 80 | 80 | 30 | 15 | 35 | 55 | 65 | 75 | 30 | 25 | 20 | 25 |
| à 3000m | | | | | | | | | | | | | | | | | | | | | | | | | | | | |
| Vent (km/h) | 15 | 15 | 20 | 15 | 10 | 10 | 10 | 5 | 10 | 20 | 55 | 80 | 90 | 80 | 70 | 70 | 60 | 60 | 20 | 20 | 25 | 35 | 65 | 60 | 50 | 35 | 45 | 30 |
| à 2000m | | | | | | | | | | | | | | | | | | | | | | | | | | | | |

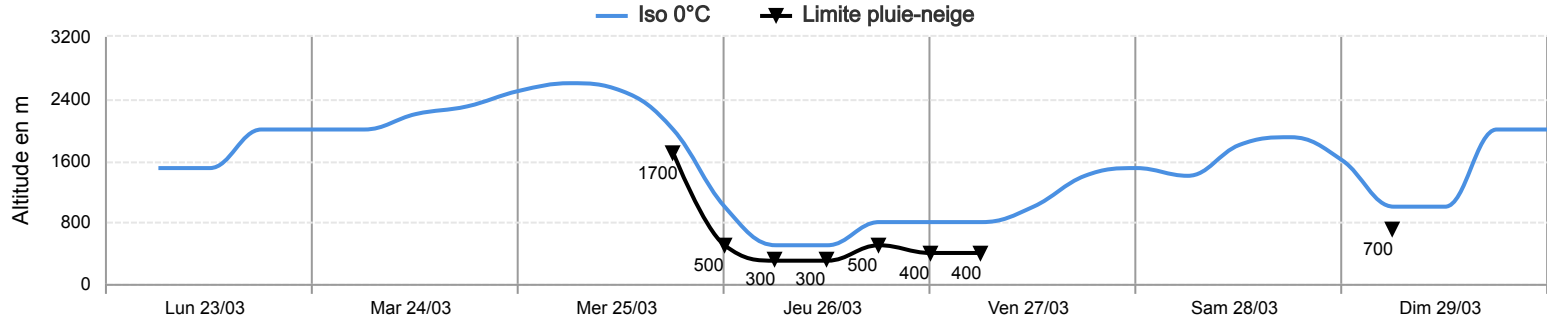


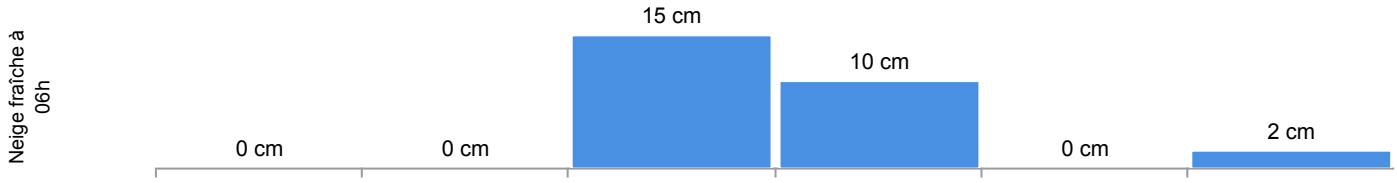


| Risque d'avalanche | lun. 23/03 | mar. 24/03 | mer. 25/03 | jeu. 26/03 | ven. 27/03 | sam. 28/03 | dim. 29/03 |
|---|---|---|---|---|---|---|---|
| | 2 | 2 | 2 | 3 | 3 | 2 | 2 |

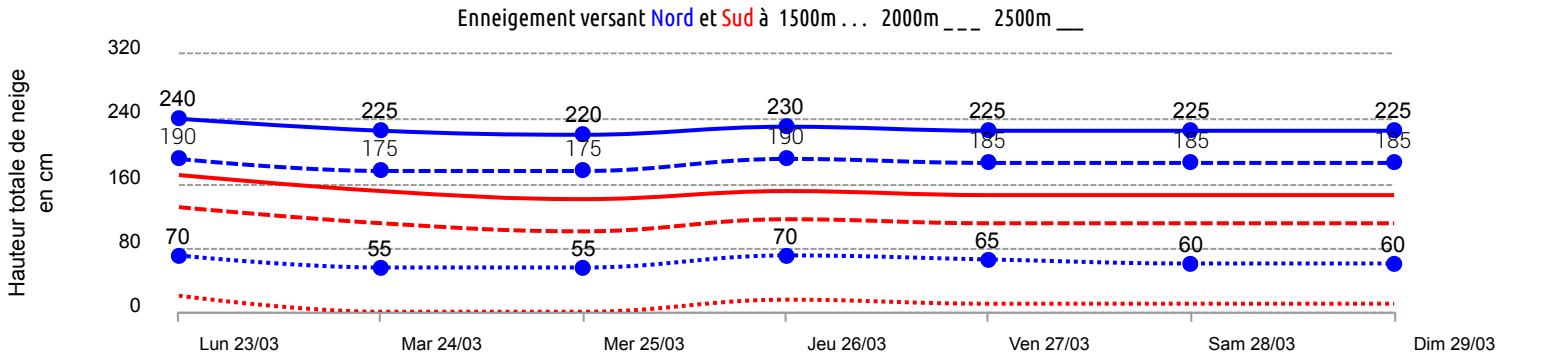


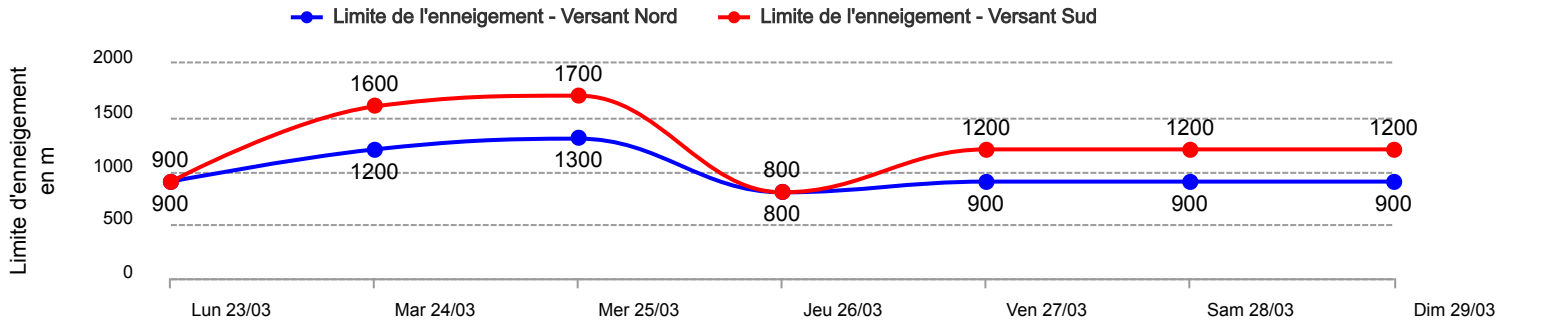


Pour consulter la vigilance en cours, veuillez vous rendre sur le site https://vigilance.meteofrance.fr/fr


**Météo-France - 73 avenue de Paris, 94165 Saint-Mandé cedex - Contact : contact@meteo.fr**


Rédigé par Météo-France avec la contribution des observateurs du réseau nivo-météorologiques. Partenariat : ANMSM (Maires de Stations de Montagne), DSF (Domaines Skiables de France), ADSP (Directeurs de Pistes et de la Sécurité des Stations de Sports d'Hiver) et autres acteurs de la montagne.

**Bulletin neige & avalanches par téléphone au**

**0 892 68 10 20** Service 0,35 € / min + prix appel