Bulletin d'estimation du risque d'avalanche
(valable en dehors des pistes balisées et ouvertes)

MASSIF : Embrunais Parpaillon

Rédigé le dimanche 29 mars 2026 à 16h

Estimation des risques pour le : LUNDI 30 MARS

PLAQUES EN PLACE DANS LA NEIGE RÉCENTE, FORMÉES JEUDI PAR LE VENT DE NORD

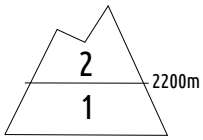

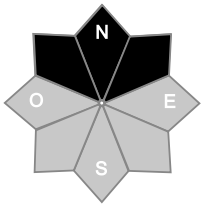

Au-dessus de 2200m indice de risque limité, plus bas indice faible.

Départs spontanés : départs superficiels au soleil ou par surcharge du au vent.

Déclenchements provoqués : instabilités superficielles dans la neige ventée, plus épaisses en altitude.

Indices de risque : 5 très fort - 4 fort - 3 marqué - 2 limité - 1 faible -- En noir : les pentes les plus dangereuses

Stabilité du manteau neigeux

Situation avalancheuse typique : neige ventée

Déclenchements provoqués : des instabilités sont en place dans la neige ventée, de rares en formation par le fort vent de nord-ouest là où il reste éventuellement encore de la neige légère et transportable. Elles sont présentes plutôt au-dessus de 2000/2200 m en versants froids, et en toutes orientations aux plus hautes altitudes du massif. Elles sont facilement identifiables, d'aspect durcie par le vent et localisées même loin des crêtes et ruptures de pentes. Elles peuvent encore être déclenchables par le passage d'un skieur et génèrent des avalanches de taille petite (taille 1), voire moyenne (taille 2) aux plus hautes altitudes du massif.

Départs spontanés : avalanches de petite taille ou sous forme de boulettes dans les pentes raides ensoleillées. Un départ par surcharge du au vent (rupture de corniche par exemple) est également possibles : avalanche petite à moyenne.

Qualité de la neige

L'enneigement est proche des normales pour une fin mars.
Hauteurs de neige observées : 108 cm à la nivôse du Parpaillon à 2500 m.

Limite d'enneigement skiable : au plus bas à 1400/1500 m en ubacs bien protégés ou sur pistes forestières, plutôt 2000/2100 m en adrets.

État de la neige de surface : 5/7 cm de neige récente légère à proximité de l'Ubaye. Elle repose sur une neige durcie par le vent, localement encore légère dans les secteurs bien abrités. Crêtes parfois décapées. En versant sud, neige croutée sous 2200/2400, s'humidifiant en journée.

Aperçu météo pour le lundi 30 mars

nuit	matin	après-midi	soir

Bien ensoleillé en journée. Vent de nord devenant tempétueux l'après-midi. Passages nuageux en soirée.

Pluie-Neige				
Iso 0 °C	1 800 m	2 200 m	2 300 m	1 800 m
Vent 2000 m	10 km/h	20 km/h	40 km/h	55 km/h
Vent 3000 m	30 km/h	60 km/h	80 km/h	100 km/h

Épaisseur de neige hors-piste

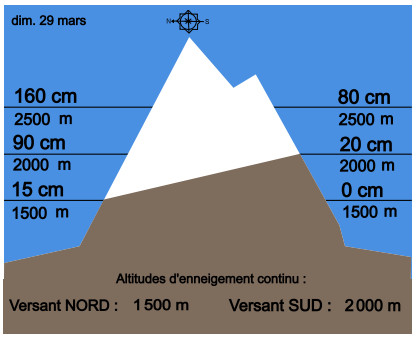

Précipitations à 1800 m

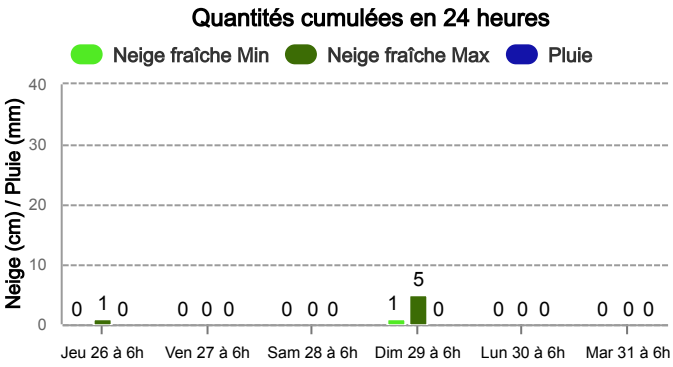

Tendance du mardi 31 mars

Indice de risque limité

Maintien d'un risque limité. Les températures fraîches limitent l'activité en neige humide et le fort vent a de moins en moins d'influence sur un manteau neigeux déjà bien durci.

Pour consulter la vigilance en cours, veuillez vous rendre sur le site https://vigilance.meteofrance.fr/fr

Météo-France - 73 avenue de Paris, 94165 Saint-Mandé cedex - Contact : contact@meteo.fr

Rédigé par Météo-France avec la contribution des observateurs du réseau nivo-météorologiques. Partenariat : ANMSM (Maires de Stations de Montagne), DSF (Domaines Skiables de France), ADSP (Directeurs de Pistes et de la Sécurité des Stations de Sports d'Hiver) et autres acteurs de la montagne.

Bulletin neige & avalanches par téléphone au 0 892 68 10 20 Service 0,35 € / min + prix appel

RÉPUBLIQUE FRANÇAISE
Liberté Égalité Fraternité

METEO FRANCE
À VOS CÔTÉS, DANS UN CLIMAT QUI CHANGE

Bulletin d'estimation du risque d'avalanche

(valable en dehors des pistes balisées et ouvertes)

MASSIF : Embrunais Parpaillon

Rédigé le dimanche 29 mars 2026 à 16h

Conditions nivo-météo des 7 derniers jours

	lun. 23/03				mar. 24/03				mer. 25/03				jeu. 26/03				ven. 27/03				sam. 28/03				dim. 29/03			
	03h	09h	15h	21h	03h	09h	15h	21h	03h	09h	15h	21h	03h	09h	15h	21h	03h	09h	15h	21h	03h	09h	15h	21h	03h	09h	15h	21h
Météo																												
Vent (km/h)	25	25	25	30	25	15	15	15	30	50	60	70	30	60	70	70	50	40	30	10	30	25	30	25	25	40	25	20
à 3000m																												
Vent (km/h)	15	15	15	10	10	10	20	5	10	15	50	30	20	50	60	50	45	40	20	10	10	10	20	20	20	30	25	15
à 2000m																												

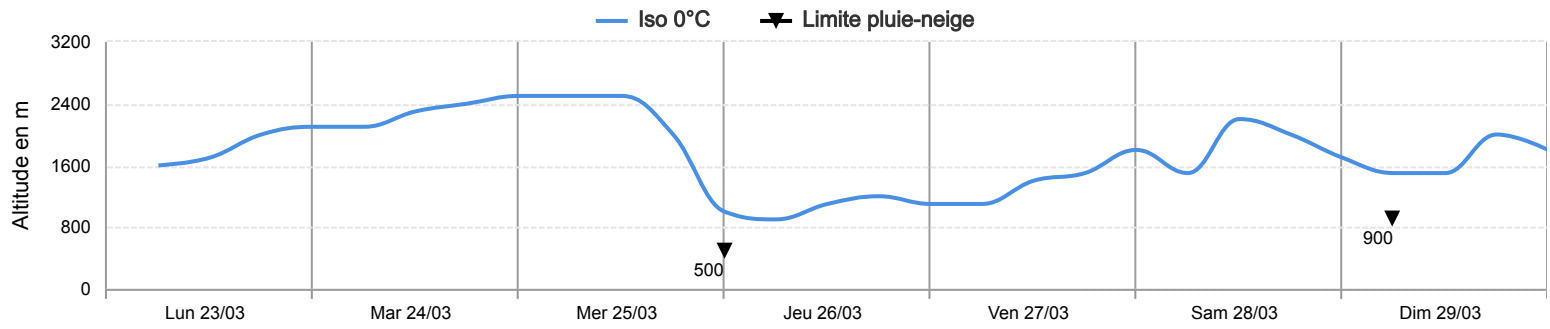

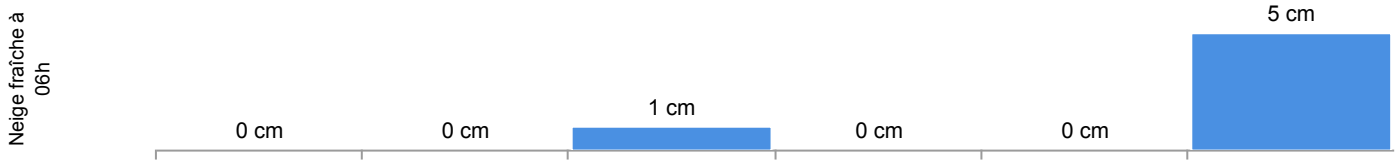

Risque d'avalanche	lun. 23/03	mar. 24/03	mer. 25/03	jeu. 26/03	ven. 27/03	sam. 28/03	dim. 29/03
	2	2	2	3	2	2	2

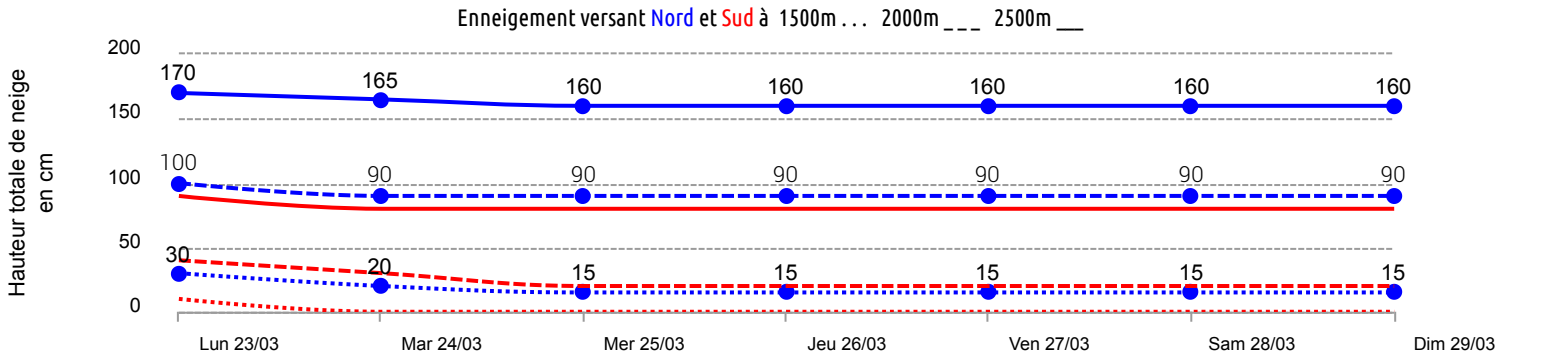

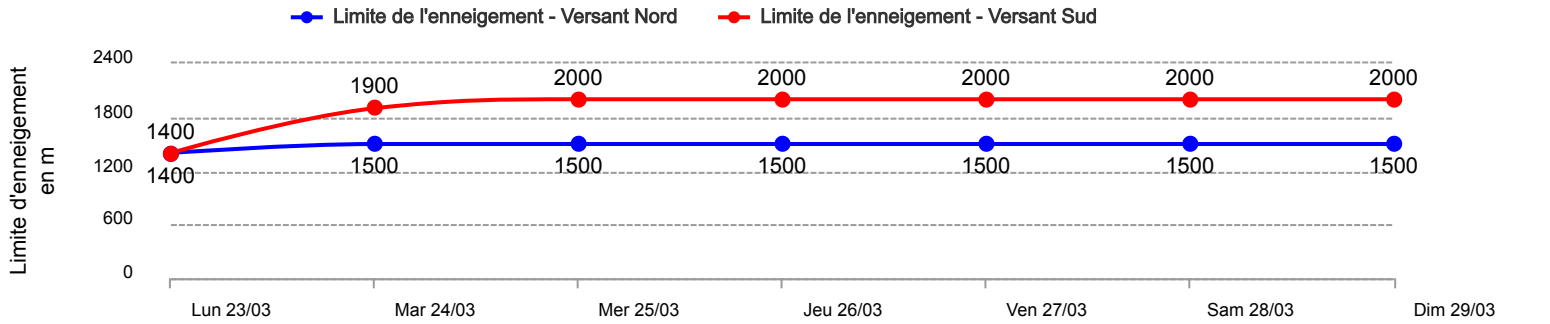

Pour consulter la vigilance en cours, veuillez vous rendre sur le site https://vigilance.meteofrance.fr/fr

Météo-France - 73 avenue de Paris, 94165 Saint-Mandé cedex - Contact : contact@meteo.fr

Rédigé par Météo-France avec la contribution des observateurs du réseau nivo-météorologiques. Partenariat : ANMSM (Maires de Stations de Montagne), DSF (Domaines Skiables de France), ADSP (Directeurs de Pistes et de la Sécurité des Stations de Sports d'Hiver) et autres acteurs de la montagne.

Bulletin neige & avalanches par téléphone au

0 892 68 10 20 Service 0,35 € / min + prix appel