Bulletin d'estimation du risque d'avalanche
(valable en dehors des pistes balisées et ouvertes)

MASSIF : Haute-Maurienne

Rédigé le dimanche 29 mars 2026 à 16h

Estimation des risques pour le : LUNDI 30 MARS

NOUVEAU EPISODE DE NEIGE ET VENT FORT SUR UN MANTEAU GLOBALEMENT ASSEZ BIEN STABILISÉ.

2

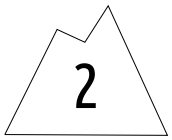

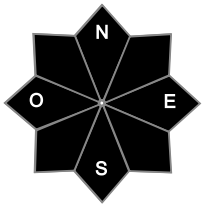

Indice de risque limité.

Départs spontanés : Peu probable

Déclenchements provoqués : Quelques plaques en neige ventée,

Indices de risque : 5 très fort - 4 fort - 3 marqué - 2 limité - 1 faible -- En noir : les pentes les plus dangereuses

Stabilité du manteau neigeux

Situation avalancheuse typique : neige ventée

Déclenchements provoqués : Quelques plaques en neige ventée, très localisées mais possible un peu en tous versants. D'une part, il subsiste d'anciennes plaques datant des épisodes de la semaine dernière, elles sont plutôt dures et désormais assez peu réactives au passage d'un skieur. D'autre part, la petite chute de neige attendu ce lundi après midi et l'épisode de vent fort, vont créer quelques nouvelles instabilités sous le vent de Nord et souvent loin des crêtes pelées par les nombreux épisodes de vent. Les cassures sont limitées, généralement 20-30 cm, jusqu'à 50 cm si une plaque dure un peu plus ancienne est déclenchée, donnant alors une avalanche de taille moyenne.
***Observables** : fissures sous les skis, accumulation de neige un peu plus dense derrière une rupture de pente loin des crêtes.*

Départs spontanés : peu probable. En fin de journée et soirée le transport de neige par le vent pourrait finir par faire se décrocher spontanément une plaque dans un secteur de dépot sous le vent de Nord à Nord-ouest

Qualité de la neige

Enneigement : encore un peu au dessus de la moyenne, sauf aux plus basses altitudes où les hauteurs de neige sont tout juste correctes pour la saison.

Limite skiable : vers 1300 m en Nord, 1700 m en Sud.

Qualité de la neige : En Nord, neige poudreuse peu épaisse 5/10cm en général , légère, sur un fond généralement plus ferme .
En sud la neige fraiche s'est alourdi et est maintenant souvent croutée avec juste le léger saupoudrage de ce samedi par dessus.
En cours de journée de lundi, dans les secteurs qui vont prendre le vent, les conditions de ski vont se dégrader avec du carton/ neige dure en remplacement progressif de la petite couche de poudre.

Aperçu météo pour le lundi 30 mars

nuit	matin	après-midi	soir

Nuageux le matin, petite chute de neige après midi et surtout soirée (2/5 cm) . Vent très fort de Nord sur crête frontière dès l'après midi

Pluie-Neige			1 300 m	1 100 m
Iso 0 °C	1 700 m	2 100 m	2 000 m	1 600 m
Vent 2500 m	↘ 20 km/h	↘ 55 km/h	↘ 70 km/h	↘ 70 km/h
Vent 3500 m	↓ 50 km/h	↘ 95 km/h	↘ 105 km/h	↓ 90 km/h

Épaisseur de neige hors-piste

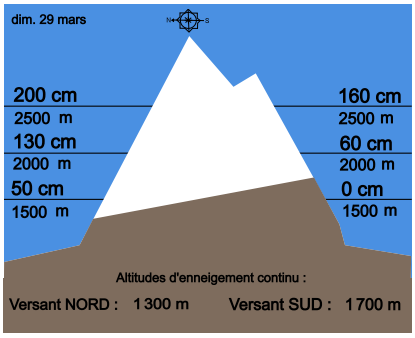

Précipitations à 1800 m

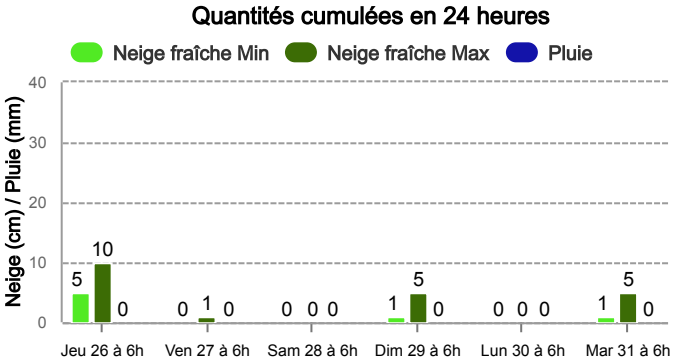

Tendance du mardi 31 mars

2

Indice de risque limité

Temps calme encore assez nuageux sauf haute altitude. Risque stationnaire

Pour consulter la vigilance en cours, veuillez vous rendre sur le site https://vigilance.meteofrance.fr/fr

Météo-France - 73 avenue de Paris, 94165 Saint-Mandé cedex - Contact : contact@meteo.fr

Rédigé par Météo-France avec la contribution des observateurs du réseau nivo-météorologiques. Partenariat : ANMSM (Maires de Stations de Montagne), DSF (Domaines Skiables de France), ADSP (Directeurs de Pistes et de la Sécurité des Stations de Sports d'Hiver) et autres acteurs de la montagne.

Bulletin neige & avalanches par téléphone au
0 892 68 10 20 Service 0,35 € / min + prix appel

RÉPUBLIQUE FRANÇAISE
Liberté Égalité Fraternité

METEO FRANCE
À VOS CÔTÉS, DANS UN CLIMAT QUI CHANGE

Bulletin d'estimation du risque d'avalanche
(valable en dehors des pistes balisées et ouvertes)
MASSIF : Haute-Maurienne

Rédigé le dimanche 29 mars 2026 à 16h

Conditions nivo-météo des 7 derniers jours

	lun. 23/03				mar. 24/03				mer. 25/03				jeu. 26/03				ven. 27/03				sam. 28/03				dim. 29/03			
	03h	09h	15h	21h	03h	09h	15h	21h	03h	09h	15h	21h	03h	09h	15h	21h	03h	09h	15h	21h	03h	09h	15h	21h	03h	09h	15h	21h
Météo																												
Vent (km/h)	15	20	20	20	20	20	15	35	50	65	85	100	100	95	90	90	60	30	30	30	30	40	40	30	30	30	30	30
à 3500m																												
Vent (km/h)	15	10	15	10	10	10	10	15	25	45	70	85	90	80	75	70	50	25	20	20	20	30	30	20	20	20	20	20
à 2500m																												

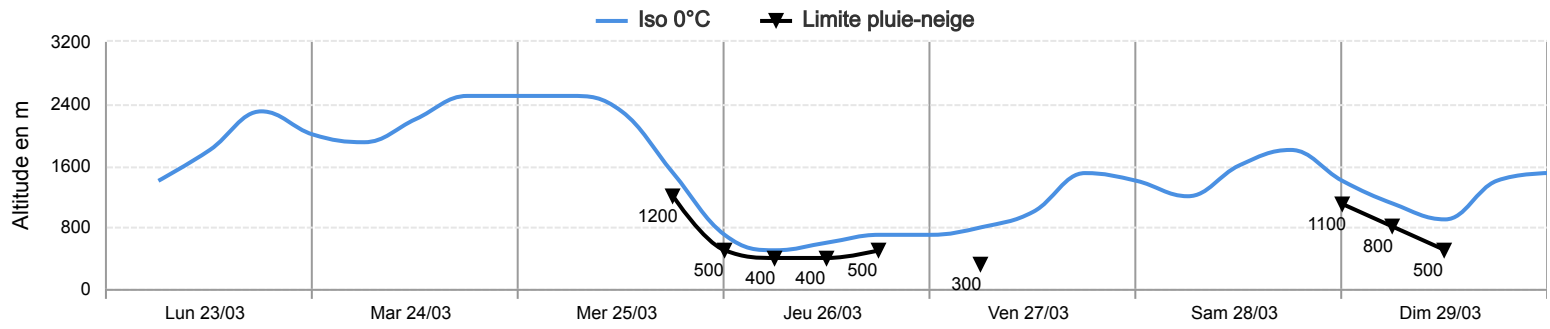

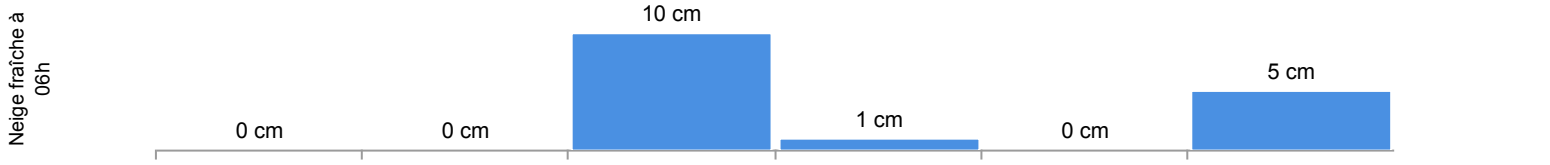

Risque d'avalanche	lun. 23/03	mar. 24/03	mer. 25/03	jeu. 26/03	ven. 27/03	sam. 28/03	dim. 29/03
	3	2	3	3	3	2	2

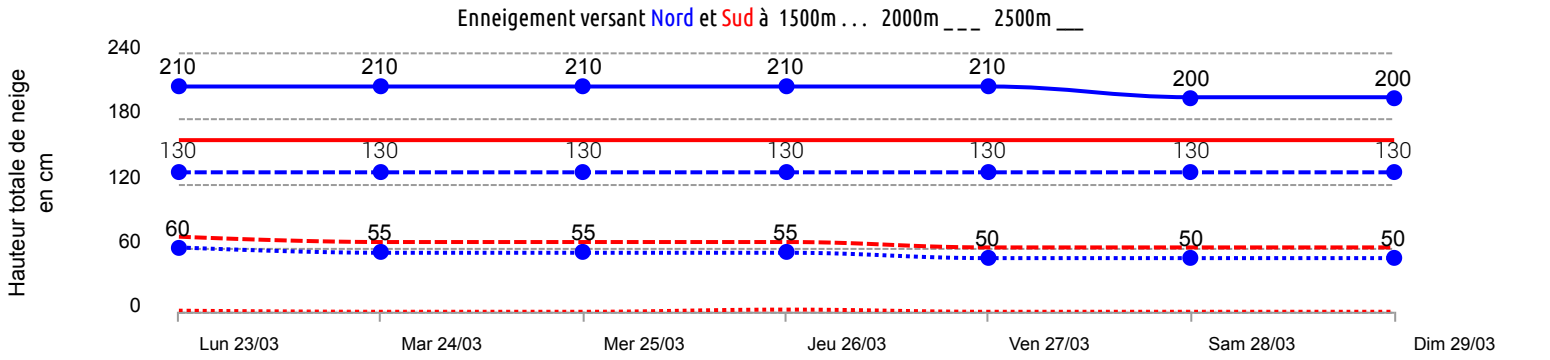

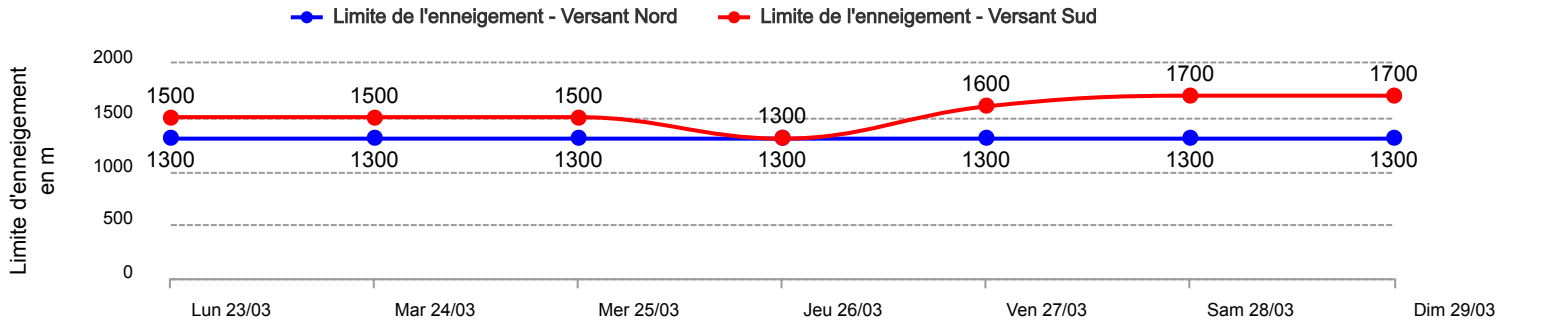

Pour consulter la vigilance en cours, veuillez vous rendre sur le site https://vigilance.meteofrance.fr/fr

Météo-France - 73 avenue de Paris, 94165 Saint-Mandé cedex - Contact : contact@meteo.fr

Bulletin neige & avalanches par téléphone au **0 892 68 10 20** Service 0,35 € / min + prix appel

Rédigé par Météo-France avec la contribution des observateurs du réseau nivo-météorologiques. Partenariat : ANMSM (Maires de Stations de Montagne), DSF (Domaines Skiables de France), ADSP (Directeurs de Pistes et de la Sécurité des Stations de Sports d'Hiver) et autres acteurs de la montagne.