Bulletin d'estimation du risque d'avalanche

(valable en dehors des pistes balisées et ouvertes)

MASSIF : Mont-Blanc

Rédigé le dimanche 29 mars 2026 à 16h

Estimation des risques pour le : LUNDI 30 MARS

2

2

N O E S

Indice de risque limité.

Départs spontanés : quelques accumulations par les vents de N peuvent céder

Déclenchements provoqués : plaques à vent dans la neige récente

Indices de risque : 5 très fort - 4 fort - 3 marqué - 2 limité - 1 faible -- En noir : les pentes les plus dangereuses

Stabilité du manteau neigeux

Situation avalancheuse typique : neige ventée

Déclenchements provoqués :

* **Plaques à vent dans la neige récente**. Plaques friables pour la plupart, éventuellement dures en secteurs très ventés. Formées sous l'effet du vent de N/NE ce week-end. Petite prudence dans les Aiguilles Rouges, ainsi que de Balme au glacier d'Argentière, où le vent de NE a soufflé fort (au moins une plaque à vent signalée ce dimanche, déclenchée par des randonneurs vers 2600 m).

* Formation de **nouvelles plaques ce lundi** sous l'effet du vent de NW (40/60 km/h au-dessus de 2800/3000 m). Plaques pas très larges, cassure 30/50 cm, localement réactives. Taille 1 à 2 (petite à moyenne).

Observables : accumulations, fissures devant les skis, changement de qualité de neige sur une courte distance.

* Anecdotique mais pas impossible : ces plaques reposent localement sur une couche fragile persistante enfouie. En versants N, au-dessus de 2200 m. Déclenchement par skieur très peu probable, mais départ possible en cascade (un première avalanche, ou une chute de corniche, déclenche une plaque épaisse). Taille 2 à 3 (moyenne à grande).

Départs spontanés :

Quelques accumulations de neige récente peuvent céder dans des pentes très raides, ou des entrées de couloirs chargés par le vent de NW, surtout au-dessus de 2800 m. Départs ponctuels ou en plaques peu larges. Taille 1, éventuellement 2.

Qualité de la neige

Enneigement :

Bon pour une fin mars. On peut chausser skis ou raquettes dès 1200/1300 m. Attention, absence de sous-couches sous 1500/1600 m en versants S.

Qualité de la neige ce lundi :

Neige majoritairement froide, dense, souple, sauf en versants S sous 2200 m où elle est déjà un peu croûtée. Neige soufflée dans les secteurs soumis à la Bise (Aiguilles Rouges, Balme, Autannes) ou au vent de NW. Arêtes dures, longues portions en glace en haute-montagne.

Aperçu météo pour le lundi 30 mars

nuit	matin	après-midi	soir

Brouillards givrants et giboulées. Quelques éclaircies furtives en milieu de journée. Frais, -5/-3 DG à 2000 m, -12/-15 à l'Aiguille du Midi.

Pluie-Neige		900 m	1 000 m	800 m
Iso 0 °C	1 300 m	1 200 m	1 300 m	1 200 m
Vent 2000 m	↗ 10 km/h	↘ 20 km/h	↘ 30 km/h	↓ 40 km/h
Vent 4000 m	↘ 70 km/h	↓ 80 km/h	↓ 90 km/h	↓ 100 km/h

Épaisseur de neige hors-piste

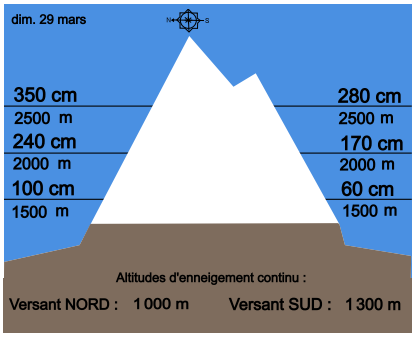

Précipitations à 1800 m

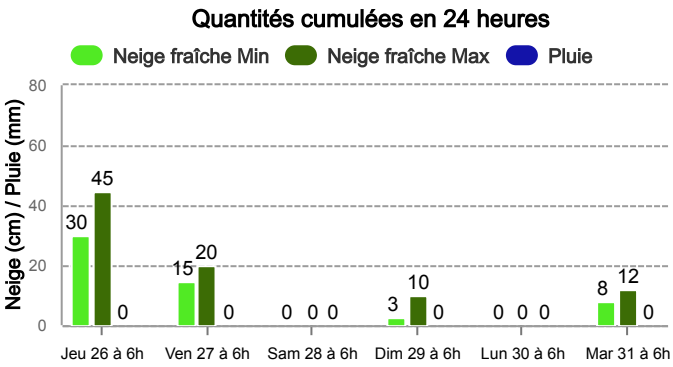

Tendance du mardi 31 mars

2

Indice de risque limité

Petite chute de neige la nuit de lundi à mardi, formant de nouvelles plaques friables. Tempête et plaques à vent en haute-montagne.

Pour consulter la vigilance en cours, veuillez vous rendre sur le site https://vigilance.meteofrance.fr/fr

Météo-France - 73 avenue de Paris, 94165 Saint-Mandé cedex - Contact : contact@meteo.fr

Rédigé par Météo-France avec la contribution des observateurs du réseau nivo-météorologiques. Partenariat : ANMSM (Maires de Stations de Montagne), DSF (Domaines Skiables de France), ADSP (Directeurs de Pistes et de la Sécurité des Stations de Sports d'Hiver) et autres acteurs de la montagne.

Bulletin neige & avalanches par téléphone au 0 892 68 10 20 Service 0,35 € / min + prix appel

RÉPUBLIQUE FRANÇAISE
Liberté Égalité Fraternité

METEO FRANCE
À VOS CÔTÉS, DANS UN CLIMAT QUI CHANGE

Bulletin d'estimation du risque d'avalanche

(valable en dehors des pistes balisées et ouvertes)

MASSIF : Mont-Blanc

Rédigé le dimanche 29 mars 2026 à 16h

Conditions nivo-météo des 7 derniers jours

	lun. 23/03				mar. 24/03				mer. 25/03				jeu. 26/03				ven. 27/03				sam. 28/03				dim. 29/03			
	03h	09h	15h	21h	03h	09h	15h	21h	03h	09h	15h	21h	03h	09h	15h	21h	03h	09h	15h	21h	03h	09h	15h	21h	03h	09h	15h	21h
Météo																												
Vent (km/h)	30	40	40	40	40	25	20	15	25	90	110	90	90	90	90	80	60	80	50	70	60	50	30	40	50	40	40	50
à 4000m																												
Vent (km/h)	20	15	10	10	5	5	5	5	10	50	60	50	50	50	40	35	40	50	30	20	30	30	20	30	40	30	20	10
à 2000m																												

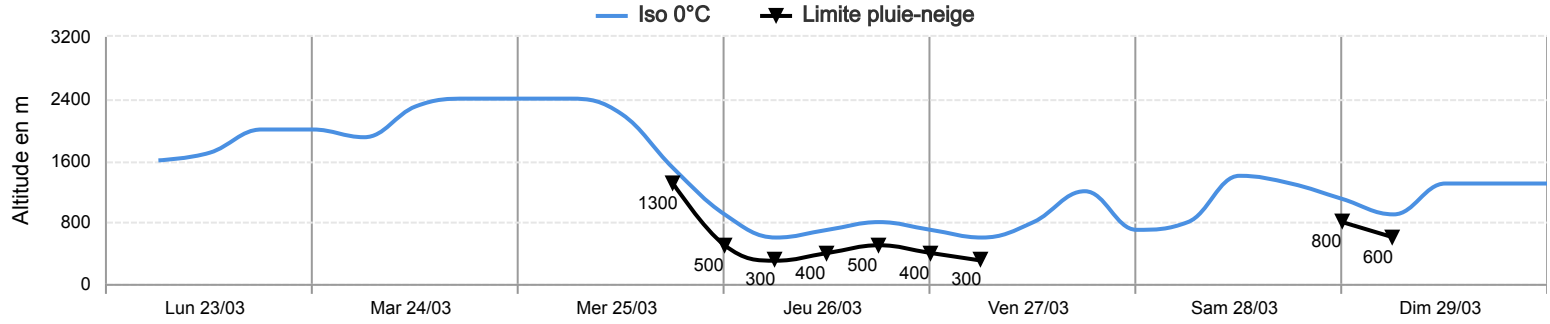

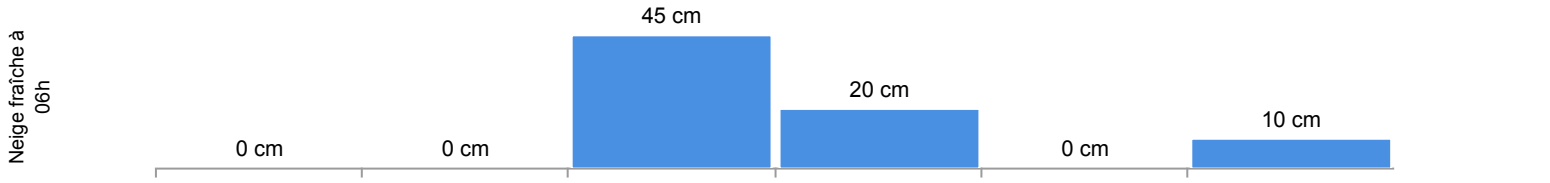

Risque d'avalanche	lun. 23/03	mar. 24/03	mer. 25/03	jeu. 26/03	ven. 27/03	sam. 28/03	dim. 29/03
	3	2	3	4	4	3	2

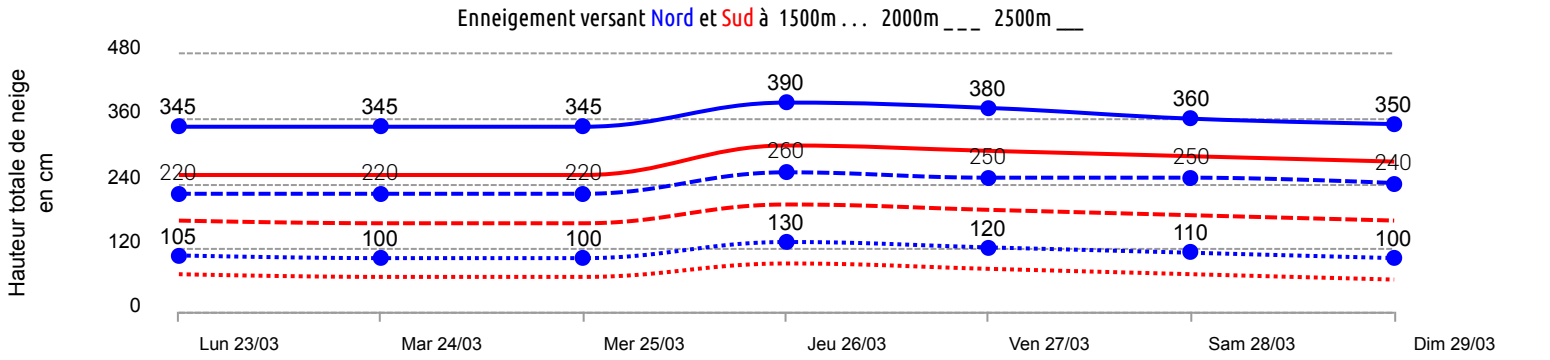

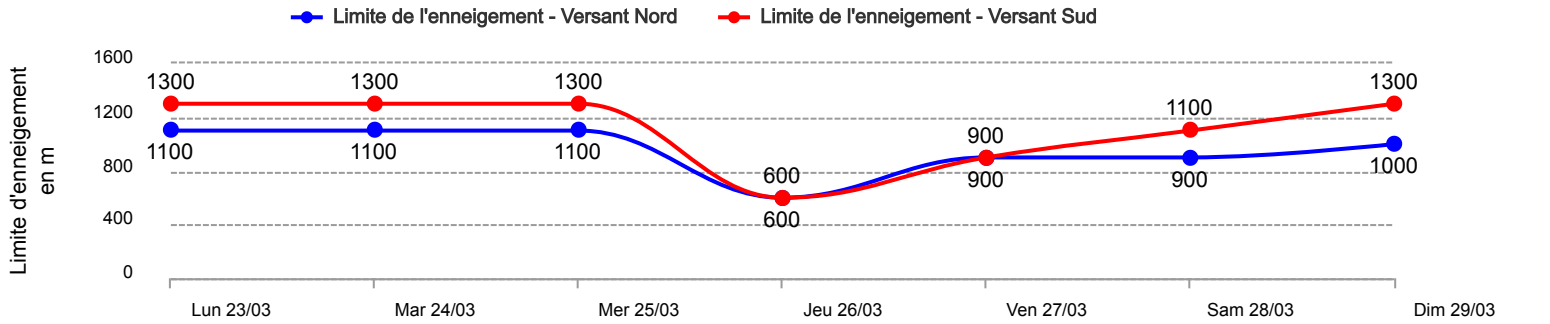

Pour consulter la vigilance en cours, veuillez vous rendre sur le site https://vigilance.meteofrance.fr/fr

Météo-France - 73 avenue de Paris, 94165 Saint-Mandé cedex - Contact : contact@meteo.fr

Bulletin neige & avalanches par téléphone au

0 892 68 10 20 Service 0,35 € / min + prix appel

Rédigé par Météo-France avec la contribution des observateurs du réseau nivo-météorologiques. Partenariat : ANMSM (Maires de Stations de Montagne), DSF (Domaines Skiables de France), ADSP (Directeurs de Pistes et de la Sécurité des Stations de Sports d'Hiver) et autres acteurs de la montagne.