Bulletin d'estimation du risque d'avalanche

(valable en dehors des pistes balisées et ouvertes)

MASSIF : Thabor

Rédigé le dimanche 29 mars 2026 à 16h

Estimation des risques pour le : LUNDI 30 MARS

PLAQUES EN PLACE DANS LA NEIGE RÉCENTE VENTÉE

2

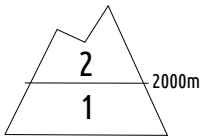

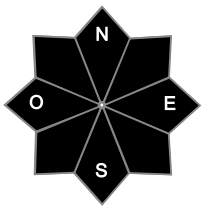

Au-dessus de 2000m indice de risque limité, plus bas indice faible.

Départs spontanés : départs superficiels au soleil ou par surcharge du au vent.

Déclenchements provoqués : instabilités dans la neige ventée, plus nombreuses vers la Savoie.

Indices de risque : 5 très fort - 4 fort - 3 marqué - 2 limité - 1 faible -- En noir : les pentes les plus dangereuses

Stabilité du manteau neigeux

Situation avalancheuse typique : neige ventée

Déclenchements provoqués : des instabilités sont en place dans la neige ventée, de rares en formation par le fort vent de nord-ouest là où il reste éventuellement encore de la neige légère et transportable. Présentes en toutes orientations au-dessus de 2000/2200 m environ, elles sont néanmoins plus nombreuses et sensibles dans les orientations d'un large secteur nord (nord-ouest, nord et nord-est) ainsi que vers la Savoie où les quantités de neige récente sont un peu plus importantes. Elles sont facilement identifiables, d'aspect durcie par le vent et localisées même loin des crêtes et ruptures de pentes. Elles peuvent encore être déclenchables par le passage d'un skieur et génèrent des avalanches de taille petite à moyenne (taille 1 à 2).

Départs spontanés : avalanches de petite taille ou sous forme de boulettes dans les pentes raides ensoleillées. Un départ par surcharge du au vent (rupture de corniche par exemple) est également possibles : avalanche petite à moyenne.

Qualité de la neige

L'enneigement est proche des normales pour une fin mars.
Hauteurs de neige observées vers 2500 m : 172 cm dans le vallon du Chardonnet, 127 cm à la nivôse des Rochilles, 82 cm à la Nivôse du Galibier (secteurs fortement ventés).

Limite d'enneigement skiable : dès 1400 m en ubacs favorables (terrains herbeux, pistes forestières), 1800/1900 m en adrets pas trop raides.

État de la neige de surface : 5/10 cm de neige récente à proximité de la Savoie, fortement durcie et travaillée par le fort vent ou encore localement légère dans les secteurs bien abrités. Sur les crêtes, d'épaisses corniches côtoient des zones pelées par le vent. En versant sud, neige croutée sous 2200/2400, s'humidifiant en journée.

Aperçu météo pour le lundi 30 mars

nuit	matin	après-midi	soir

Ensoleillé en journée. Vent de nord devenant tempétueux l'après-midi. Quelques flocons vers la Savoie en soirée.

Pluie-Neige				1 000 m
Iso 0 °C	2 000 m	2 100 m	2 000 m	1 700 m
Vent 2000 m	↘ 30 km/h	↓ 45 km/h	↘ 60 km/h	↘ 60 km/h
Vent 3000 m	↓ 30 km/h	↘ 70 km/h	↘ 90 km/h	↘ 90 km/h

Épaisseur de neige hors-piste

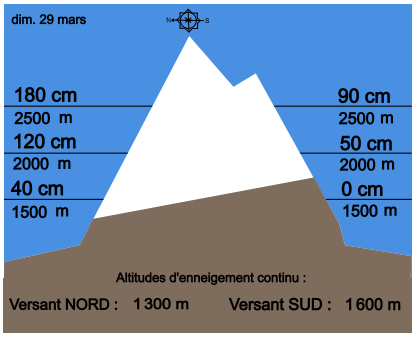

Précipitations à 1800 m

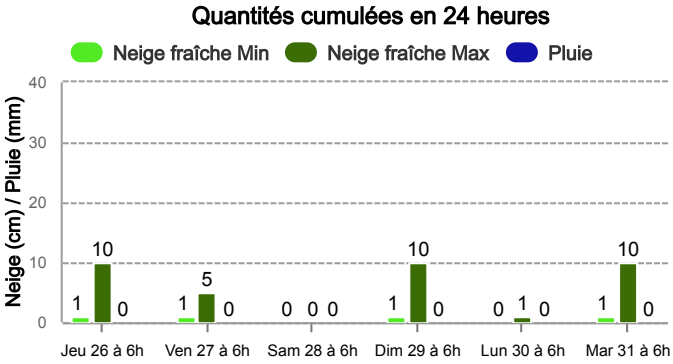

Tendance du mardi 31 mars

2

Indice de risque limité

Maintien d'un risque limité. Les températures fraîches limitent l'activité en neige humide et le fort vent a de moins en moins d'influence sur un manteau neigeux déjà bien durci.

Pour consulter la vigilance en cours, veuillez vous rendre sur le site https://vigilance.meteofrance.fr/fr

Météo-France - 73 avenue de Paris, 94165 Saint-Mandé cedex - Contact : contact@meteo.fr

Rédigé par Météo-France avec la contribution des observateurs du réseau nivo-météorologiques. Partenariat : ANMSM (Maires de Stations de Montagne), DSF (Domaines Skiables de France), ADSP (Directeurs de Pistes et de la Sécurité des Stations de Sports d'Hiver) et autres acteurs de la montagne.

Bulletin neige & avalanches par téléphone au
0 892 68 10 20 Service 0,35 € / min + prix appel

RÉPUBLIQUE FRANÇAISE
Liberté Égalité Fraternité

METEO FRANCE
À VOS CÔTÉS, DANS UN CLIMAT QUI CHANGE

Bulletin d'estimation du risque d'avalanche

(valable en dehors des pistes balisées et ouvertes)

MASSIF : Thabor

Rédigé le dimanche 29 mars 2026 à 16h

Conditions nivo-météo des 7 derniers jours

	lun. 23/03				mar. 24/03				mer. 25/03				jeu. 26/03				ven. 27/03				sam. 28/03				dim. 29/03			
	03h	09h	15h	21h	03h	09h	15h	21h	03h	09h	15h	21h	03h	09h	15h	21h	03h	09h	15h	21h	03h	09h	15h	21h	03h	09h	15h	21h
Météo																												
Vent (km/h)	30	15	20	20	20	15	15	15	30	50	70	80	90	90	80	70	65	50	30	30	30	40	50	60	45	20	30	30
à 3000m																												
Vent (km/h)	20	15	20	15	10	10	15	10	15	25	70	70	60	55	50	45	40	35	15	15	20	30	40	35	35	20	30	25
à 2000m																												

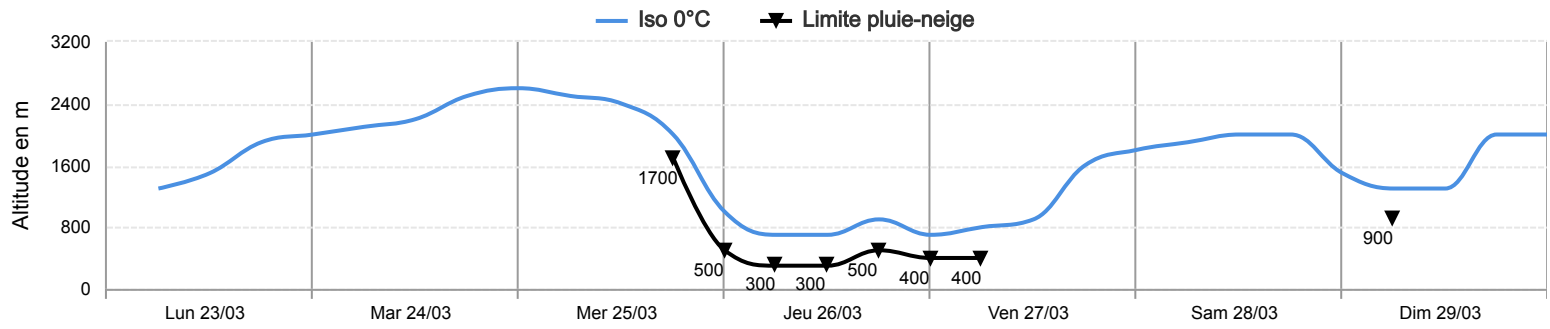

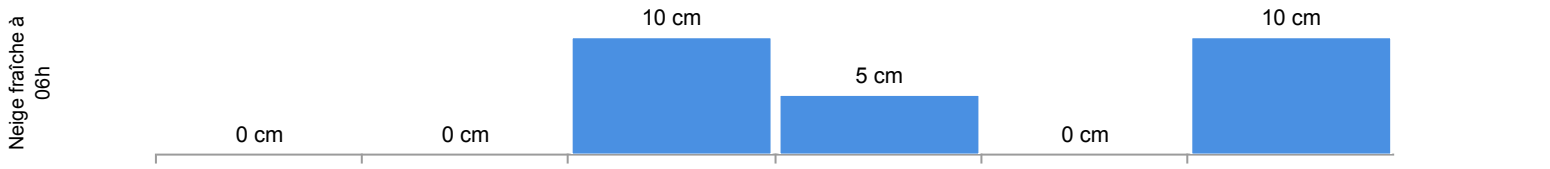

Risque d'avalanche	lun. 23/03	mar. 24/03	mer. 25/03	jeu. 26/03	ven. 27/03	sam. 28/03	dim. 29/03
	2	2	2	3	3	2	2

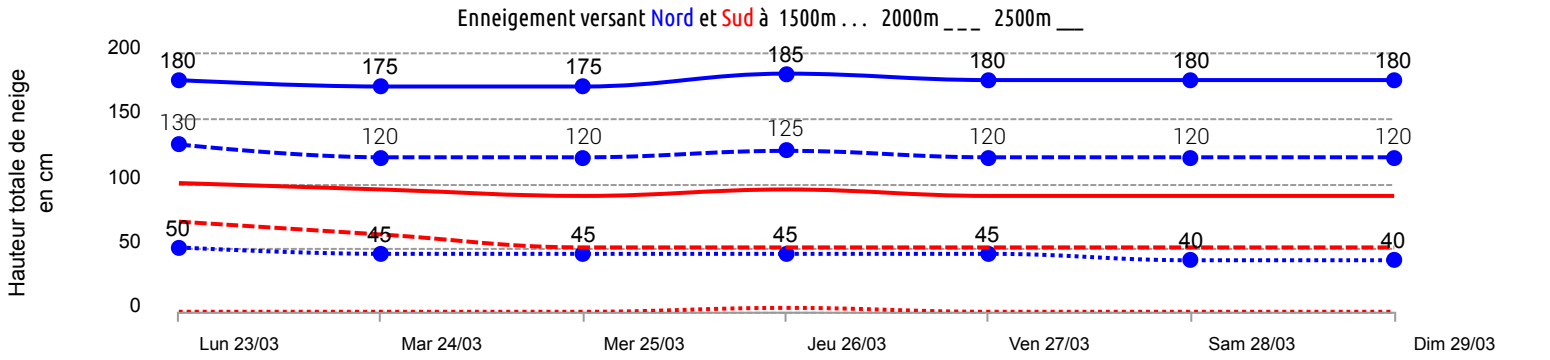

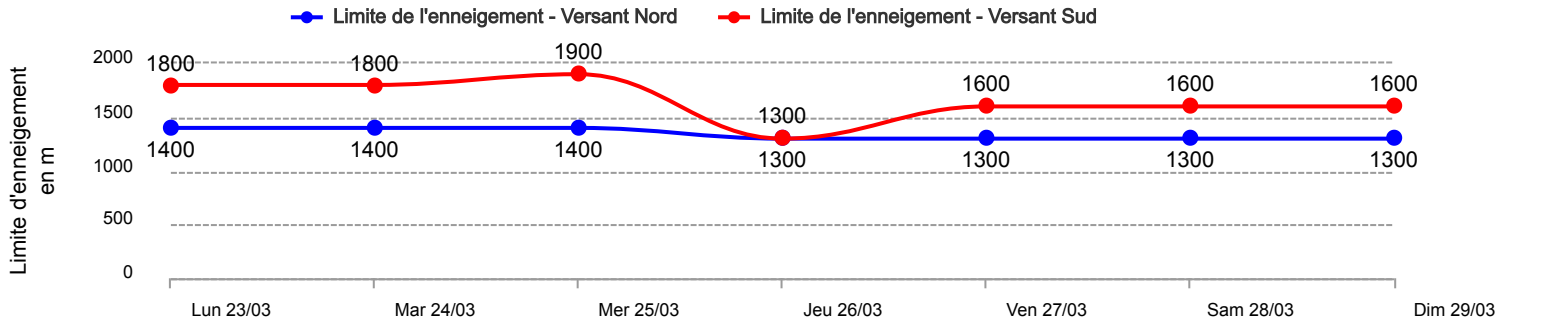

Pour consulter la vigilance en cours, veuillez vous rendre sur le site https://vigilance.meteofrance.fr/fr

Météo-France - 73 avenue de Paris, 94165 Saint-Mandé cedex - Contact : contact@meteo.fr

Rédigé par Météo-France avec la contribution des observateurs du réseau nivo-météorologiques. Partenariat : ANMSM (Maires de Stations de Montagne), DSF (Domaines Skiables de France), ADSP (Directeurs de Pistes et de la Sécurité des Stations de Sports d'Hiver) et autres acteurs de la montagne.

Bulletin neige & avalanches par téléphone au
0 892 68 10 20 Service 0,35 € / min + prix appel