# Bulletin d'estimation du risque d'avalanche

(valable en dehors des pistes balisées et ouvertes)

# MASSIF : Haute-Ariege

Rédigé le dimanche 29 mars 2026 à 17h

## Estimation des risques pour le : LUNDI 30 MARS

**INSTABILITÉS DANS LES CHUTES DE NEIGE VENTÉE RÉCENTES ET STRUCTURES DE PLAQUES PLUS ÉPAISSES EN ALTITUDE**

3

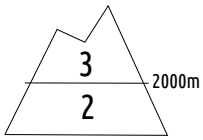


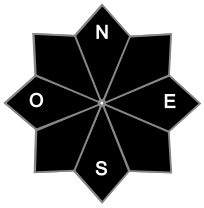


Au-dessus de 2000m indice de risque marqué, plus bas indice limité.

**Départs spontanés :** Quelques départs ponctuels emportant la neige récente dans les pentes raides

**Déclenchements provoqués :** Avalanches de plaques facilement déclenchables dans les chutes de neige ventée récentes, parfois plus épaisses en cas de couche fragile enfouie

Indices de risque : 5 très fort - 4 fort - 3 marqué - 2 limité - 1 faible -- En noir : les pentes les plus dangereuses

## Stabilité du manteau neigeux

**Situation avalancheuse typique :** neige ventée couche fragile persistante

**Déclenchements provoqués :**

Avalanches de plaques déclenchables au passage d'un skieur : de nouvelles structures de plaques, parfois loin des crêtes, sont présentes et se forment par transport de la neige récente tombée depuis samedi. Les accumulations sont plutôt à attendre dans les versants d'un large Sud, mais pas seulement. De plus, au-dessus de 2000/2200m, des couches fragiles (grains anguleux, givre de surface, voire neige roulée) peuvent encore être enfouies, donnant des cassures plus épaisses et des avalanches de taille plus importantes (taille 2 à rare 3). Ces plaques seront plutôt dures en altitude et à proximités des crêtes et ruptures de pentes, parfois plus friables et plus difficilement identifiables à plus basse altitude et dans les endroits abrités du vent.

*Observables : Quantité de neige fraiche, surface hétérogène travaillée par le vent, fissures devant les skis, "woomfs".*

**Départs spontanés :**

Avalanches de taille petite à moyenne possibles en neige humide le matin dans les pentes raides des secteurs Est prenant le soleil, puis en journée par humidification dans les nuages sous 2000m. Sinon, plus en altitude, des départs spontanés en neige sèche sont aussi possibles dans les pentes raides, par surcharge par transport de neige par le vent.

## Qualité de la neige

**Enneigement :**

L'enneigement reste très bon pour la saison, après plusieurs hivers déficitaires. En altitude, les cumuls sont très conséquents, mais les crêtes et sommets exposés au vent d'ouest à nord-ouest sont souvent dégarnis.

Avec les nouvelles chutes de neige à basse altitude, il est envisageable de chausser sur la neige fraîche vers 1200/1300 m mais on retrouvera une sous-couche plus ancienne plutôt à partir de 1500/1600 m qui permet de progresser plus sereinement.

**Qualité de la neige :**

Lundi matin, la montagne garde un bel aspect hivernal avec la présence de neige dès 800m, puis quelques cm de neige fraiche souvent sous forme de neige roulée dès 1000m et rapidement 10 à 20 cm à partir de 1500m. Vers le haut du massif, l'enneigement sera assez hétérogène sous l'action du vent soufflant depuis samedi, avec des zones d'accumulations et des crêtes Ouest à Nord-Ouest pelées ou en neige dure. En journée, avec la remontée des températures et les nuages, la neige va s'humidifier en surface jusqu'à 1800/2000m mais on pourra trouver plus haut quelques combes abritées en neige légère et poudreuse.

## Aperçu météo pour le lundi 30 mars

| | nuit | matin | après-midi | soir |
|---|---|---|---|---|
| | | | | |

Courte accalmie lundi matin avant le retour de nuages et de précipitations l'après-midi. Vent de nord toujours soutenu.

| | | | | |
|---|---|---|---|---|
| **Pluie-Neige** | | | 1 700 m | 1 500 m |
| **Iso 0 °C** | 1 000 m | 1 800 m | 2 100 m | 1 900 m |
| **Vent 2000 m** | ↓ 35 km/h | ↓ 30 km/h | ↓ 45 km/h | ↓ 50 km/h |
| **Vent 3000 m** | ↓ 60 km/h | ↓ 60 km/h | ↓ 65 km/h | ↓ 70 km/h |

## Épaisseur de neige hors-piste

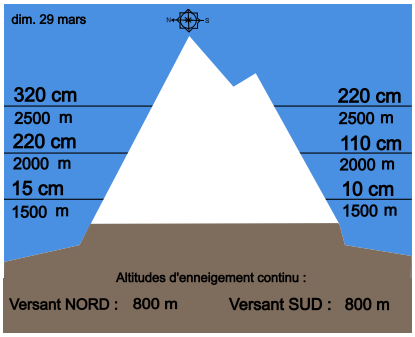


## Précipitations à 1800 m

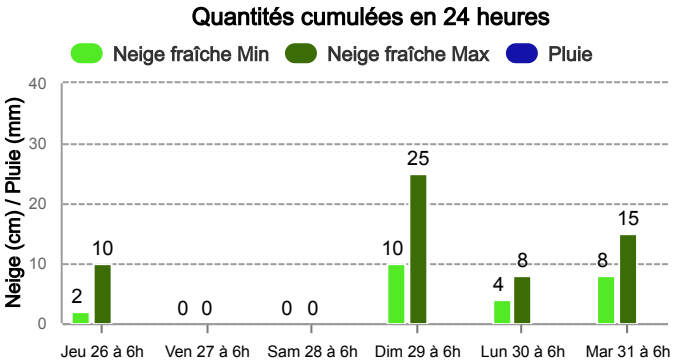


## Tendance du mardi 31 mars

3 **Indice de risque marqué**

Stationnaire avec encore du vent et du transport de neige prévu en altitude.

Pour consulter la vigilance en cours, veuillez vous rendre sur le site https://vigilance.meteofrance.fr/fr

Météo-France - 73 avenue de Paris, 94165 Saint-Mandé cedex - Contact : contact@meteo.fr

Rédigé par Météo-France avec la contribution des observateurs du réseau nivo-météorologiques. Partenariat : ANMSM (Maires de Stations de Montagne), DSF (Domaines Skiables de France), ADSP (Directeurs de Pistes et de la Sécurité des Stations de Sports d'Hiver) et autres acteurs de la montagne.

Bulletin neige & avalanches par téléphone au **0 892 68 10 20** Service 0,35 € / min + prix appel

RÉPUBLIQUE FRANÇAISE
*Liberté Égalité Fraternité*

METEO FRANCE
À VOS CÔTÉS, DANS UN CLIMAT QUI CHANGE

# Bulletin d'estimation du risque d'avalanche

## (valable en dehors des pistes balisées et ouvertes)

# MASSIF : Haute-Ariege

Rédigé le dimanche 29 mars 2026 à 17h

## Conditions nivo-météo des 7 derniers jours

| | lun. 23/03 | | | | mar. 24/03 | | | | mer. 25/03 | | | | jeu. 26/03 | | | | ven. 27/03 | | | | sam. 28/03 | | | | dim. 29/03 | | | |
|---|---|---|---|---|---|---|---|---|---|---|---|---|---|---|---|---|---|---|---|---|---|---|---|---|---|---|---|---|
| | 03h | 09h | 15h | 21h | 03h | 09h | 15h | 21h | 03h | 09h | 15h | 21h | 03h | 09h | 15h | 21h | 03h | 09h | 15h | 21h | 03h | 09h | 15h | 21h | 03h | 09h | 15h | 21h |
| Météo | | | | | | | | | | | | | | | | | | | | | | | | | | | | |
| Vent (km/h) | 45 | 35 | 20 | 15 | 15 | 15 | 15 | 15 | 30 | 35 | 45 | 75 | 85 | 85 | 80 | 75 | 80 | 80 | 65 | 45 | 40 | 45 | 70 | 90 | 100 | 100 | 85 | 65 |
| à 3000m | | | | | | | | | | | | | | | | | | | | | | | | | | | | |
| Vent (km/h) | 30 | 20 | 10 | 10 | 10 | 10 | 10 | 10 | 10 | 15 | 30 | 45 | 55 | 50 | 50 | 45 | 50 | 50 | 40 | 20 | 20 | 20 | 30 | 60 | 80 | 80 | 50 | 45 |
| à 2000m | | | | | | | | | | | | | | | | | | | | | | | | | | | | |

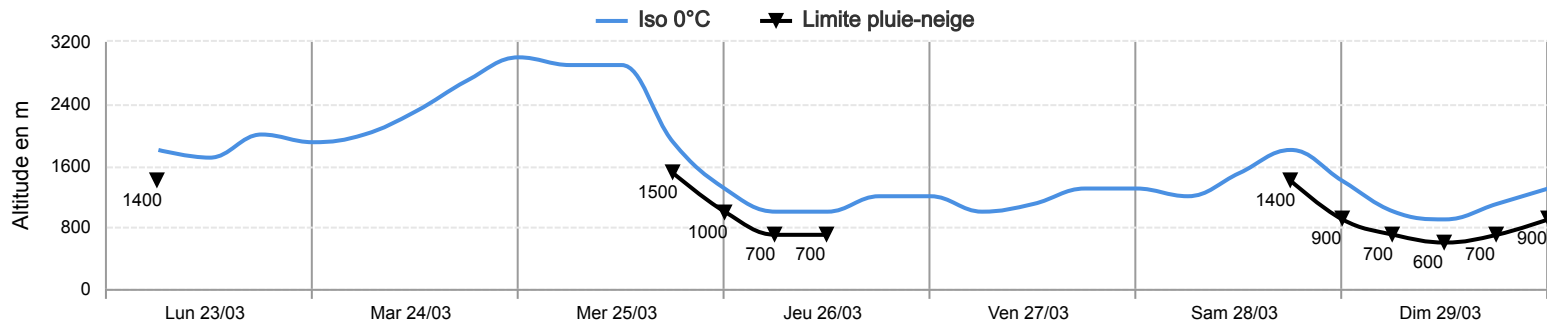


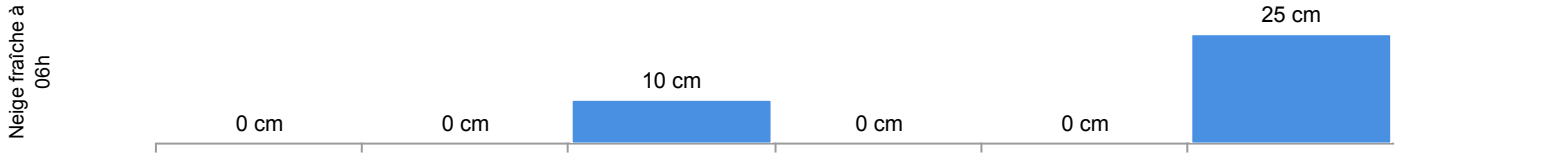


| Risque d'avalanche | lun. 23/03 | mar. 24/03 | mer. 25/03 | jeu. 26/03 | ven. 27/03 | sam. 28/03 | dim. 29/03 |
|---|---|---|---|---|---|---|---|
| | 3 | 2 | 2 | 2 | 2 | 2 | 3 |

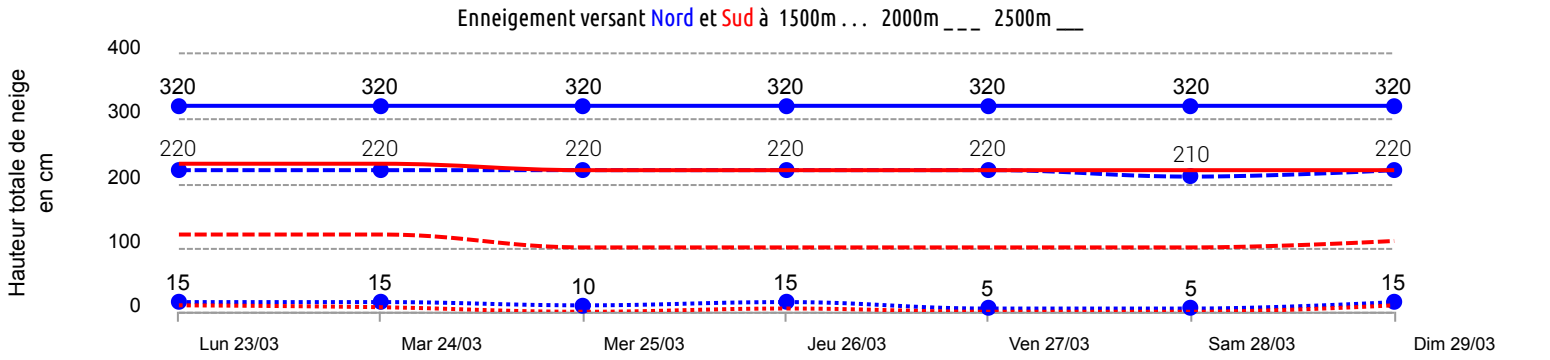


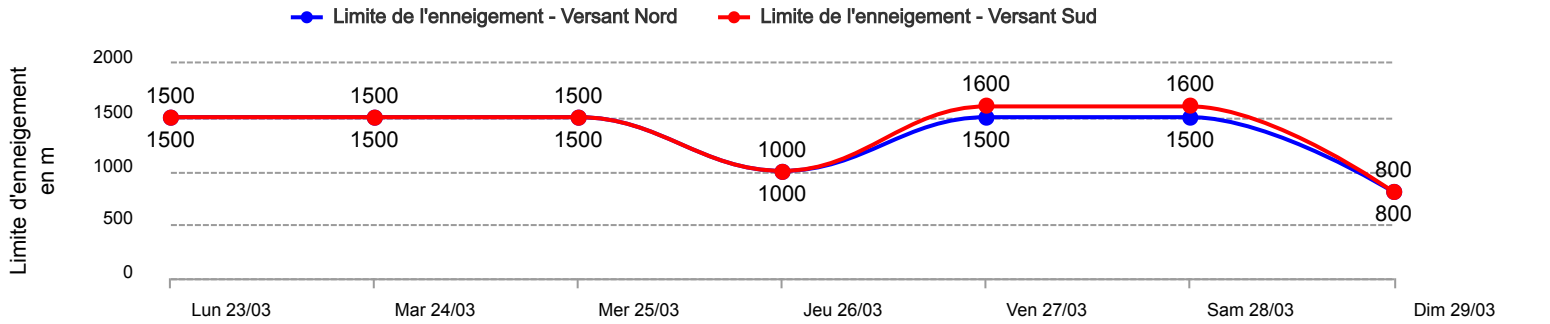


Pour consulter la vigilance en cours, veuillez vous rendre sur le site https://vigilance.meteofrance.fr/fr


Météo-France - 73 avenue de Paris, 94165 Saint-Mandé cedex - Contact : contact@meteo.fr



Rédigé par Météo-France avec la contribution des observateurs du réseau nivo-météorologiques. Partenariat : ANMSM (Maires de Stations de Montagne), DSF (Domaines Skiables de France), ADSP (Directeurs de Pistes et de la Sécurité des Stations de Sports d'Hiver) et autres acteurs de la montagne.



Bulletin neige & avalanches par téléphone au
0 892 68 10 20 Service 0,35 € / min + prix appel