Bulletin d'estimation du risque d'avalanche

(valable en dehors des pistes balisées et ouvertes)

MASSIF : Pays-Basque

Rédigé le dimanche 29 mars 2026 à 17h

Estimation des risques pour le : LUNDI 30 MARS

PLAQUES FORMÉES SOUS UN FORT VENT DE NORD, EN MATINÉE, REDOUX L'APRÈS-MIDI.

3

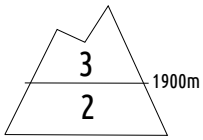

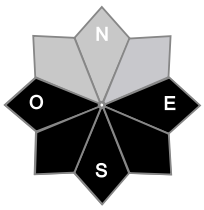

Plaques

Au-dessus de 1900m indice de risque marqué, plus bas indice limité.

Départs spontanés : Départs ponctuels au soleil, rares départs de plaques sous le vent

Déclenchements provoqués : Plaques facilement déclenchables mais bien visibles

Indices de risque : 5 très fort - 4 fort - 3 marqué - 2 limité - 1 faible -- En noir : les pentes les plus dangereuses

Stabilité du manteau neigeux

Situation avalancheuse typique : neige ventée neige humide

Déclenchements provoqués :
Des plaques sont présentes dans un large secteur sud, dans les zones à l'abri du vent fort de nord, jusqu'à loin des cols et crêtes. Elles sont facilement déclenchables, composées d'un mélange de neige roulée et de neige fraîche très travaillée par le vent. Elles sont assez facilement identifiables, bien différenciées des zones en glace pelées par le vent fort.
Sous 1900m, en l'absence de sous-couches en versants sud, les accumulations formées sont moins enclines à engendrer une avalanche.

Départs spontanés :
- Des départs spontanés des plaques décrites ci-dessus sont possibles par surcharge par la neige transportée par le vent. Ils devraient rester rares car le vent a tendance à faiblir et il devrait rester peu de neige transportable après la tempête de dimanche. Le transport encore en cours, crêtes qui fument, traces recouvertes, est un bon indicateur de ce risque.
- Des départs ponctuels de taille petite à moyenne, dans la neige fraîche, sont attendus le matin dans les versants ensoleillés, principalement à proximité des rochers. L'après-midi, ils sont possibles en toutes expositions, avec l'humidification par le brouillard et la remontée de l'isotherme 0°C.

Qualité de la neige

Enneigement : Correct pour la saison au-dessus de 1800m, mais restant assez maigre en versants exposés au vent d'ouest. Les nouvelles chutes de neige depuis samedi soir ont blanchi les sols dès 900-1000m.
État de la neige : Alternance de zones érodées par le vent où émerge la neige ancienne, regelée, et de zones où la neige fraîche s'est accumulée. Elle y est de texture variable, parfois poudreuse dans les les zones bien abritées, mais le plus souvent durcie par le vent. L'après-midi, la neige récente s'humidifie dans le brouillard sous 2000m.

Aperçu météo pour le lundi 30 mars

	nuit	matin	après-midi	soir

Soleil en début de journée, nuages en matinée. Relief bouché l'après-midi, pluie en moyenne montagne, quelques flocons plus haut.

Pluie-Neige	900 m	1 100 m	1 800 m	1 800 m
Iso 0 °C	1 200 m	1 600 m	2 200 m	2 300 m
Vent 1000 m	↓ 35 km/h	↓ 25 km/h	↓ 35 km/h	↓ 40 km/h
Vent 2000 m	↓ 60 km/h	↙ 45 km/h	↓ 50 km/h	↻ 50 km/h

Épaisseur de neige hors-piste

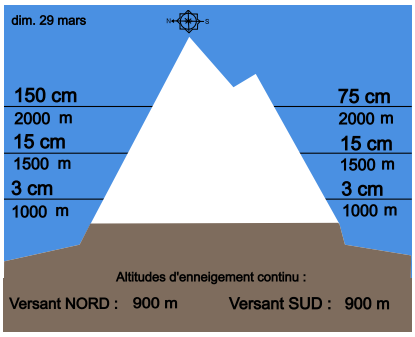

Précipitations à 1800 m

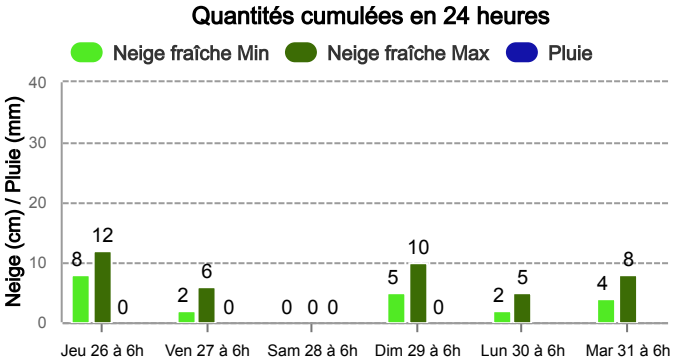

Tendance du mardi 31 mars

Indice de risque limité

Manteau neigeux stabilisé par le redoux relatif

Pour consulter la vigilance en cours, veuillez vous rendre sur le site https://vigilance.meteofrance.fr/fr

Météo-France - 73 avenue de Paris, 94165 Saint-Mandé cedex - Contact : contact@meteo.fr

Rédigé par Météo-France avec la contribution des observateurs du réseau nivo-météorologiques. Partenariat : ANMSM (Maires de Stations de Montagne), DSF (Domaines Skiables de France), ADSP (Directeurs de Pistes et de la Sécurité des Stations de Sports d'Hiver) et autres acteurs de la montagne.

Bulletin neige & avalanches par téléphone au

0 892 68 10 20 Service 0,35 € / min + prix appel

RÉPUBLIQUE FRANÇAISE
Liberté Égalité Fraternité

METEO FRANCE
À VOS CÔTÉS, DANS UN CLIMAT QUI CHANGE

Bulletin d'estimation du risque d'avalanche
(valable en dehors des pistes balisées et ouvertes)
MASSIF : Pays-Basque

Rédigé le dimanche 29 mars 2026 à 17h

Conditions nivo-météo des 7 derniers jours

	lun. 23/03				mar. 24/03				mer. 25/03				jeu. 26/03				ven. 27/03				sam. 28/03				dim. 29/03			
	03h	09h	15h	21h	03h	09h	15h	21h	03h	09h	15h	21h	03h	09h	15h	21h	03h	09h	15h	21h	03h	09h	15h	21h	03h	09h	15h	21h
Météo																												
Vent (km/h)	40	35	30	25	25	15	5	15	15	10	50	65	75	80	85	85	75	65	55	55	55	55	65	75	80	85	75	75
à 2000m																												
Vent (km/h)	25	25	25	15	10	10	2	5	5	2	15	25	35	40	50	50	35	35	35	25	20	25	40	45	45	40	50	40
à 1000m																												

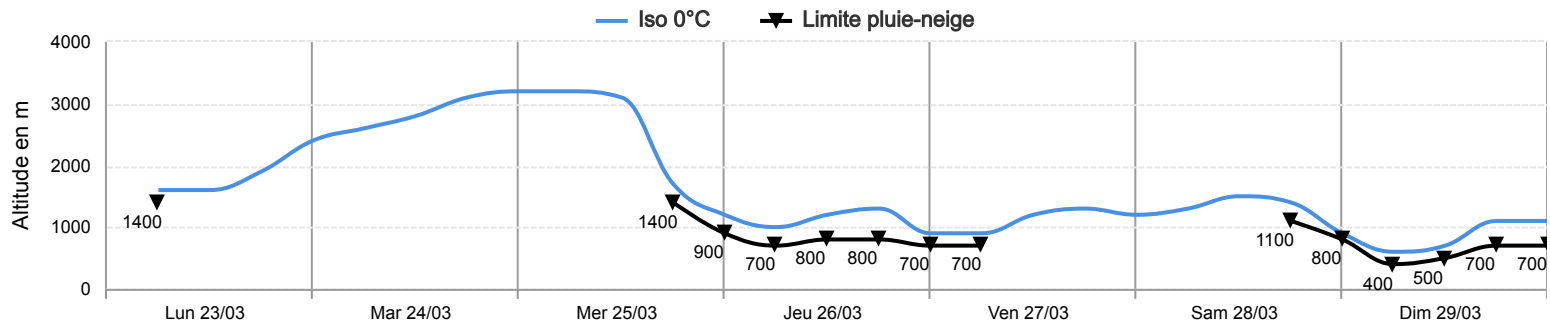

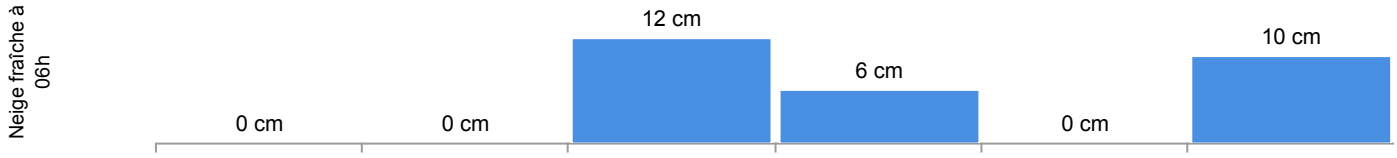

Risque d'avalanche	lun. 23/03	mar. 24/03	mer. 25/03	jeu. 26/03	ven. 27/03	sam. 28/03	dim. 29/03
	2	2	2	2	2	2	3

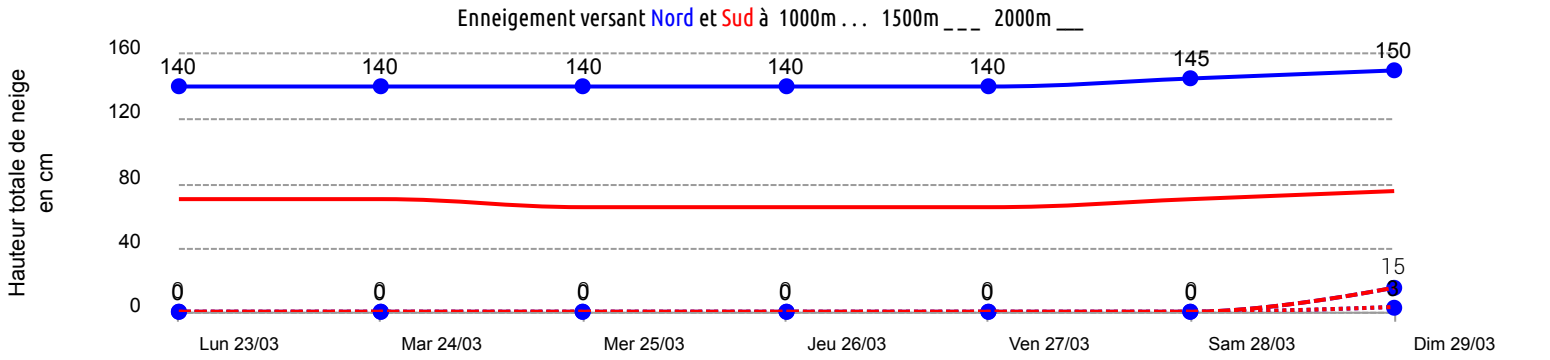

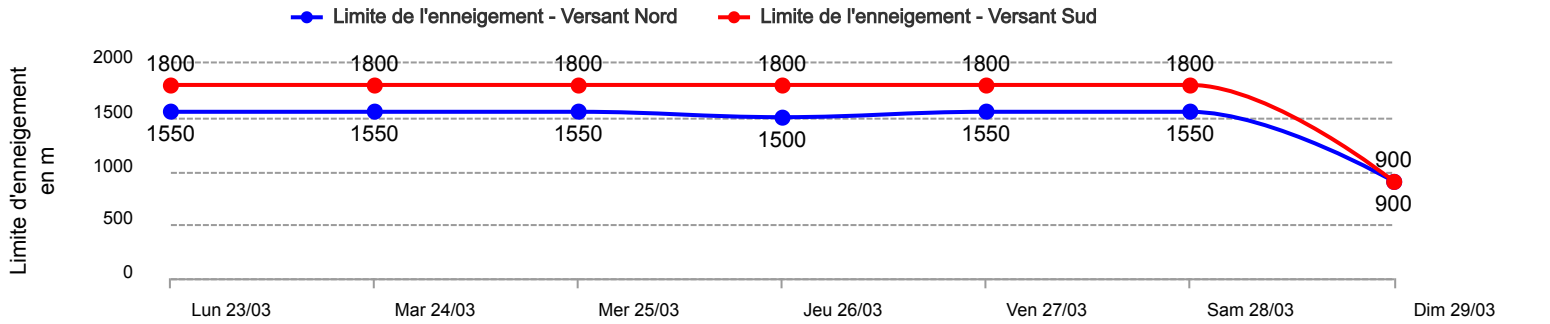

Pour consulter la vigilance en cours, veuillez vous rendre sur le site https://vigilance.meteofrance.fr/fr

Météo-France - 73 avenue de Paris, 94165 Saint-Mandé cedex - Contact : contact@meteo.fr

Rédigé par Météo-France avec la contribution des observateurs du réseau nivo-météorologiques. Partenariat : ANMSM (Maires de Stations de Montagne), DSF (Domaines Skiables de France), ADSP (Directeurs de Pistes et de la Sécurité des Stations de Sports d'Hiver) et autres acteurs de la montagne.

Bulletin neige & avalanches par téléphone au
0 892 68 10 20 Service 0,35 € / min + prix appel