GOBIERNO DE ESPAÑA
VICEPRESIDENCIA TERCERA DEL GOBIERNO
MINISTERIO PARA LA TRANSICIÓN ECOLÓGICA Y EL RETO DEMOGRÁFICO

Boletín de información nivológica y de peligro de aludes

Pirineo Catalán

aemet Agencia Estatal de Meteorología

lunes, 30 de marzo de 2026

Pronóstico hasta las 24 horas del martes, día 31 de marzo

(Válido fuera de pistas de esquí balizadas y abiertas)

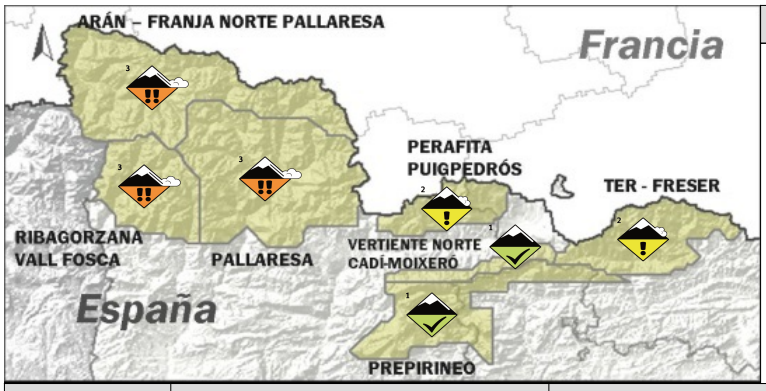

Problemas de aludes

Placas de viento

Nieve reciente

Macizo	Peligro	Problemas de aludes, cota, orientación, tamaño	Innivación observada (m)
Arán - Franja norte Pallaresa	3 Notable	**Placas de viento** 1800 N O E S 3 **Nieve reciente** N O E S 2	2026-03-30 N S Cota más baja caras N
Ribagorzana - Vall Fosca	3 Notable	**Placas de viento** 1800 N O E S 2 **Nieve reciente** N O E S 1	2026-03-30 N S Cota más baja caras N
Pallaresa	3 Notable	**Placas de viento** 1800 N O E S 2 **Nieve reciente** N O E S 1	2026-03-30 N S Cota más baja caras N

AEMET. Se autoriza la reproducción de su contenido citando la fuente.

Boletín de información nivológica y de peligro de aludes

Pirineo Catalán

Perafita - Puigpedrós	2 **Limitado**	**Placas de viento** 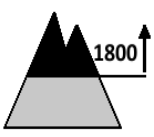  **Nieve reciente** 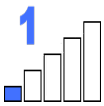	2026-03-30 Cota más baja caras N
Ter - Freser	2 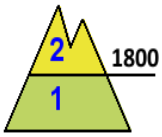 **Limitado**	**Placas de viento** 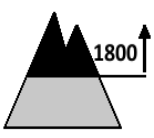  **Nieve reciente** 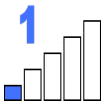	2026-03-30 Cota más baja caras N
Vertiente norte Cadí - Moixeró	1 **Débil**	**Placas de viento** 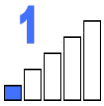	2026-03-30 Cota más baja caras N
Prepirineo	1 **Débil**	**Placas de viento** 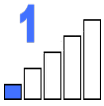	2026-03-30 Cota más baja caras N

Estado del manto y observaciones recientes

El intenso flujo de norte, que viene afectando a la cordillera durante ya unos cuantos días, se recrudeció durante la jornada de ayer dejando registros de temperaturas muy frías para la época, vientos especialmente intensos con rachas muy fuertes generalizadas, huracanadas en algunos puntos, y algunas nevadas con valores líquidos de 15-20 mm en el Arán F.N. Pallaresa y bastante más modestos en el resto.

La nieve nueva se distribuyó muy irregularmente a causa del viento, formando numerosas placas de viento que se intercalan con zonas en las que aflora la antigua costra. Las placas se han depositado sobre la propia costra, o también sobre facetas en umbrías de cotas altas. En puntos al abrigo de los vientos, se pueden encontrar acumulaciones de nieve reciente. Las antiguas capas débiles persistentes todavía pueden aparecer en niveles internos en las umbrías de cotas altas y mostrarse reactivas, aunque en general ante sobrecargas fuertes.

El manto presenta continuidad desde cotas medias, más abajo en las laderas norte que en las sur. Los espesores continúan muy por encima de lo habitual para estas fechas con valores por encima de 150-220 cm en cota 2200 en la mayoría de los sectores.

AEMET. Se autoriza la reproducción de su contenido citando la fuente.

Evolución del manto y peligro de aludes para el martes, día 31

Problema de placas de viento. Problema de nieve reciente y nieve húmeda.

Las placas de viento se mantendrán frágiles, susceptibles de colapsar ante sobrecargas débiles. Serán abundantes, sobre todo en orientaciones sur, y podrán aparecer ocasionalmente en cotas medias, así como alejadas de crestas y cordales. El tamaño de los potenciales aludes será mediano, localmente grande en Arán-F.N.Pallaresa.

Los aludes de nieve reciente también serán probables en zonas menos afectadas por el viento y con la suficiente inclinación. Podrán ser naturales y accidentales, y generalmente de tamaño pequeño.

En solanas inclinadas de cota media, se podrán producir algunas purgas de nieve húmeda, generalmente pequeñas.

Por último, en umbrías de cotas altas, no se descarta la posibilidad de activar alguna de las antiguas capas débiles persistentes más profundas, pudiendo desencadenar algún alud de tamaño grande.

Predicción meteorológica para el martes, día 31

Muy nuboso o cubierto en el Arán y norte de la Pallaresa, con visibilidad localmente reducida, abriendo grandes claros hacia el sur. Precipitaciones débiles o localmente moderadas en el Arán y norte de la Pallaresa, y con baja probabilidad en el Ripollés y Ribagorzana. Cota de nieve en torno a 1200-1400 metros, pudiendo descender temporalmente hasta los 1000. Temperaturas mínimas en ascenso moderado o notable. Máximas en ligero o moderado descenso. Heladas débiles, moderadas en cotas altas, donde podrán ser localmente fuertes y persistentes. Viento moderado o fuerte de componente norte, con rachas muy fuertes, incluso huracanadas, en cotas altas y zonas expuestas.

Datos en la atmósfera libre:

Altitud de la isoterma de 0 ºC: 1400 m (N) - 2000 m (S)
Altitud de la isoterma de -10 ºC: 4000 m

Viento a 1500 m: N 40 km/h
Viento a 3000 m: N 110 km/h

Evolución para el miércoles día 1

Nivel de peligro en ascenso con las nuevas nevadas.

Escala europea de peligro de aludes

Débil | Limitado | Notable | Fuerte | Muy Fuerte

Problemas de aludes

Nieve reciente | Placas de viento | Capas débiles persistentes | Nieve húmeda | Deslizamientos basales | Sin problema evidente

Nota1: Se recuerda que, siempre que haya nieve, la ausencia total de peligro no existe. Hay que tener presente que en circunstancias desfavorables, con aludes de tamaño 1 (alud pequeño o colada) y tamaño 2 (alud mediano), se pueden sufrir severos daños personales.

AEMET. Se autoriza la reproducción de su contenido citando la fuente.

Nota2: Los BPA se elaboran en base a información meteorológica así como al estado del manto nivoso a través de sondeos puntuales. Se advierte a los usuarios de la variabilidad de esta información al extrapolarla a zonas extensas de montaña. Por ello, AEMET no se hace responsable de su uso para la toma de decisiones que conciernen a la seguridad personal, ni de los riesgos físicos o materiales de ellas derivadas.

AEMET. Se autoriza la reproducción de su contenido citando la fuente.