aineva.it

Dienstag 31.03.2026

Aktualisiert am 30.03.2026 um 20:03

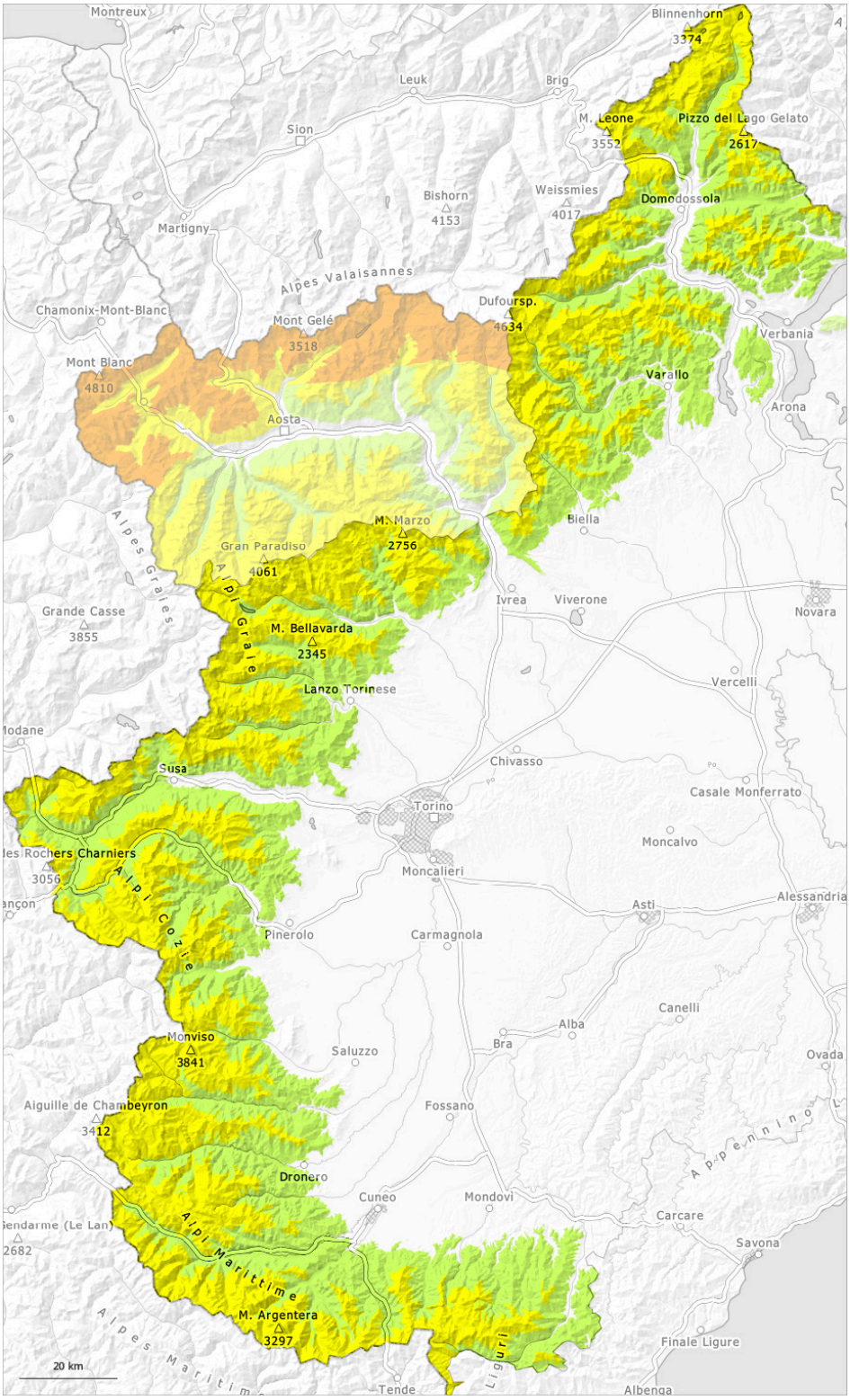

1	2	3	4	5
gering	mäßig	erheblich	groß	sehr groß

Gefahrenstufe 2 - Mäßig

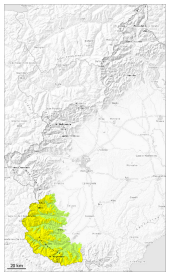

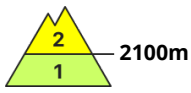

Tendenz: Lawinengefahr bleibt gleich
am Mittwoch, den 01.04.2026

Triebschnee

2100m

Die Triebschneeansammlungen sind gut erkennbar und vor allem mit großer Belastung auslösbar.

Die Schneedecke ist in tiefen und mittleren Lagen gut verfestigt.

Mit Neuschnee und mäßigem bis starkem Wind aus östlichen Richtungen entstanden in den letzten zwei Tagen vor allem in Rinnen, Mulden und hinter Geländekanten gut sichtbare Triebschneeansammlungen. Diese können vereinzelt von einzelnen Wintersportlern ausgelöst werden.
Die Lawinen können teilweise in den verschiedenen Triebschneeschichten anreißen und mittlere Größe erreichen.

Schneedecke

Gefahrenmuster gm.6: lockerer schnee und wind

Am Sonntag fielen gebietsweise oberhalb von rund 1800 m 10 cm Schnee.
Mit mäßigem bis starkem Wind entstanden in den letzten Tagen vor allem kammfern gut sichtbare Triebschneeansammlungen.

Besonders Hänge hohe Lagen und Hochgebirge: Im mittleren Teil der Schneedecke sind einzelne Schwachschichten vorhanden.

Vor allem Sonnenhänge tiefe und mittlere Lagen: Die Schneeoberfläche gefriert tragfähig und weicht später auf als am Vortag.

Gefahrenstufe 2 - Mäßig

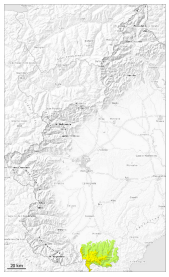

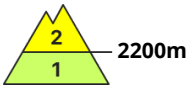

Tendenz: Lawinengefahr bleibt gleich
am Mittwoch, den 01.04.2026

Triebschnee

2200m

Die Gefahrenstellen liegen vor allem an steilen Schattenhängen in hohen Lagen und im Hochgebirge.

Die frischen und schon etwas älteren Triebschneeansammlungen können in hohen Lagen und im Hochgebirge teilweise von einzelnen Wintersportlern ausgelöst werden, besonders in ihren Randbereichen.
Die Gefahrenstellen liegen vor allem an Übergängen in Rinnen und Mulden sowie an steilen Schattenhängen oberhalb von rund 2200 m.
Lawinen können vereinzelt in tiefe Schichten durchreißen und mittlere Größe erreichen.

Schneedecke

Gefahrenmuster gm.6: lockerer schnee und wind

Der Triebschnee liegt verbreitet auf einer harten Kruste.
V.a. in Kammlagen in hohen Lagen liegen je nach Windeinfluss sehr unterschiedliche Schneehöhen.

An sonnigeren Hängen, wo die Temperaturen weniger kalt sind, wird die harte Oberfläche der Schneedecke im Tagesverlauf langsam weicher.

Gefahrenstufe 2 - Mäßig

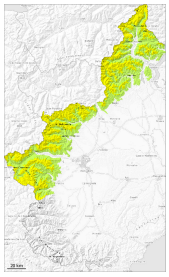

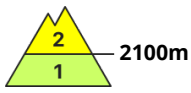

Tendenz: Lawinengefahr bleibt gleich
am Mittwoch, den 01.04.2026

Triebschnee

2100m

Die Gefahrenstellen liegen an Triebschneehängen in der Höhe.

Seit Sonntag fiel gebietsweise etwas Schnee. Mit mäßiger bis starker Bise entstanden in den letzten Tagen gut sichtbare Triebschneeansammlungen.

Heute bläst der Wind zeitweise stark. Mit zunehmendem Nordwestwind entstehen im Tagesverlauf vor allem kammfern meist dünne Triebschneeansammlungen. In Kammlagen in hohen Lagen liegen je nach Windeinfluss sehr unterschiedliche Schneehöhen.

Triebschneeansammlungen können stellenweise mit geringer Belastung ausgelöst werden und mittlere Größe erreichen. Dies besonders an eher schneearmen Stellen und in Rinnen, Mulden und hinter Geländekanten in mittleren und hohen Lagen.

Schneedecke

Gefahrenmuster gm.6: lockerer schnee und wind

Seit Sonntag fielen gebietsweise oberhalb von rund 1700 m 5 bis 10 cm Schnee.
Hohe Lagen und Hochgebirge: In Gipfellagen liegt kaum Schnee.
Unterhalb der vom Wind erodierten Gipfel, oberhalb von etwa 1600 m, liegt mehr Schnee als im saisonalen Durchschnitt.

Verschiedene Triebschneeschichten liegen verbreitet auf einer harten Kruste.
Besonders West-, Nord- und Osthänge hohe Lagen und Hochgebirge: In der Schneedecke sind einzelne Schwachschichten vorhanden.

Vor allem Sonnenhänge tiefe und mittlere Lagen: Die Schneeoberfläche weicht später auf als am Vortag.