Dienstag 31.03.2026

Aktualisiert am 30.03.2026 um 20:03

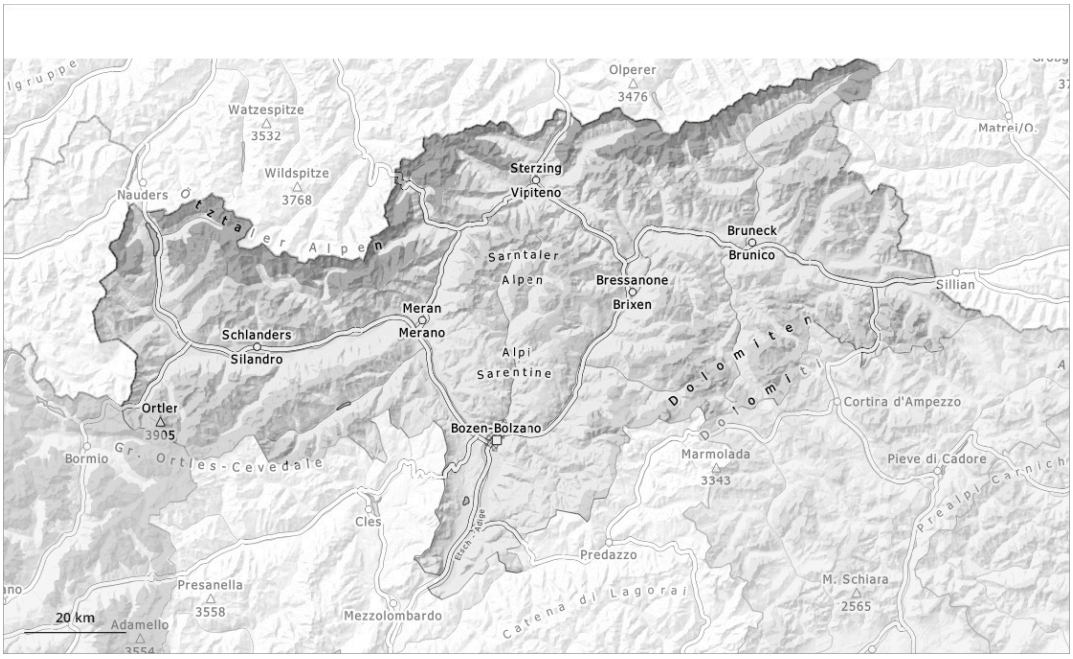

1	2	3	4	5
gering	mäßig	erheblich	groß	sehr groß

Gefahrenstufe 3 - Erheblich

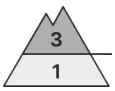

Waldgrenze

Tendenz: Lawinengefahr bleibt gleich
am Mittwoch, den 01.04.2026

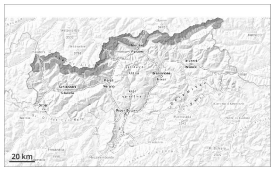

Triebschnee

Waldgrenze

Altschnee

2200m

Triebschnee ist die Hauptgefahr. Schwachen Altschnee vorsichtig beurteilen.

Mit Neuschnee und starkem bis stürmischem Wind entstehen an allen Expositionen umfangreiche Triebschneeansammlungen. Diese können oberhalb von rund 2200 m leicht ausgelöst werden oder vereinzelt spontan abgleiten. Vorsicht vor allem an Felswandfüßen und hinter Geländekanten sowie in Kammlagen, Rinnen und Mulden. Lawinen sind meist mittelgroß.

Zudem können vereinzelt Lawinen in bodennahe Schichten der Schneedecke durchreißen und vereinzelt groß werden, besonders an West-, Nord- und Osthängen oberhalb von rund 2200 m und an Südhängen in der Höhe.

Risse beim Betreten der Schneedecke können auf die Gefahr hinweisen.

Schneedecke

Gefahrenmuster gm.6: lockerer schnee und wind | gm.1: bodennahe schwachschicht

Es fallen 10 bis 30 cm Schnee, lokal auch mehr. Der teilweise stürmische Wind verfrachtet den Neuschnee intensiv. Die verschiedenen Triebschneeansammlungen sind teilweise schlecht miteinander verbunden.

Die Altschneedecke ist stellenweise schwach, besonders an West-, Nord- und Osthängen oberhalb von rund 2200 m und an Südhängen in der Höhe.

Tendenz

Die Lawinengefahr bleibt bestehen. Triebschnee und schwacher Altschnee sind die Hauptgefahr.

Gefahrenstufe 2 - Mäßig

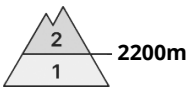

Tendenz: Lawinengefahr bleibt gleich
am Mittwoch, den 01.04.2026

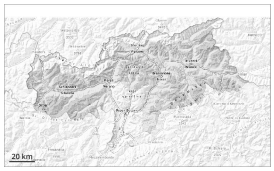

Triebschnee

Altschnee

Triebschnee ist die Hauptgefahr. Schwachen Altschnee beachten.

Mit Neuschnee und stürmischem Nordwind entstanden an allen Expositionen umfangreiche Triebschneeansammlungen. Diese können oberhalb von rund 2200 m schon von einzelnen Wintersportlern ausgelöst werden. Vorsicht vor allem an Felswandfüßen und hinter Geländekanten sowie in Kammlagen, Rinnen und Mulden. Lawinen sind meist mittelgroß.

Zudem können vereinzelt Lawinen in bodennahe Schichten der Schneedecke durchreißen und vereinzelt groß werden, besonders an West-, Nord- und Osthängen oberhalb von rund 2200 m und an Südhängen in der Höhe.

Risse beim Betreten der Schneedecke können auf die Gefahr hinweisen.

Schneedecke

Gefahrenmuster gm.6: lockerer schnee und wind | gm.1: bodennahe schwachschicht

Es fällt gebietsweise etwas Schnee. Der teilweise stürmische Wind verfrachtet Neu- und Altschnee. Die verschiedenen Triebschneeansammlungen sind teilweise noch schlecht miteinander verbunden.

Die Altschneedecke ist stellenweise schwach, besonders an West-, Nord- und Osthängen oberhalb von rund 2200 m und an Südhängen in der Höhe.

Tendenz

Mit teils starkem Wind aus nördlichen Richtungen entstehen weitere Triebschneeansammlungen. Triebschnee und schwachen Altschnee beachten.

Gefahrenstufe 1 - Gering

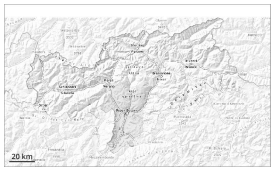

Tendenz: Lawinengefahr nimmt ab
am Mittwoch, den 01.04.2026

Triebschnee

Waldgrenze

Frischen Triebschnee vorsichtig beurteilen.

Triebschneeansammlungen sind vor allem an den Expositionen West über Nord bis Ost oberhalb der Waldgrenze teils störanfällig. Lawinen können sehr vereinzelt in bodennahe Schichten der Schneedecke durchreißen vereinzelt mittlere Größe erreichen.

Schneedecke

Gefahrenmuster gm.6: lockerer schnee und wind | gm.1: bodennahe schwachschicht

Der Wind bläst teils stürmisch. Der Wind verfrachtet den Schnee. Es entstanden störanfällige Triebschneeansammlungen.

Tendenz

Frischen Triebschnee vorsichtig beurteilen.