ICGC Institut Cartogràfic i Geològic de Catalunya

Servei Meteorològic de Catalunya meteo.cat

Boletín de peligro de aludes para el Pirineo de Catalunya
Del 30/03/2026 al 31/03/2026

(Válido fuera pistas de esquí y zonas no controladas)

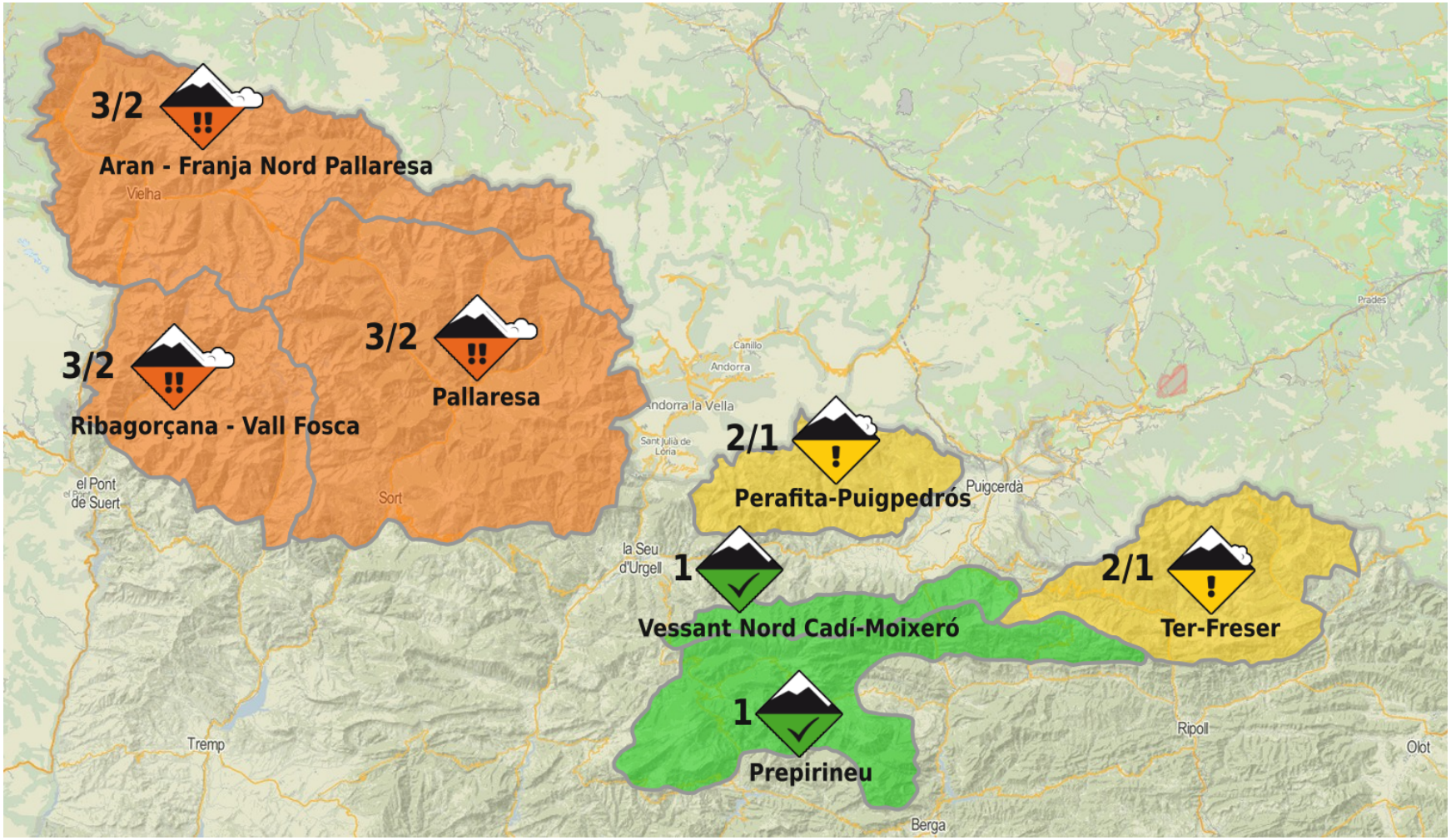

5 MUY FUERTE	4 FUERTE	3 NOTABLE	2 LIMITADO	1 DÉBIL

ICGC Institut Cartogràfic i Geològic de Catalunya

Servei Meteorològic de Catalunya

Boletín de peligro de aludes Aran - Franja Nord Pallaresa Del 30/03/2026 al 31/03/2026

(Válido fuera pistas de esquí y zonas no controladas)

NOTABLE (3) por encima de unos 2.000 m, LIMITADO (2) por debajo

Situación primaria

Nieve venteada

Distribución

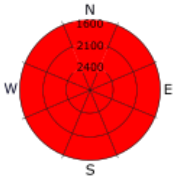

Tamaño

Origen

Tendencia

Situación secundaria

Nieve reciente

Distribución

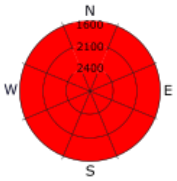

Tamaño

Origen

Tendencia

Estado del manto nivoso

Con la subida de temperatura y posibles lluvias, el lunes son probables purgas de nieve húmeda y caída de bolas por debajo de unos 2000 m.

A partir del lunes tarde, las nuevas nevadas con viento fuerte de N, formarán nuevas placas, pequeñas, o aumentarán las previas existentes. Las encontraremos en cualquier cota y orientación, más frecuentes y probables en S y E, de distribución irregular, en sectores más resguardados del viento intenso, y serán reactivas, de fácil desencadenamiento de forma accidental, generando aludes de tamaño medio en general.

Con las nuevas nevadas podrá haber actividad de aludes de nieve reciente, más probables en cotas medias y altas de cualquier orientación no afectada por el viento, y en vertientes de fuerte pendiente. Los aludes serían de pequeño tamaño, puntualmente medio.

Todavía existen niveles débiles internos en umbrías altas que pueden provocar rotura de placas por sobrecarga fuerte generando aludes de tamaño medio, o puntualmente grande.

Distribución del manto nivoso

Los espesores a unos 2.200 m son ligeramente superiores a los normales en la Franja Nord de la Pallaresa y en la mitad sur de Arán, donde rondan los 180-240 cm. En la mitad norte de Arán son los normales por estas fechas con unos 130-150 cm de espesor total.

Tendencia para las próximas 48-72h

Las precipitaciones previstas a partir del miércoles con viento fuerte inestabilizarán el manto, con la formación de nuevas placas. Peligro: en AUMENTO.

El próximo boletín será emitido el día 2026-03-31

5 MUY FUERTE	4 FUERTE	3 NOTABLE	2 LIMITADO	1 DÉBIL

EAWS EUROPEAN AVALANCHE WARNING SERVICES

ICGC Institut Cartogràfic i Geològic de Catalunya

Servei Meteorològic de Catalunya

Boletín de peligro de aludes Ribagorçana - Vall Fosca Del 30/03/2026 al 31/03/2026

(Válido fuera pistas de esquí y zonas no controladas)

NOTABLE (3) en el extremo norte, LIMITADO (2) en el resto

Situación primaria

Nieve venteada

Distribución

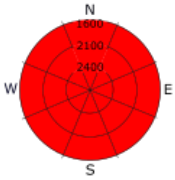

Tamaño

Origen

Tendencia

Situación secundaria

Capas débiles persistentes

Distribución

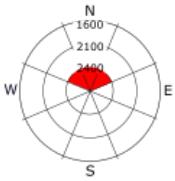

Tamaño

Origen

Tendencia

Estado del manto nivoso

El lunes por la tarde, con el aumento térmico y probables precipitaciones de lluvia hasta unos 1.800 m, puede producirse aludes de nieve húmeda, de pequeño tamaño, y caída de bolas, por debajo de unos 2.000 m.
El viento se irá fortaleciendo a partir del lunes tarde, de N, y se esperan nuevas precipitaciones débiles. Se podrán formar nuevas y pequeñas placas de viento o engrosar las existentes, sobre todo en el límite N del sector. Las placas se podrán localizar en todas orientaciones, más frecuentes en S y E y más probables por encima del límite de bosque, bajo collados y cordales, canales y laderas resguardadas, así como claros de bosque. Se mostrarán reactivas, fácilmente desencadenables al paso de una persona, y podrán provocar aludes de hasta tamaño medio.
En el límite N, a umbrías altas, todavía se puede encontrar niveles débiles internos que por sobrecarga fuerte, aunque poco probable, puedan provocar alguna rotura, generando aludes de tamaño medio en general.

Distribución del manto nivoso

Los grosores alcanzan los 100-120 cm a unos 2.200 m. Estos valores se acercan a los normales para la época.

Tendencia para las próximas 48-72h

Las precipitaciones previstas a partir del miércoles con viento fuerte inestabilizarán el manto, con la formación de nuevas placas. Peligro: en AUMENTO.

El próximo boletín será emitido el día 2026-03-31

5 MUY FUERTE	4 FUERTE	3 NOTABLE	2 LIMITADO	1 DÉBIL

EAWS EUROPEAN AVALANCHE WARNING SERVICES

ICGC Institut Cartogràfic i Geològic de Catalunya

Servei Meteorològic de Catalunya

Boletín de peligro de aludes Pallaresa
Del 30/03/2026 al 31/03/2026

(Válido fuera pistas de esquí y zonas no controladas)

NOTABLE (3) en el extremo norte, LIMITADO (2) en el resto

Situación primaria

Nieve venteada

Distribución

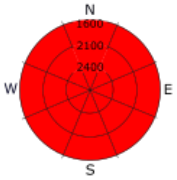

Tamaño

Origen

Tendencia

Situación secundaria

Capas débiles persistentes

Distribución

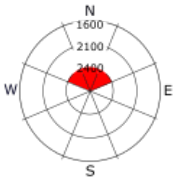

Tamaño

Origen

Tendencia

Estado del manto nivoso

El lunes por la tarde, con el aumento térmico y probables precipitaciones de lluvia hasta unos 1.800 m, puede producirse aludes de nieve húmeda, de pequeño tamaño, y caída de bolas, por debajo de unos 2.000 m.
El viento se irá fortaleciendo a partir del lunes tarde, de N, y se esperan nuevas precipitaciones débiles. Se podrán formar nuevas y pequeñas placas de viento o engrosar las existentes, sobre todo en el límite N del sector. Las placas se podrán localizar en todas orientaciones, más frecuentes en S y E y más probables por encima del límite de bosque, bajo collados y cordales, canales y laderas resguardadas, así como claros de bosque. Se mostrarán reactivas, fácilmente desencadenables al paso de una persona, y podrán provocar aludes de hasta tamaño medio.
En el límite N, a umbrías altas, todavía se puede encontrar niveles débiles internos que por sobrecarga fuerte, aunque poco probable, puedan provocar alguna rotura, generando aludes de tamaño medio en general.

Distribución del manto nivoso

Los espesores alcanzan los 110-150 cm en cotas medias, puntualmente más, variable según los efectos del viento.

Tendencia para las próximas 48-72h

Las precipitaciones previstas a partir del miércoles con viento fuerte inestabilizarán el manto, con la formación de nuevas placas. Peligro: en AUMENTO.

El próximo boletín será emitido el día 2026-03-31

5 MUY FUERTE	4 FUERTE	3 NOTABLE	2 LIMITADO	1 DÉBIL

EAWS EUROPEAN AVALANCHE WARNING SERVICES

ICGC Institut Cartogràfic i Geològic de Catalunya

meteo.cat Servei Meteorològic de Catalunya

Boletín de peligro de aludes Perafita-Puigpedrós Del 30/03/2026 al 31/03/2026

(Válido fuera pistas de esquí y zonas no controladas)

LIMITADO (2) por encima del límite de bosque, DÉBIL (1) por debajo

Situación primaria

Nieve venteada

Distribución

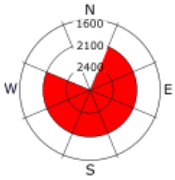

Tamaño

Origen

Tendencia

Estado del manto nivoso

El lunes por la tarde, con el aumento térmico y probables precipitaciones de lluvia hasta unos 1.800 m, puede producirse fusión de la nieve reciente y generar aludes de nieve húmeda, de pequeño tamaño, y caída de bolas, por debajo de unos 2.000 m.

El martes se prevén nuevas precipitaciones y continuación del viento fuerte de N, que podrá formar nuevas placas o engrosar las previas existentes. Las placas se podrán mostrar reactivas y podrán desencadenarse con facilidad al paso de una persona, incluso, localmente de forma natural, generando aludes de pequeño tamaño, o hasta tamaño medio, allí donde las sobreacumulaciones hayan sido más importantes. Se localizarán sobre todo en orientaciones S y E, menos frecuentes en el resto, por encima del límite de bosque y bajo collados y crestas o vertientes de acumulación de nieve venteada más resguardadas.

Distribución del manto nivoso

Hay nieve por encima de unos 1.900 m, discontinua hasta 2.200 m en solanas. Es esquiable a partir de unos 2.000 m en N. Los espesores, aunque irregulares, rondan los 70-100 cm en umbrías, a 2.300 m. Son grosores por encima de los habituales en esta época.

Tendencia para las próximas 48-72h

Las precipitaciones previstas a partir del miércoles con viento fuerte inestabilizarán el manto, con la formación de nuevas placas. Peligro: en AUMENTO.

El próximo boletín será emitido el día 2026-03-31

5 MUY FUERTE	4 FUERTE	3 NOTABLE	2 LIMITADO	1 DÉBIL

EAWS EUROPEAN AVALANCHE WARNING SERVICES

ICGC Institut Cartogràfic i Geològic de Catalunya

Servei Meteorològic de Catalunya

Boletín de peligro de aludes
Vessant Nord Cadí-Moixeró
Del 30/03/2026 al 31/03/2026

(Válido fuera pistas de esquí y zonas no controladas)

DÉBIL (1)

Situación primaria

Nieve venteada

Distribución

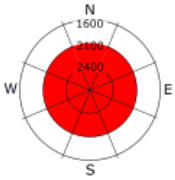

Tamaño

Origen

Tendencia

Estado del manto nivoso

A pesar del fuerte viento de N de las últimas jornadas, más intenso en el sector del Moixeró que en el Cadí, con precipitaciones muy escasas, el transporte de nieve ha estado limitado por la poca disponibilidad de nieve movilizable. El manto se encontrará en gran parte endurecido superficialmente.

El problema principal siguen siendo las placas de viento, generalmente locales y pequeñas, en las laderas resguardadas, preferentemente por encima del límite de bosque, bajo collados y cordales no venteados y dentro de las canales resguardadas, donde haya predominado la acumulación. Estas placas podrán estar presentes en cualquier orientación pero más probables en S y E. Pueden ser reactivas, fácilmente desencadenables al paso de una persona, muy puntualmente de forma natural, sobre todo en vertientes más inclinadas, y provocar aludes que serían de pequeño tamaño generalmente.

Distribución del manto nivoso

En umbrías hay presencia discontinua de nieve por encima de unos 1.700 m y es esquiable por encima de unos 1.900 m. Los grosores están alrededor de 160-180 cm a 2.200 m. Estos valores son muy excedentarios para la época del año.

Tendencia para las próximas 48-72h

Las precipitaciones previstas a partir del miércoles con viento fuerte inestabilizarán el manto, con la formación de nuevas placas. Peligro: en AUMENTO.

El próximo boletín será emitido el día 2026-03-31

5 MUY FUERTE	4 FUERTE	3 NOTABLE	2 LIMITADO	1 DÉBIL

EAWS EUROPEAN AVALANCHE WARNING SERVICES

ICGC Institut Cartogràfic i Geològic de Catalunya

Servei Meteorològic de Catalunya

Boletín de peligro de aludes Prepirineu
Del 30/03/2026 al 31/03/2026

(Válido fuera pistas de esquí y zonas no controladas)

DÉBIL (1)

Situación primaria

Nieve venteada

Distribución

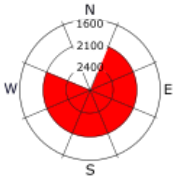

Tamaño

Origen

Tendencia

Estado del manto nivoso

A pesar del fuerte viento de N de las últimas jornadas con precipitaciones muy escasas, el transporte de nieve ha sido limitado por la poca disponibilidad de nieve movilizable.

El manto por lo general se encuentra bastante asentado y estable. El problema principal siguen siendo las posibles placas de viento, locales, donde no exista la presencia de costra superficial. Estas placas se pueden encontrar sobre todo en orientaciones S y E, menos frecuentes en el resto, por encima del límite de bosque y bajo collados y crestas, o vertientes de acumulación de nieve venteada más resguardadas del viento. Por lo general la presencia de placas es muy local pero se pueden mostrar sensibles y reactivas al paso de una persona, generando aludes de pequeño tamaño en general.

Distribución del manto nivoso

En umbrías hay nieve por encima de unos 1.700 m. En solanas la nieve está presente por encima de unos 1.900 m, discontinua. Los espesores, aunque irregulares, rondan los 90-120 cm a 2.300 m.

Tendencia para las próximas 48-72h

Las precipitaciones previstas a partir del miércoles con viento fuerte inestabilizarán el manto, con la formación de nuevas placas. Peligro: en AUMENTO.

El próximo boletín será emitido el día 2026-03-31

5 MUY FUERTE	4 FUERTE	3 NOTABLE	2 LIMITADO	1 DÉBIL

EAWS EUROPEAN AVALANCHE WARNING SERVICES

ICGC Institut Cartogràfic i Geològic de Catalunya

Servei Meteorològic de Catalunya meteo.cat

Boletín de peligro de aludes Ter-Freser
Del 30/03/2026 al 31/03/2026

(Válido fuera pistas de esquí y zonas no controladas)

LIMITADO (2) por encima del límite de bosque, DÉBIL (1) por debajo

Situación primaria

Nieve venteada

Distribución

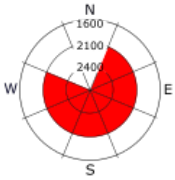

Tamaño

Origen

Tendencia

Estado del manto nivoso

El viento ha continuado siendo fuerte con transporte efectivo y continuará así en las próximas jornadas. El lunes, los escasos lugares resguardados del viento donde se haya podido depositar la nieve reciente, podrá purgarse con el aumento térmico y radiación, con posibilidad de pequeños aludes de nieve reciente húmeda o caída de bolas en laderas inclinadas.

Para el martes el problema será básicamente el de placa de viento. Las placas recién formadas y las que se puedan formar de nuevo con el viento de N se mostrarán reactivas. Podrán desencadenarse con facilidad al paso de una persona generando aludes de pequeño tamaño, o hasta tamaño medio localmente, allá donde las sobreacumulaciones hayan sido más importantes. Se localizarán sobre todo en orientaciones S y E, menos frecuentes en el resto, por encima del límite de bosque y bajo collados y crestas o vertientes de acumulación de nieve venteada más resguardadas.

Distribución del manto nivoso

Hay nieve en el suelo por encima de unos 1.700 m. El manto es esquiable en umbrías a partir de unos 1.800 m. Los grosores son muy excedentarios para la época del año y en lugares no afectados por el viento oscilan entre 60-80 cm a unos 2.000 m, y más de 150 cm por encima de 2.400 m, muy variable por los efectos del viento.

Tendencia para las próximas 48-72h

Las precipitaciones previstas a partir del miércoles con viento fuerte inestabilizarán el manto, con la formación de nuevas placas. Peligro: en AUMENTO.

El próximo boletín será emitido el día 2026-03-31

5 MUY FUERTE	4 FUERTE	3 NOTABLE	2 LIMITADO	1 DÉBIL

EAWS EUROPEAN AVALANCHE WARNING SERVICES