BUTLLETÍ DEL PERILL D'ALLAUS DEL PRINCIPAT D'ANDORRA

Elaborado el 30/03/2026 16:00
Proxima actualización 31/03/2026 a las 16h

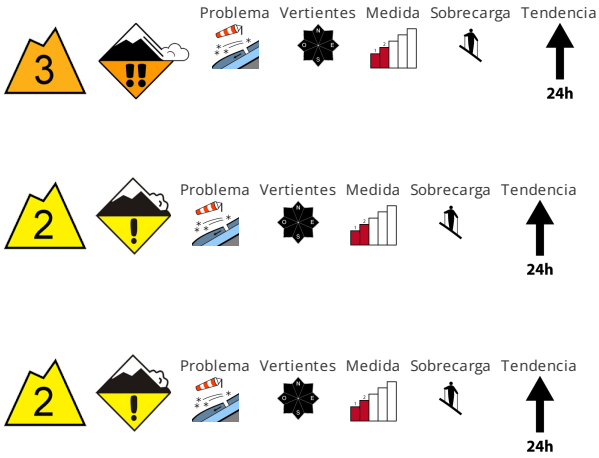

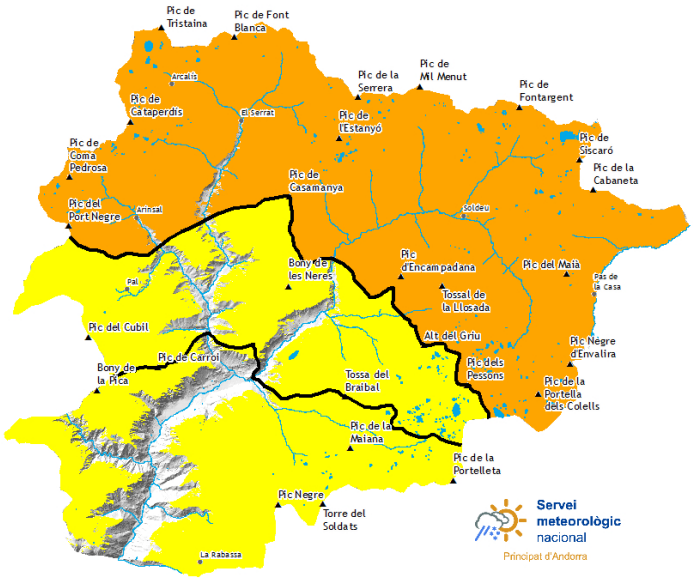

CALIDAD DE LA NIEVE

Las zonas de salida se han visto nuevamente cargadas a causa de la nevada y el viento. El viento con rachas fuertes transportará intensamente la nieve reciente y la nieve antigua. Las condiciones para las excursiones son en algunos casos desfavorables. Esto se da principalmente en zonas de salida situadas a cota alta y por encima del límite del bosque. Los lugares peligrosos se encuentran en todas las orientaciones cerca del límite del bosque y en la entrada de canales y cubetas. Las placas de viento pueden ser desencadenadas fácilmente y alcanzar un tamaño mediano. Los lugares peligrosos son bastante frecuentes y resultan difíciles de reconocer con poca visibilidad.

ESTABILIDAD DEL MANTO NIVOSO

Sobre todo en el norte domingo se han acumulado 30 cm de nieve por encima de los 2000 m aproximadamente. El manto de nieve permanece extremadamente variable en pocos metros en general. Cerca de los cordales los espesores de nieve varían mucho por la influencia del viento. Hasta el jueves el viento soplará, cerca de los cordales, fuerte. El miércoles caerá mucha nieve sobre todo en los norte.

ESPESORES DEL MANTO NIVOSO FUERA DE PISTA

Zona norte		Espesor nieve		
Manto Nival		1500m	2000m	2500m
N	1300 m	10 cm	150 cm	200 cm
S	1500 m	5 cm	100 cm	150 cm

zona centro		Espesor nieve		
Manto Nival		1500m	2000m	2500m
N	1300 m	10 cm	150 cm	200 cm
S	1500 m	5 cm	100 cm	150 cm

Zona sur		Espesor nieve		
Manto Nival		1500m	2000m	2500m
N	1300 m	10 cm	120 cm	150 cm
S	1500 m	5 cm	60 cm	100 cm

Govern d'Andorra

EAWS EUROPEAN AVALANCHE WARNING SERVICES

Aquest butlletí ha estat elaborat seguint les normes i recomanacions de l'**European Avalanche Warning Services**, del qual el **Servei meteorològic Nacional** n'és membre

BUTLLETÍ DEL PERILL D'ALLAUS DEL PRINCIPAT D'ANDORRA

Servei meteorològic nacional
Principat d'Andorra

Información detallada por espacios naturales protegidos

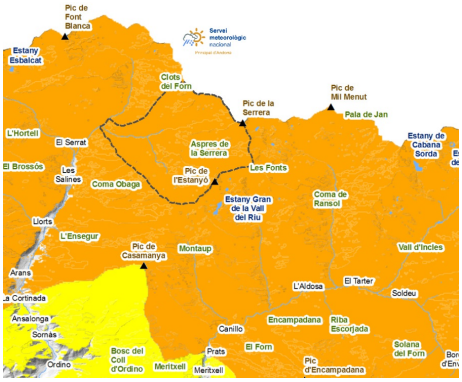

SORTENY

El viento ha moldeado la nieve reciente y lo seguirá haciendo durante las próximas horas, por tanto las placas de viento estarán en constante evolución. Debido al viento que todavía soplará fuerte en altura durante esta primera mitad de Semana Santa y de las sucesivas nevadas que sobre todo afectarán al norte de Andorra, no es recomendable salir del terreno simple ni aventurarnos a ir más allá del límite del bosque.

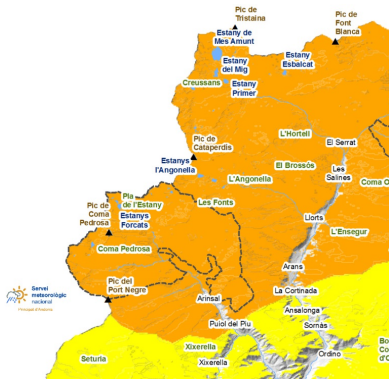

COMAPEDROSA

Se prevé que el viento sea aún intenso en altura durante los próximos días y se sigan formando placas de viento. La situación no resulta muy favorable para las excursiones.

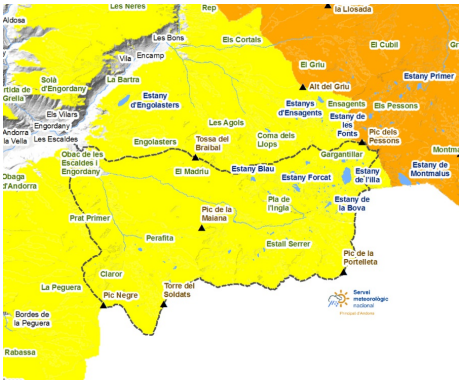

MADRIU-PERAFITA-CLAROR

La nieve reciente retrocede rápidamente de las cotas bajas del valle, pero en cotas altas el ambiente es aún invernal. El viento y la mala visibilidad deben hacernos renunciar a llegar a los collados más altos. Sin embargo, también podemos encontrar placas de viento en el límite del bosque. Deberemos circular con precaución, mantener la distancia de seguridad y circular el máximo tiempo posible por la corteza de nieve dura y rehelada, allí donde el viento haya barrido la nieve nueva.

Govern d'Andorra

EAWS
EUROPEAN AVALANCHE WARNING SERVICES

Aquest butlletí ha estat elaborat seguint les normes i recomanacions de l'**European Avalanche Warning Services**, del qual el **Servei meteorològic Nacional** n'és membre

BUTLLETÍ DEL PERILL D'ALLAUS DEL PRINCIPAT D'ANDORRA

Servei meteorològic nacional
Principat d'Andorra

Espesores de nieve nueva de los últimos días (de las ultimas 24h mesurado a las 06:00h UTC)

	26/03/2026	27/03/2026	28/03/2026	29/03/2026
FEDA (Central)	0 cm	0 cm	0 cm	0 cm
Engolasters - FEDA	0 cm	0 cm	7 cm	0 cm
Bony de les Neres	0 cm	0 cm	20 cm	0 cm
Les Fonts d'Arinsal	0 cm	0 cm	4 cm	0 cm
Perafita	0 cm	0 cm	0 cm	0 cm
Tossa Espiolets	0 cm	0 cm	34 cm	0 cm
Grau Roig - FEDA	0 cm	0 cm	16 cm	0 cm
Fontverd	0 cm	0 cm	17 cm	0 cm
Coll Ordino	0 cm	0 cm	25 cm	0 cm
Ransol - FEDA	0 cm	0 cm	18 cm	0 cm
Setúria	0 cm	0 cm	21 cm	0 cm
Caborreu	0 cm	0 cm	23 cm	0 cm
La Solana	1 cm	1 cm	30 cm	9 cm
Coll Pa	0 cm	6 cm	21 cm	0 cm
Envalira Antenes	0 cm	0 cm	27 cm	11 cm
Vall del Riu FEDA	0 cm	0 cm	10 cm	0 cm