BUTLLETÍ DEL PERILL D'ALLAUS DEL PRINCIPAT D'ANDORRA

Préparé le 30/03/2026 16:00
Prochaine mise à jour le 31/03/2026 à 16h

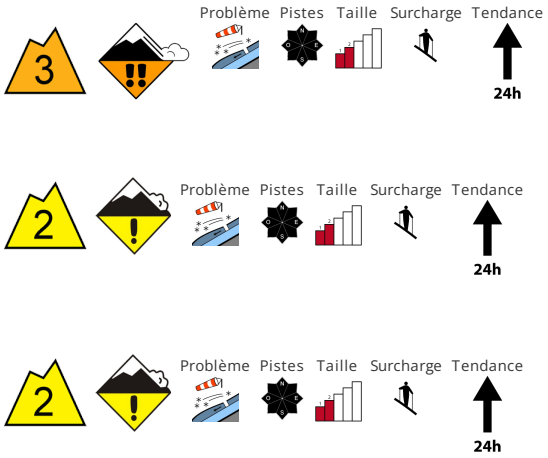

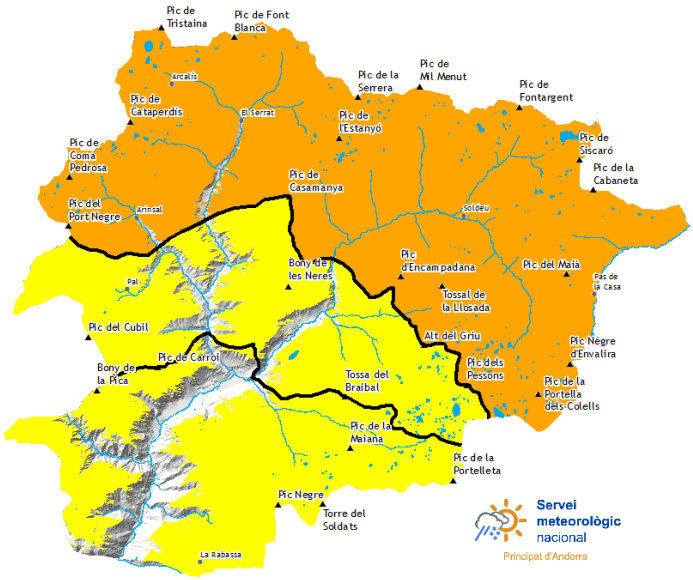

STABILITÉ DU MANTEAU NEIGEUX

Les zones de départ ont été à nouveau rechargées avec les chutes de neige et le vent. Le vent parfois fort transporte la neige fraîche et ancienne de manière intensive.. Les conditions de randonnées sont partiellement défavorables. Ceci particulièrement dans les zones de départ à haute altitude et au-dessus de la limite de la forêt. Les endroits dangereux se situent à toutes les expositions dans la zone de la limite de la forêt ainsi qu'aux transitions vers les combes et couloirs. Les accumulations de neige soufflée peuvent peut être déchaîné facilement et atteindre une taille moyenne.. Les endroits dangereux sont assez fréquents et à peine identifiables par mauvaise visibilité..

QUALITÈ DE LA NEIGE

Dimanche il est tombé surtout au nord au-dessus d'environ 2000 m 30 cm de neige. De manière généralisée le manteau neigeux reste très variable à petite échelle.. À proximité des crêtes on trouve suivant l'influence du vent des hauteurs de neiges très différentes. Jusqu'à jeudi le vent soufflera à proximité des crêtes fortement. Mercredi il tombera beaucoup de neige surtout au nord.

EPAISSEUR DE NEIGE HORS PISTE

Zone nord		Epaisseur de neige		
Nival manteau		1500m	2000m	2500m
N	1300 m	10 cm	150 cm	200 cm
S	1500 m	5 cm	100 cm	150 cm

Zone centre		Epaisseur de neige		
Nival manteau		1500m	2000m	2500m
N	1300 m	10 cm	150 cm	200 cm
S	1500 m	5 cm	100 cm	150 cm

Zone sud		Epaisseur de neige		
Nival manteau		1500m	2000m	2500m
N	1300 m	10 cm	120 cm	150 cm
S	1500 m	5 cm	60 cm	100 cm

Govern d'Andorra

EAWS EUROPEAN AVALANCHE WARNING SERVICES

Aquest butlletí ha estat elaborat seguint les normes i recomanacions de l'**European Avalanche Warning Services**, del qual el **Servei meteorològic Nacional** n'és membre

BUTLLETÍ DEL PERILL D'ALLAUS DEL PRINCIPAT D'ANDORRA

Servei meteorològic nacional
Principat d'Andorra

Des informations détaillées par espace naturel protégé

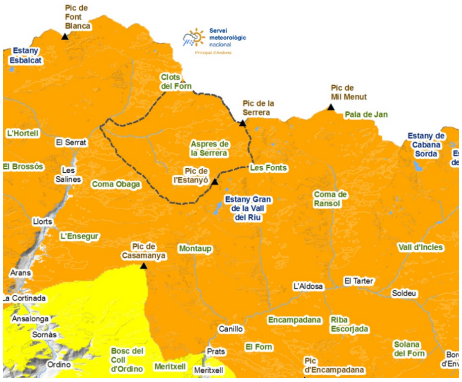

SORTENY

Le vent a façonné la neige récente et continuera de le faire au cours des prochaines heures, les zones de vent évolueront donc constamment. En raison du vent qui soufflera encore fort en altitude durant cette première moitié de la Semaine Sainte et des chutes de neige successives qui affecteront principalement le nord d'Andorre, il est déconseillé de quitter la plaine ou de s'aventurer au-delà de la lisière de la forêt. , , ,

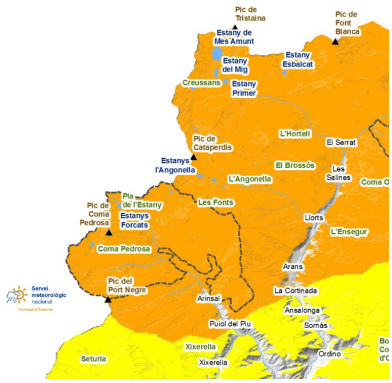

COMAPEDROSA

On s'attend à ce que le vent soit encore fort en altitude au cours des prochains jours et que des plaques de vent continuent de se former. La situation n'est pas très favorable aux excursions. , , ,

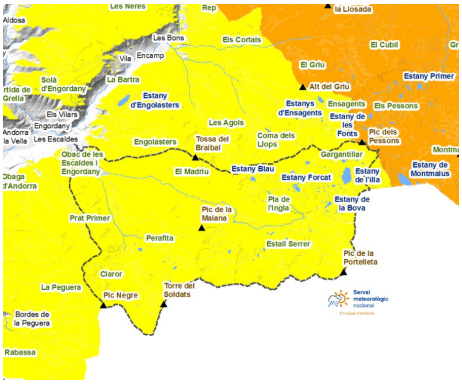

MADRIU-PERAFITA-CLAROR

La neige récente recule rapidement dans les basses altitudes de la vallée, mais à des altitudes plus élevées, l'atmosphère est encore hivernale. Le vent et la mauvaise visibilité nous feront renoncer à atteindre les plus hautes collines. Néanmoins, on peut également trouver des plaques à vent en lisière de forêt. Il faudra conduire avec prudence, garder une distance de sécurité et rouler le plus longtemps possible sur la croûte de neige dure et gelée, partout où le vent a balayé la neige fraîche. , , , , , , ,

Govern d'Andorra

EAWS
EUROPEAN AVALANCHE WARNING SERVICES

Aquest butlletí ha estat elaborat seguint les normes i recomanacions de l'**European Avalanche Warning Services**, del qual el **Servei meteorològic Nacional** n'és membre

BUTLLETÍ DEL PERILL D'ALLAUS DEL PRINCIPAT D'ANDORRA

Servei meteorològic nacional
Principat d'Andorra

Couche de neige fraiche des derniers jours (De 24 h mesurée à 06:00 h UTC)

	26/03/2026	27/03/2026	28/03/2026	29/03/2026
FEDA (Central)	0 cm	0 cm	0 cm	0 cm
Engolasters - FEDA	0 cm	0 cm	7 cm	0 cm
Bony de les Neres	0 cm	0 cm	20 cm	0 cm
Les Fonts d'Arinsal	0 cm	0 cm	4 cm	0 cm
Perafita	0 cm	0 cm	0 cm	0 cm
Tossa Espiolets	0 cm	0 cm	34 cm	0 cm
Grau Roig - FEDA	0 cm	0 cm	16 cm	0 cm
Fontverd	0 cm	0 cm	17 cm	0 cm
Coll Ordino	0 cm	0 cm	25 cm	0 cm
Ransol - FEDA	0 cm	0 cm	18 cm	0 cm
Setúria	0 cm	0 cm	21 cm	0 cm
Caborreu	0 cm	0 cm	23 cm	0 cm
La Solana	1 cm	1 cm	30 cm	9 cm
Coll Pa	0 cm	6 cm	21 cm	0 cm
Envalira Antenes	0 cm	0 cm	27 cm	11 cm
Vall del Riu FEDA	0 cm	0 cm	10 cm	0 cm