MINISTERO DELLA DIFESA

meteomont
Servizio Nazionale di previsione neve e valanghe

EAWS EUROPEAN AVALANCHE WARNING SERVICES

CARABINIERI

In collaborazione con: arpav

DOLOMITI SETTENTRIONALI

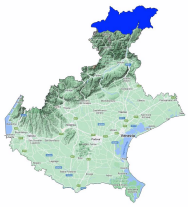

Bollettino Valanghe N. 389/2026 del 30/03/2026 ore 14.00
Validità 48 ore prossima emissione 31/03/2026
A cura del Servizio METEOMONT dell'ARMA dei CARABINIERI
In collaborazione con Servizio Meteorologico dell'Aeronautica militare

SITUAZIONE alle 14:00 del 30/03/2026

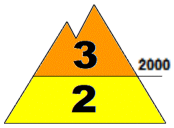

SITUAZIONE TIPO: neve a debole coesione e vento.

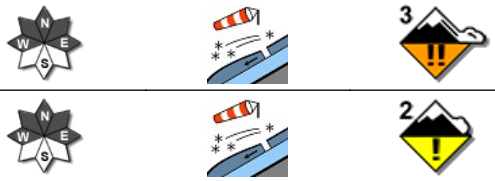

SITUAZIONE TIPO: neve a debole coesione e vento.

Quota neve (mslm)	Nord	Sud
	1200 - 1500	1500 - 1800

Altezza Neve (cm)	Neve al suolo	Neve Fresca	Quota (mslm)
	95	000	2100
	070	000	1500

VALANGHE OSSERVATE: Nessuna valanga.

PREVISIONI 31/03/2026

GRADO DI PERICOLO: MODERATO 2

SITUAZIONE TIPO: neve a debole coesione e vento.



MANTO NEVOSO: La stabilità del manto nevoso è scarsa su pochi punti (aree) per versanti da ovest a est, possibili valanghe di dimensioni grandi.

AVVERTENZE

In considerazione degli importanti accumuli di neve ventata in conche, canaloni, cambi di pendenza e pendii sotto vento in genere, è richiesta un'ottima valutazione locale della stabilità ed individuazione dell'itinerario.

SCALA EUROPEA DEL GRADO DI PERICOLO VALANGHE

LEGENDA PROBLEMA

Bollettino realizzato su scala sinottica-regionale (standard EAWS). La sua valutazione non può escludere in alcun modo la necessità di una seria e capace valutazione locale del pericolo (singolo pendio) che può essere anche sensibilmente diverso. Le previsioni meteorologiche sono relative all'orario UTC (per l'Italia +1 in inverno e +2 in estate).

MINISTERO DELLA DIFESA

meteomont
Servizio Nazionale di previsione neve e valanghe

EAWS EUROPEAN AVALANCHE WARNING SERVICES

CARABINIERI

In collaborazione con: arpav

DOLOMITI SETTENTRIONALI

PREVISIONE METEO

Quota		31/03/2026 h6:00	31/03/2026 h12:00	31/03/2026 h18:00
1000	Venti	04 Nodi da Nord	05 Nodi da Nord	04 Nodi da Nord
	Temperature	-07 °C	-04 °C	-06 °C
	Temp.percepita	-11 °C	-8 °C	-10 °C
2000	Venti	10 Nodi da Nord	14 Nodi da Nord	10 Nodi da Nord
	Temperature	-08 °C	-06 °C	-07 °C
	Temp.percepita	-15 °C	-14 °C	-14 °C
3000	Venti	22 Nodi da Nord	19 Nodi da N-Est	18 Nodi da N-Est
	Temperature	-15 °C	-14 °C	-13 °C
	Temp.percepita	-28 °C	-25 °C	-24 °C
Zero termico		0600-0800 m.	1200-1400 m.	0800-1000 m.
Fenomeno		—	—	—
Stato del cielo				

LEGENDA FENOMENI

— Assenza Fenomeni · Nebbia · Foschia · Pioggia debole · Pioggia moderata · Pioggia forte · Temporali

Nevicata debole · Nevicata moderata · Nevicata forte

STATO DEL CIELO

Sereno · Poco nuvoloso · Nuvoloso · Molto nuvoloso · Coperto

Parametri meteonivometrici registrati presso i campi di rilevamento il 30/03/2026.

Località	Comune	Quota (m.s.l.m.)	Altezza neve (cm)	Neve caduta nelle 24 ore (cm)	Temp. Min (°C)	Temp. Max (°C)	Condizioni del tempo
MISURINA	Auronzo di Cadore (BL)	1759	45	0	-7	+9	Assenza di precipitazioni
MONTE AGUDO	Auronzo di Cadore (BL)	1530	69	0	-5	+3	Assenza di precipitazioni
MONTE FALORIA	Cortina d'Ampezzo (BL)	2119	94	0	-8	+8	Assenza di precipitazioni
PASSO GIAU *	San Vito di Cadore (BL)	2275	62	0	N.P.	N.P.	Assenza di precipitazioni

(*) Rilievi fuori campo

L'INFORMAZIONE E' PREVENZIONE - LEGGI L'ATTUALE GRADO DI PERICOLO VALANGHE!

IL CAPO DEL CENTRO NAZIONALE METEOMONT
(Ten. Col. RFI Emanuela Gini)
FIRMA AUTOGRAFA OMESSA AI SENSI
DELL'ART.3 DEL D.LGS N.39/1993

Bollettino realizzato su scala sinottica-regionale (standard EAWS). La sua valutazione non può escludere in alcun modo la necessità di una seria e capace valutazione locale del pericolo (singolo pendio) che può essere anche sensibilmente diverso. Le previsioni meteorologiche sono relative all'orario UTC (per l'Italia +1 in inverno e +2 in estate).