MINISTERO DELLA DIFESA

meteomont
Servizio Nazionale di previsione neve e valanghe

EAWS EUROPEAN AVALANCHE WARNING SERVICES

CARABINIERI

ALPI RETICHE

Bollettino Valanghe N. 391/2026 del 30/03/2026 ore 14.00
Validità 48 ore prossima emissione 31/03/2026

A cura del Servizio METEOMONT dell'ARMA dei CARABINIERI
In collaborazione con Servizio Meteorologico dell'Aeronautica militare

SITUAZIONE alle 14:00 del 30/03/2026

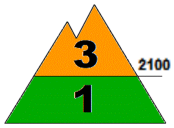

SITUAZIONE TIPO: neve a debole coesione e vento.



SITUAZIONE TIPO: passaggio da poca a molta neve.

Quota neve (mslm)	Nord	Sud
	1400 - 1800	2000 - 2400

Altezza Neve (cm)	Neve al suolo	Neve Fresca	Quota (mslm)
	68	0	2582
	55-65	0	2000

VALANGHE OSSERVATE: Nessuna valanga.

PREVISIONI 31/03/2026

GRADO DI PERICOLO: MARCATO 3

SITUAZIONE TIPO: neve a debole coesione e vento.

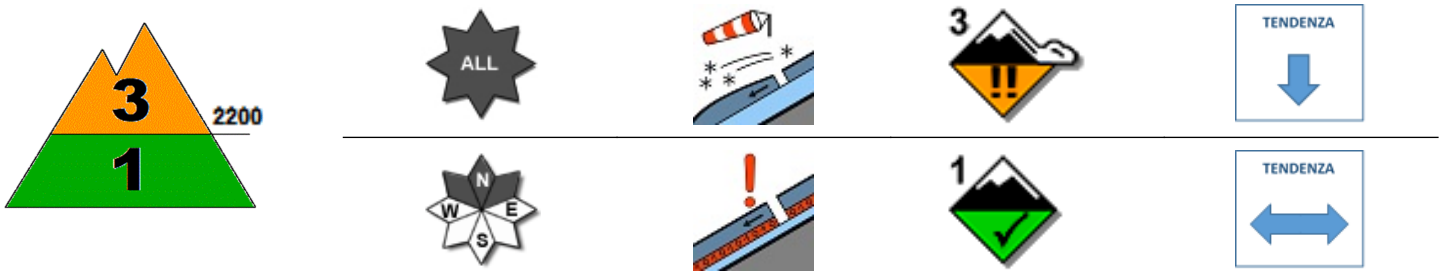

SITUAZIONE TIPO: passaggio da poca a molta neve.

MANTO NEVOSO: La stabilità del manto nevoso è scarsa su alcuni punti (aree) per tutte le esposizioni al di sopra di 2200 mslm, possibili valanghe di dimensioni grandi.
La stabilità del manto nevoso è discreta su pochissimi punti (aree) per versanti settentrionali al di sotto di 2200 mslm, possibili valanghe di dimensioni medie.

AVVERTENZE

A seguito dell'attività eolica registrata sono da evitare le zone di accumulo, conche, canaloni, cambi di pendenza e pendii sotto vento in genere.

SCALA EUROPEA DEL GRADO DI PERICOLO VALANGHE

LEGENDA PROBLEMA

Bollettino realizzato su scala sinottica-regionale (standard EAWS). La sua valutazione non può escludere in alcun modo la necessità di una seria e capace valutazione locale del pericolo (singolo pendio) che può essere anche sensibilmente diverso. Le previsioni meteorologiche sono relative all'orario UTC (per l'Italia +1 in inverno e +2 in estate).

MINISTERO DELLA DIFESA

meteomont
Servizio Nazionale di previsione neve e valanghe

EAWS EUROPEAN AVALANCHE WARNING SERVICES

CARABINIERI

ALPI RETICHE

PREVISIONE METEO

Quota		31/03/2026 h6:00	31/03/2026 h12:00	31/03/2026 h18:00
1000	Venti	03 Nodi da Nord	05 Nodi da Nord	07 Nodi da Nord
	Temperature	-08 °C	-06 °C	-07 °C
	Temp.percepita	-11 °C	-10 °C	-13 °C
2000	Venti	03 Nodi da Nord	05 Nodi da Nord	07 Nodi da Nord
	Temperature	-08 °C	-06 °C	-07 °C
	Temp.percepita	-11 °C	-10 °C	-13 °C
3000	Venti	20 Nodi da Nord	24 Nodi da Nord	27 Nodi da Nord
	Temperature	-15 °C	-15 °C	-13 °C
	Temp.percepita	-27 °C	-28 °C	-26 °C
Zero termico		0700-0900 m.	1000-1200 m.	0800-1000 m.
Fenomeno			—	—
Stato del cielo				

LEGENDA FENOMENI

— Assenza Fenomeni
Nebbia
Foschia
Pioggia debole
Pioggia moderata
Pioggia forte
Temporali
Nevicata debole
Nevicata moderata
Nevicata forte

STATO DEL CIELO

Sereno
Poco nuvoloso
Nuvoloso
Molto nuvoloso
Coperto

Parametri meteonivometrici registrati presso i campi di rilevamento il 30/03/2026.

Località	Comune	Quota (m.s.l.m.)	Altezza neve (cm)	Neve caduta nelle 24 ore (cm)	Temp. Min (°C)	Temp. Max (°C)	Condizioni del tempo
CUMANA- BORMIO 2000 *	Valdisotto (SO)	1968	55	0	N.P.	N.P.	Precipitazioni all'orizzonte (pioggia, neve, grandine, temporali) ma non sulla stazione
VALAR	Valdidentro (SO)	1930	65	0	N.P.	N.P.	Assenza di precipitazioni
DOSSO DEL VALLONE	Valfurva (SO)	2582	68	0	-12	-1	Assenza di precipitazioni
ALPE PALU'	Chiesa in Valmalenco (SO)	2010	62	0	-6	+6	Assenza di precipitazioni
PREDA	Edolo (BS)	1580	0	0	-6	+9	Assenza di precipitazioni
VEDRETTA DEL VENTINA *	Chiesa in Valmalenco (SO)	2747	120	0	N.P.	N.P.	Precipitazioni all'orizzonte (pioggia, neve, grandine, temporali) ma non sulla stazione

(*) Rilievi fuori campo

L'INFORMAZIONE E' PREVENZIONE - LEGGI L'ATTUALE GRADO DI PERICOLO VALANGHE!

IL CAPO DEL CENTRO NAZIONALE METEOMONT
(Ten. Col. RFI Emanuela Gini)
FIRMA AUTOGRAFA OMESSA AI SENSI
DELL'ART.3 DEL D.LGS N.39/1993

Bollettino realizzato su scala sinottica-regionale (standard EAWS). La sua valutazione non può escludere in alcun modo la necessità di una seria e capace valutazione locale del pericolo (singolo pendio) che può essere anche sensibilmente diverso. Le previsioni meteorologiche sono relative all'orario UTC (per l'Italia +1 in inverno e +2 in estate).