MINISTERO DELLA DIFESA

meteomont Servizio Nazionale di previsione neve e valanghe

EAWS EUROPEAN AVALANCHE WARNING SERVICES

CARABINIERI

# GRAN SASSO OVEST

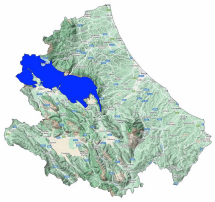

Bollettino Valanghe N. 379/2026 del 30/03/2026 ore 14.00
Validità 48 ore prossima emissione 31/03/2026

**A cura del Servizio METEOMONT dell'ARMA dei CARABINIERI**
**In collaborazione con Servizio Meteorologico dell'Aeronautica militare**

## SITUAZIONE alle 14:00 del 30/03/2026

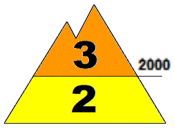


**SITUAZIONE TIPO: neve a debole coesione e vento.**




**SITUAZIONE TIPO: situazione primaverile.**

| Quota neve (mslm) | Nord | Sud |
|---|---|---|
| | 1000 - 1200 | 1200 - 1400 |

| Altezza Neve (cm) | Neve al suolo | Neve Fresca | Quota (mslm) |
|---|---|---|---|
| | 013 | 000 | 1384 |
| | 000 | 000 | 1400 |

**VALANGHE OSSERVATE: Nessuna valanga.**

## PREVISIONI 31/03/2026

# GRADO DI PERICOLO: MARCATO 3

## SITUAZIONE TIPO: neve a debole coesione e vento.

**MANTO NEVOSO: La stabilità del manto nevoso è scarsa su alcuni punti (aree) per tutte le esposizioni, possibili valanghe di dimensioni grandi.**

## AVVERTENZE

In considerazione delle avverse condizioni meteorologiche previste , le attività al di fuori delle piste battute e segnalate sono sconsigliate.

## SCALA EUROPEA DEL GRADO DI PERICOLO VALANGHE

## LEGENDA PROBLEMA

**Bollettino realizzato su scala sinottica-regionale (standard EAWS). La sua valutazione non può escludere in alcun modo la necessità di una seria e capace valutazione locale del pericolo (singolo pendio) che può essere anche sensibilmente diverso. Le previsioni meteorologiche sono relative all'orario UTC (per l'Italia +1 in inverno e +2 in estate).**

MINISTERO DELLA DIFESA

meteomont
Servizio Nazionale di previsione neve e valanghe

EAWS EUROPEAN AVALANCHE WARNING SERVICES

CARABINIERI

# GRAN SASSO OVEST

## PREVISIONE METEO

| Quota | | 31/03/2026 h6:00 | 31/03/2026 h12:00 | 31/03/2026 h18:00 |
|---|---|---|---|---|
| 1000 | Venti | 05 Nodi da N-Est | 07 Nodi da N-Est | 11 Nodi da N-Est |
| | Temperature | -02 °C | -01 °C | -02 °C |
| | Temp.percepita | -5 °C | -5 °C | -8 °C |
| 2000 | Venti | 17 Nodi da N-Est | 23 Nodi da N-Est | 32 Nodi da N-Est |
| | Temperature | -05 °C | -05 °C | -06 °C |
| | Temp.percepita | -13 °C | -14 °C | -17 °C |
| 3000 | Venti | 15 Nodi da N-Est | 20 Nodi da N-Est | 27 Nodi da N-Est |
| | Temperature | -10 °C | -09 °C | -08 °C |
| | Temp.percepita | -19 °C | -19 °C | -19 °C |
| Zero termico | | 1200-1400 m. | 1300-1500 m. | 1100-1300 m. |
| Fenomeno | | | | |
| Stato del cielo | | | | |

## LEGENDA FENOMENI

Assenza Fenomeni · Nebbia · Foschia · Pioggia debole · Pioggia moderata · Pioggia forte · Temporali

Nevicata debole · Nevicata moderata · Nevicata forte

## STATO DEL CIELO

Sereno · Poco nuvoloso · Nuvoloso · Molto nuvoloso · Coperto

## Parametri meteonivometrici registrati presso i campi di rilevamento il 30/03/2026.

| Località | Comune | Quota (m.s.l.m.) | Altezza neve (cm) | Neve caduta nelle 24 ore (cm) | Temp. Min (°C) | Temp. Max (°C) | Condizioni del tempo |
|---|---|---|---|---|---|---|---|
| COLLE RUTO | Campotosto (AQ) | 1384 | 13 | 0 | -3 | +8 | Assenza di precipitazioni |
| S. DONATO | Castel del Monte (AQ) | 1400 | 0 | 0 | -2 | +9 | Assenza di precipitazioni |
| FOSSETTA DI PAGANICA * | L'Aquila (AQ) | 1640 | 6 | 0 | N.P. | N.P. | Assenza di precipitazioni |
| VALLE FREDDA * | L'Aquila (AQ) | 1969 | 116 | 0 | N.P. | N.P. | Assenza di precipitazioni |

**(*) Rilievi fuori campo**

**L'INFORMAZIONE E' PREVENZIONE - LEGGI L'ATTUALE GRADO DI PERICOLO VALANGHE!**

**IL CAPO DEL CENTRO NAZIONALE METEOMONT**
**(Ten. Col. RFI Emanuela Gini)**
**FIRMA AUTOGRAFA OMESSA AI SENSI**
**DELL'ART.3 DEL D.LGS N.39/1993**

**Bollettino realizzato su scala sinottica-regionale (standard EAWS). La sua valutazione non può escludere in alcun modo la necessità di una seria e capace valutazione locale del pericolo (singolo pendio) che può essere anche sensibilmente diverso. Le previsioni meteorologiche sono relative all'orario UTC (per l'Italia +1 in inverno e +2 in estate).**