MINISTERO DELLA DIFESA

meteomont Servizio Nazionale di previsione neve e valanghe

EAWS EUROPEAN AVALANCHE WARNING SERVICES

CARABINIERI

P.N. ABRUZZO

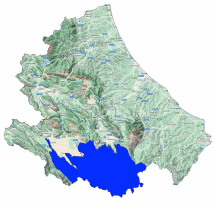

Bollettino Valanghe N. 345/2026 del 30/03/2026 ore 14.00
Validità 48 ore prossima emissione 31/03/2026

A cura del Servizio METEOMONT dell'ARMA dei CARABINIERI
In collaborazione con Servizio Meteorologico dell'Aeronautica militare

SITUAZIONE alle 14:00 del 30/03/2026

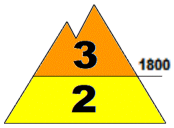

SITUAZIONE TIPO: neve a debole coesione e vento.



SITUAZIONE TIPO: situazione primaverile.

Quota neve (mslm)	Nord	Sud
	1200	1400

Altezza Neve (cm)	Neve al suolo	Neve Fresca	Quota (mslm)
	023	000	1466
	020	000	1470

VALANGHE OSSERVATE: Nessuna valanga.

PREVISIONI 31/03/2026

GRADO DI PERICOLO: MARCATO 3

SITUAZIONE TIPO: neve a debole coesione e vento.

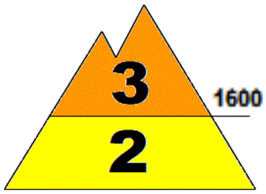

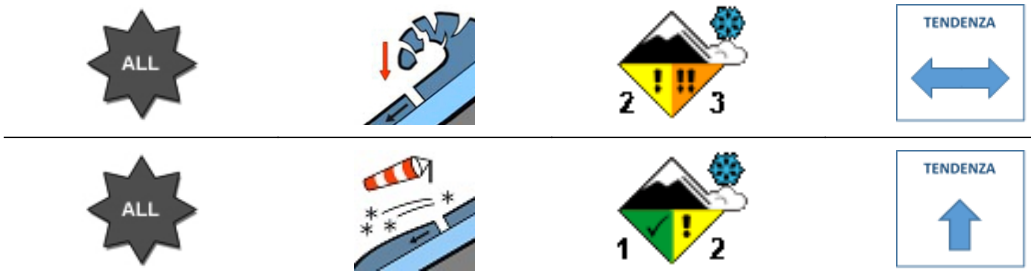

SITUAZIONE TIPO: neve a debole coesione e vento.

MANTO NEVOSO: La stabilità del manto nevoso è scarsa su alcuni punti (aree) per tutte le esposizioni al di sopra di 1600 mslm, possibili valanghe di dimensioni grandi.
La stabilità del manto nevoso è discreta su alcuni punti (aree) per tutte le esposizioni al di sotto di 1600 mslm, possibili valanghe di dimensioni medie.

AVVERTENZE

In considerazione delle avverse condizioni meteorologiche previste , le attività al di fuori delle piste battute e segnalate sono sconsigliate.

SCALA EUROPEA DEL GRADO DI PERICOLO VALANGHE

LEGENDA PROBLEMA

Bollettino realizzato su scala sinottica-regionale (standard EAWS). La sua valutazione non può escludere in alcun modo la necessità di una seria e capace valutazione locale del pericolo (singolo pendio) che può essere anche sensibilmente diverso. Le previsioni meteorologiche sono relative all'orario UTC (per l'Italia +1 in inverno e +2 in estate).

MINISTERO DELLA DIFESA

meteomont
Servizio Nazionale di previsione neve e valanghe

EAWS EUROPEAN AVALANCHE WARNING SERVICES

CARABINIERI

P.N. ABRUZZO

PREVISIONE METEO

Quota		31/03/2026 h6:00	31/03/2026 h12:00	31/03/2026 h18:00
1000	Venti	03 Nodi da N-Est	10 Nodi da N-Est	11 Nodi da N-Est
	Temperature	+00 °C	+00 °C	-01 °C
	Temp.percepita	-2 °C	-5 °C	-7 °C
2000	Venti	08 Nodi da N-Est	25 Nodi da N-Est	29 Nodi da N-Est
	Temperature	-04 °C	-03 °C	-04 °C
	Temp.percepita	-9 °C	-12 °C	-14 °C
3000	Venti	14 Nodi da Est	20 Nodi da N-Est	23 Nodi da Est
	Temperature	-11 °C	-07 °C	-06 °C
	Temp.percepita	-20 °C	-16 °C	-16 °C
Zero termico		1400-1600 m.	1400-1600 m.	1300-1500 m.
Fenomeno				
Stato del cielo				

LEGENDA FENOMENI

Assenza Fenomeni · Nebbia · Foschia · Pioggia debole · Pioggia moderata · Pioggia forte · Temporali

Nevicata debole · Nevicata moderata · Nevicata forte

STATO DEL CIELO

Sereno · Poco nuvoloso · Nuvoloso · Molto nuvoloso · Coperto

Parametri meteonivometrici registrati presso i campi di rilevamento il 30/03/2026.

Località	Comune	Quota (m.s.l.m.)	Altezza neve (cm)	Neve caduta nelle 24 ore (cm)	Temp. Min (°C)	Temp. Max (°C)	Condizioni del tempo
FORCA D'ACERO	Pescasseroli (AQ)	1480	7	0	-3	+13	Assenza di precipitazioni
VALLE GELATA	Pescocostanzo (AQ)	1466	23	0	-1	+6	Assenza di precipitazioni
COPPO DELL'ORSO	Villetta Barrea (AQ)	1520	14	0	-5	+2	Assenza di precipitazioni
LA PESCINA	Rivisondoli (AQ)	1470	20	0	-3	+4	Assenza di precipitazioni
PIANO AREMOGNA	Roccaraso (AQ)	1456	0	0	-4	+4	Assenza di precipitazioni
MIMOLA	Scanno (AQ)	1495	24	0	-5	+13	Assenza di precipitazioni

(*) Rilievi fuori campo

L'INFORMAZIONE E' PREVENZIONE - LEGGI L'ATTUALE GRADO DI PERICOLO VALANGHE!

IL CAPO DEL CENTRO NAZIONALE METEOMONT
(Ten. Col. RFI Emanuela Gini)
FIRMA AUTOGRAFA OMESSA AI SENSI
DELL'ART.3 DEL D.LGS N.39/1993

Bollettino realizzato su scala sinottica-regionale (standard EAWS). La sua valutazione non può escludere in alcun modo la necessità di una seria e capace valutazione locale del pericolo (singolo pendio) che può essere anche sensibilmente diverso. Le previsioni meteorologiche sono relative all'orario UTC (per l'Italia +1 in inverno e +2 in estate).