Bulletin d'estimation du risque d'avalanche
(valable en dehors des pistes balisées et ouvertes)

MASSIF : Aravis

Rédigé le lundi 30 mars 2026 à 16h

Estimation des risques pour le : MARDI 31 MARS

NOUVELLES PLAQUES À VENT SOUS LA FORTE BISE DE NNE.

3

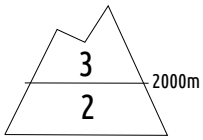

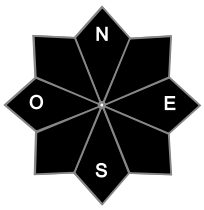

Au-dessus de 2000m indice de risque marqué, plus bas indice limité.

Départs spontanés : quelques accumulations dans la neige fraiche peuvent céder

Déclenchements provoqués : nouvelles plaques à vent dans la neige fraiche

Indices de risque : 5 très fort - 4 fort - 3 marqué - 2 limité - 1 faible -- En noir : les pentes les plus dangereuses

Stabilité du manteau neigeux

Situation avalancheuse typique : neige ventée

Déclenchements provoqués :
Plaques à vent dans la neige récente subsistent encore mais sont désormais moins réactives. **De nouvelles plaques se forment dans la neige fraiche sous le vent de NNE dans la nuit de lundi à mardi et continuent de se former mardi en journée. Elles sont plus nombreuses et plus épaisses au-dessus de 2000 m.** La Bise de NNE souffle fort, les plaques se trouvent jusqu'en milieu des pentes, parfois loin des crêtes. Elles sont souvent dures (parfois encore friables), très réactives au passage d'un skieur. Les cassures sont entre 20/30 cm et parfois 50/60 cm. Taille 1 à 2, rarement 3 (petite à moyenne, rarement 3).
Observables : accumulations, fissures devant les skis, changement de qualité de neige sur une courte distance.

Départs spontanés :
Quelques départs spontanés à cause du vent sont possibles. Taille 1 et rarement 2.

Qualité de la neige

Enneigement :
Bon pour une fin mars. On peut chausser skis ou raquettes dès 1200/1300 m. Attention, absence de sous-couches sous 1500/1600 m en versants S.

Qualité de la neige ce mardi :
5/15 cm de neige fraiche reposant sur une neige encore froide, dense, souple, sauf en versants S sous 2000 m où elle est déjà un peu croûtée. Neige soufflée dans les secteurs soumis à la Bise. Dure ou glacée près des crêtes.
Nombreuses corniches et accumulations/congères.

Aperçu météo pour le mardi 31 mars

	nuit	matin	après-midi	soir

Dernières averses de neige en fin de nuit. Nuageux en matinée avec des éclaircies de plus en plus larges. Fort vent dès 2000 m.

Pluie-Neige	600 m			
Iso 0 °C	1 300 m	1 300 m	1 600 m	1 200 m
Vent 2000 m	↓ 50 km/h	↙ 50 km/h	↙ 50 km/h	↙ 50 km/h
Vent 2500 m	↓ 65 km/h	↙ 65 km/h	↙ 60 km/h	↙ 60 km/h

Épaisseur de neige hors-piste

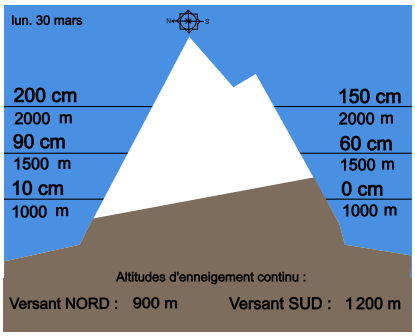

Précipitations à 1800 m

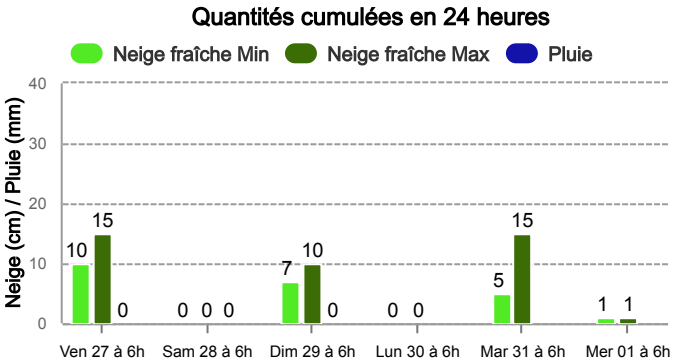

Tendance du mercredi 01 avril

2

Indice de risque limité

Le soleil contribue à stabiliser les plaques, les plaques à vent restent sensibles en altitude.

Pour consulter la vigilance en cours, veuillez vous rendre sur le site https://vigilance.meteofrance.fr/fr

Météo-France - 73 avenue de Paris, 94165 Saint-Mandé cedex - Contact : contact@meteo.fr

Rédigé par Météo-France avec la contribution des observateurs du réseau nivo-météorologiques. Partenariat : ANMSM (Maires de Stations de Montagne), DSF (Domaines Skiables de France), ADSP (Directeurs de Pistes et de la Sécurité des Stations de Sports d'Hiver) et autres acteurs de la montagne.

Bulletin neige & avalanches par téléphone au
0 892 68 10 20 Service 0,35 € / min + prix appel

RÉPUBLIQUE FRANÇAISE
Liberté Égalité Fraternité

METEO FRANCE
À VOS CÔTÉS, DANS UN CLIMAT QUI CHANGE

Bulletin d'estimation du risque d'avalanche

(valable en dehors des pistes balisées et ouvertes)

MASSIF : Aravis

Rédigé le lundi 30 mars 2026 à 16h

Conditions nivo-météo des 7 derniers jours

	mar. 24/03				mer. 25/03				jeu. 26/03				ven. 27/03				sam. 28/03				dim. 29/03				lun. 30/03			
	03h	09h	15h	21h	03h	09h	15h	21h	03h	09h	15h	21h	03h	09h	15h	21h	03h	09h	15h	21h	03h	09h	15h	21h	03h	09h	15h	21h
Météo																												
Vent (km/h)	10	15	10	10	40	60	70	60	60	60	60	60	60	80	40	30	40	40	30	50	60	50	30	30	25	35	55	70
à 2500m																												
Vent (km/h)	5	5	5	5	30	40	60	45	45	40	50	50	45	60	30	20	30	30	20	40	50	30	20	20	10	20	40	55
à 2000m																												

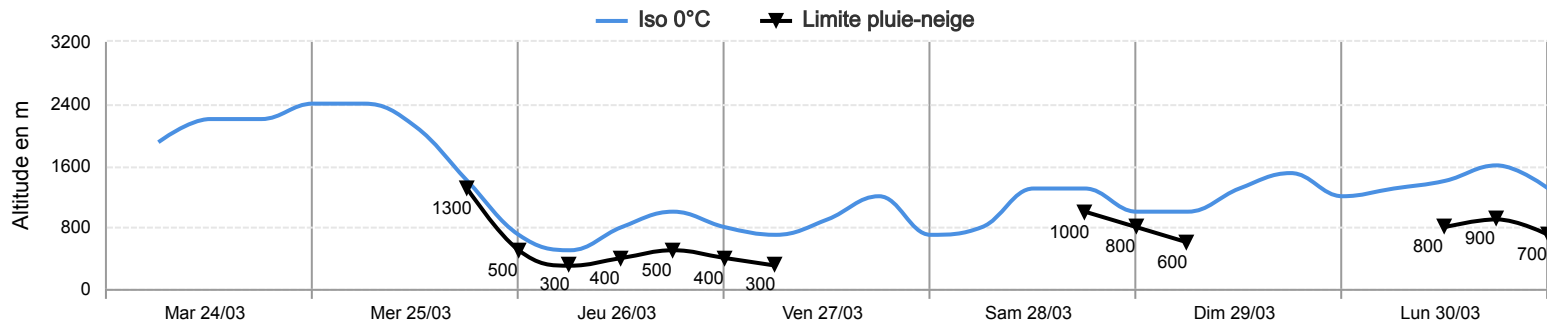

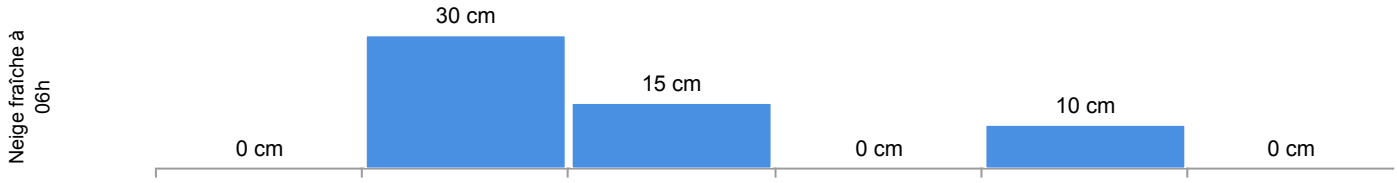

Risque d'avalanche	mar. 24/03	mer. 25/03	jeu. 26/03	ven. 27/03	sam. 28/03	dim. 29/03	lun. 30/03
	2	3	3	3	2	2	2

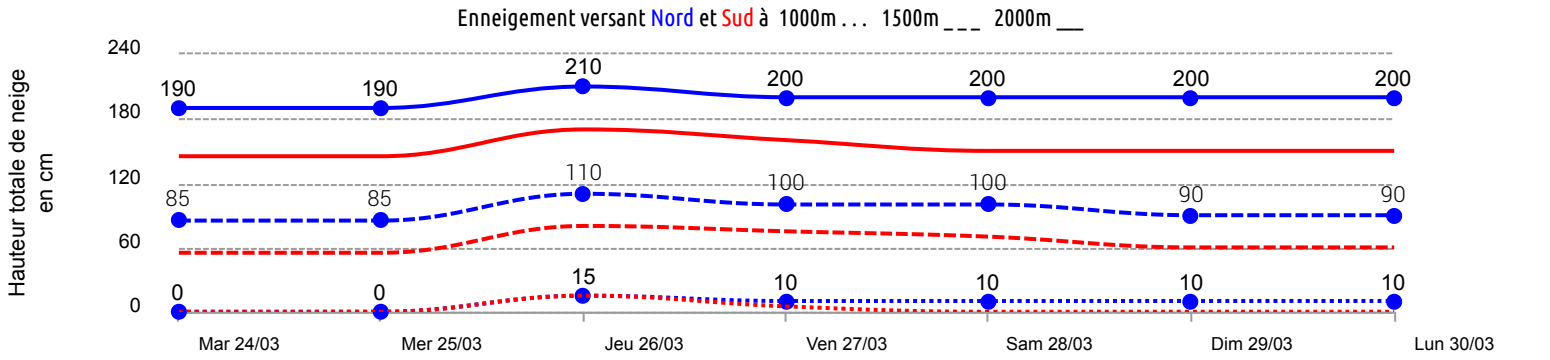

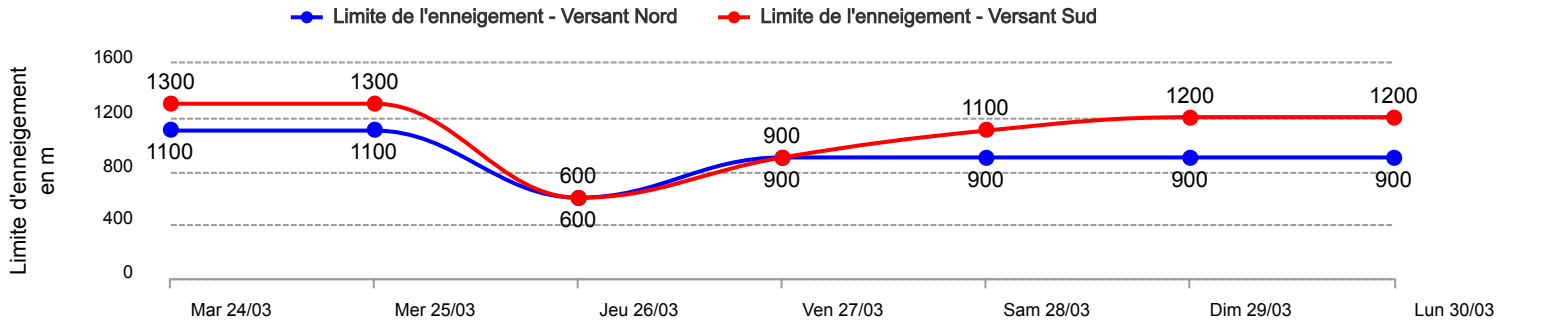

Pour consulter la vigilance en cours, veuillez vous rendre sur le site https://vigilance.meteofrance.fr/fr

Météo-France - 73 avenue de Paris, 94165 Saint-Mandé cedex - Contact : contact@meteo.fr

Rédigé par Météo-France avec la contribution des observateurs du réseau nivo-météorologiques. Partenariat : ANMSM (Maires de Stations de Montagne), DSF (Domaines Skiables de France), ADSP (Directeurs de Pistes et de la Sécurité des Stations de Sports d'Hiver) et autres acteurs de la montagne.

Bulletin neige & avalanches par téléphone au
0 892 68 10 20 Service 0,35 € / min + prix appel