Bulletin d'estimation du risque d'avalanche

(valable en dehors des pistes balisées et ouvertes)

MASSIF : Champsaur

Rédigé le lundi 30 mars 2026 à 16h

Estimation des risques pour le : MARDI 31 MARS

PLAQUES A VENT DANS LA NEIGE VENTÉE

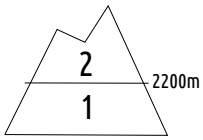

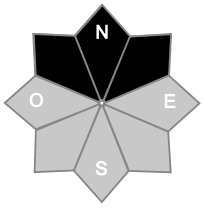

Au-dessus de 2200m indice de risque limité, plus bas indice faible.

Départs spontanés : une plaque surchargée par le vent peut céder spontanément. Taille limitée.

Déclenchements provoqués : instabilités dans la neige ventée, plus épaisses en bordure de l'Oisans.

Indices de risque : 5 très fort - 4 fort - 3 marqué - 2 limité - 1 faible -- En noir : les pentes les plus dangereuses

Stabilité du manteau neigeux

Situation avalancheuse typique : neige ventée

Déclenchements provoqués : plaques en place dans la neige ventée, d'autres en formation sous l'action d'un fort vent de nord là où il reste encore de la neige légère et transportable. Présentes en toutes orientations au-dessus de 2000/2200 m environ, elles sont néanmoins plus nombreuses et sensibles dans les orientations d'un large secteur nord (nord-ouest, nord et nord-est) ainsi que vers l'Oisans où les quantités de neige fraîche sont un peu plus importantes. Facilement déclenchables par le passage d'un skieur, ces instabilités génèrent des avalanches de taille petite (taille 1), voire moyenne (taille 2) aux plus hautes altitudes du massif.

Départs spontanés : rares ruptures par surcharge du au vent (rupture de corniche par exemple). Avalanche petite à moyenne (taille 1 à 2).

Qualité de la neige

L'enneigement est proche des normales ou excédentaire pour une fin mars.
Hauteurs de neige observées : 130 cm à la Nivôse d'Orcières à 2280 m, et 179 cm au-dessus de Prapic à 2480 m.

Limite d'enneigement skiable : dès 1400 m en ubacs favorables (terrains herbeux, pistes forestières), 1700/1800 m en adrets pas trop raides.

État de la neige de surface : neige récente fortement travaillée par le vent, mais localement encore légère dans les secteurs bien abrités. Sur les crêtes, d'épaisses corniches côtoient des zones pelées par le vent.
En versant sud, neige croutée sous 2500 m.

Aperçu météo pour le mardi 31 mars

	nuit	matin	après-midi	soir

Temps froid, sec et venté. 0° à 2000 m et -9° à 3000 m.

Pluie-Neige				
Iso 0 °C	1 600 m	1 300 m	1 800 m	1 600 m
Vent 2000 m	60 km/h	45 km/h	40 km/h	35 km/h
Vent 3000 m	100 km/h	80 km/h	60 km/h	50 km/h

Épaisseur de neige hors-piste

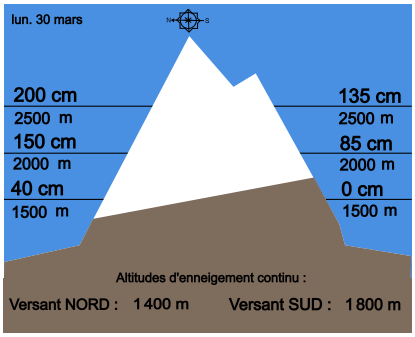

Précipitations à 1800 m

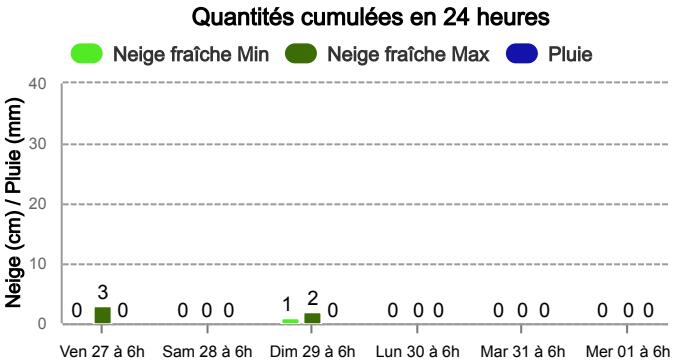

Tendance du mercredi 01 avril

Indice de risque limité

Maintien d'un risque limité. Le vent de nord à nord-est modéré continue de durcir le manteau neigeux.

Pour consulter la vigilance en cours, veuillez vous rendre sur le site https://vigilance.meteofrance.fr/fr

Météo-France - 73 avenue de Paris, 94165 Saint-Mandé cedex - Contact : contact@meteo.fr

Rédigé par Météo-France avec la contribution des observateurs du réseau nivo-météorologiques. Partenariat : ANMSM (Maires de Stations de Montagne), DSF (Domaines Skiables de France), ADSP (Directeurs de Pistes et de la Sécurité des Stations de Sports d'Hiver) et autres acteurs de la montagne.

Bulletin neige & avalanches par téléphone au
0 892 68 10 20 Service 0,35 € / min + prix appel

RÉPUBLIQUE FRANÇAISE
Liberté Égalité Fraternité

METEO FRANCE
À VOS CÔTÉS, DANS UN CLIMAT QUI CHANGE

Bulletin d'estimation du risque d'avalanche

(valable en dehors des pistes balisées et ouvertes)

MASSIF : Champsaur

Rédigé le lundi 30 mars 2026 à 16h

Conditions nivo-météo des 7 derniers jours

	mar. 24/03				mer. 25/03				jeu. 26/03				ven. 27/03				sam. 28/03				dim. 29/03				lun. 30/03			
	03h	09h	15h	21h	03h	09h	15h	21h	03h	09h	15h	21h	03h	09h	15h	21h	03h	09h	15h	21h	03h	09h	15h	21h	03h	09h	15h	21h
Météo																												
Vent (km/h)	15	10	10	10	20	35	60	70	70	70	70	70	65	50	30	20	15	20	30	35	25	40	25	20	30	50	80	100
à 3000m																												
Vent (km/h)	10	10	10	5	5	15	50	55	50	40	50	60	50	10	10	10	10	10	15	20	15	25	20	15	20	40	70	80
à 2000m																												

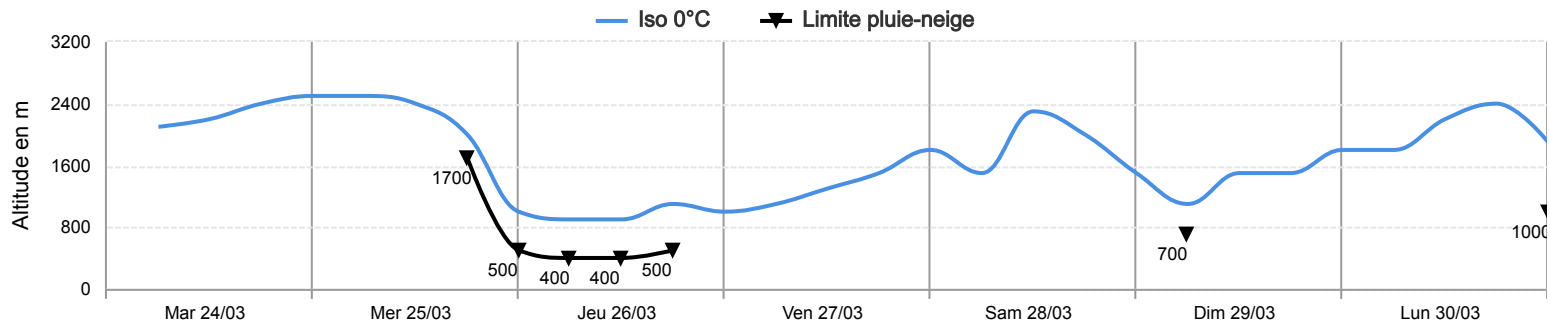

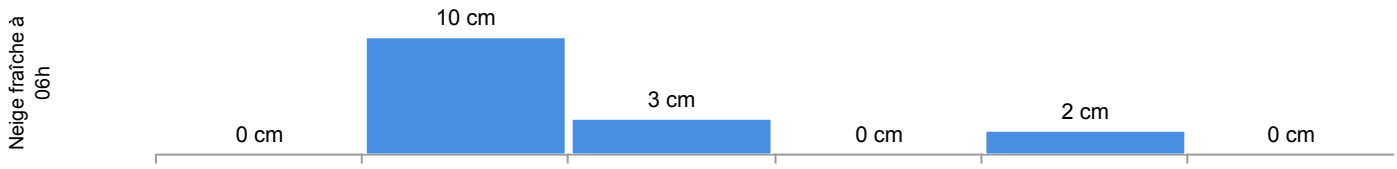

Risque d'avalanche	mar. 24/03	mer. 25/03	jeu. 26/03	ven. 27/03	sam. 28/03	dim. 29/03	lun. 30/03
	2	2	3	3	2	2	2

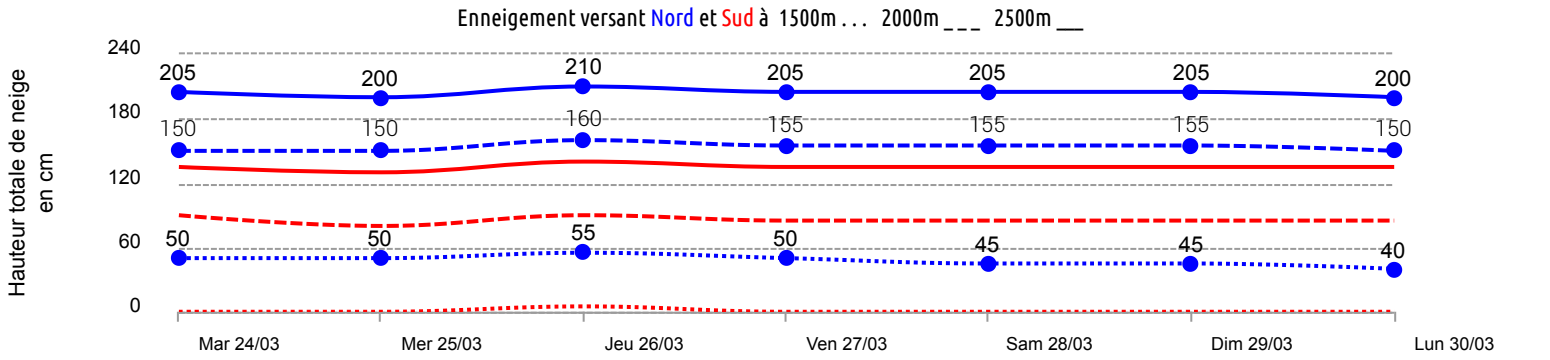

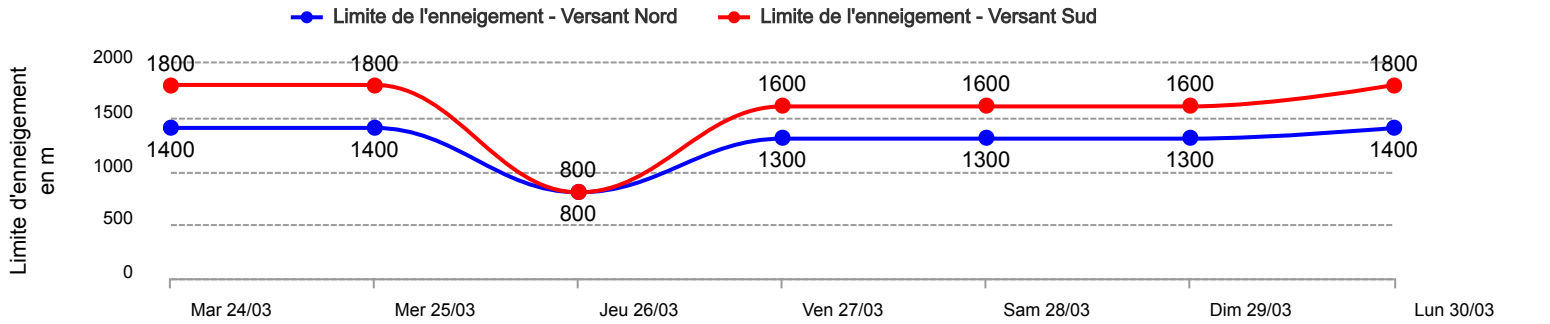

Pour consulter la vigilance en cours, veuillez vous rendre sur le site https://vigilance.meteofrance.fr/fr

Météo-France - 73 avenue de Paris, 94165 Saint-Mandé cedex - Contact : contact@meteo.fr

Bulletin neige & avalanches par téléphone au **0 892 68 10 20** Service 0,35 € / min + prix appel

Rédigé par Météo-France avec la contribution des observateurs du réseau nivo-météorologiques. Partenariat : ANMSM (Maires de Stations de Montagne), DSF (Domaines Skiables de France), ADSP (Directeurs de Pistes et de la Sécurité des Stations de Sports d'Hiver) et autres acteurs de la montagne.