Bulletin d'estimation du risque d'avalanche

(valable en dehors des pistes balisées et ouvertes)

MASSIF : Cinto Rotondo

Rédigé le lundi 30 mars 2026 à 16h

Estimation des risques pour le : MARDI 31 MARS

INSTABILITÉS EN ALTITUDE

2

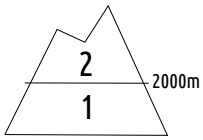

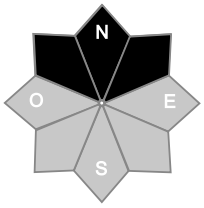

Au-dessus de 2000m indice de risque limité, plus bas indice faible.

Départs spontanés : rares coulées de neige récente humide

Déclenchements provoqués : plaques à vent difficilement sollicitables, encore présentes en altitude au-dessus de 2000 m

Indices de risque : 5 très fort - 4 fort - 3 marqué - 2 limité - 1 faible -- En noir : les pentes les plus dangereuses

Stabilité du manteau neigeux

Situation avalancheuse typique : neige ventée

Déclenchements provoqués : de fines plaques à vent sont en place dans les pentes raides en toutes orientations, majoritairement au-dessus de 2000 m issues des chutes de neige précédentes. Elles peuvent engendrer des avalanches de taille petite à moyenne (taille 1 à 2) avec des cassures de 10/20 cm voire 30 cm en versants ombragés.
Départs spontanés : Les quantités de neige attendues restent assez faibles. Les départs spontanés attendus sont peu probables avec des températures assez froides et un rayonnement limité par la couche nuageuse l'après-midi.
Autres : Nombreuses surfaces dures et glacées, pouvant être recouvertes de quelques centimètres de neige récente. Présence de corniches.

Qualité de la neige

Qualification de l'enneigement : L'enneigement est excellent pour la saison au-dessus de 1600 m. Au Val d'Ese, on estime à un peu plus de 2m00 la hauteur de neige à 1800 m. À Ghisoni Capanelle, on mesure environ 3m00 dans les combes abritées.
Limite d'enneigement skiable : 1500 m.
État de la neige : En surface, on trouve 10 à 20 cm de neige récente et ventée, voire plus localement. Cette couche, qui poursuit son tassement, recouvre un manteau neigeux assez dur, ayant connu un cycle de regel. En surface, elle peut être partiellement croûtée le matin après le regel nocturne puis l'humidification reprend rapidement en versants ensoleillés. En secteurs plus ombragés ou à soleil plus rasant, elle reste lourde et profonde, ou bien partiellement densifiée par le vent. Neige restant croûtée dans les secteurs ombragés raides.

Aperçu météo pour le mardi 31 mars

	nuit	matin	après-midi	soir
	Averses en fin de nuit, se poursuivant en matinée en baissant en intensité.			
Pluie-Neige	1 000 m	900 m		
Iso 0 °C	1 300 m	1 200 m	1 400 m	1 500 m
Vent 1500 m	45 km/h	60 km/h	60 km/h	65 km/h
Vent 3000 m	50 km/h	65 km/h	65 km/h	70 km/h

Épaisseur de neige hors-piste

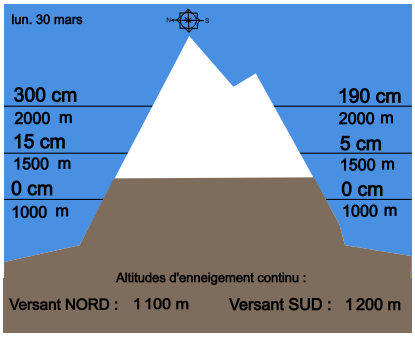

Précipitations à 1800 m

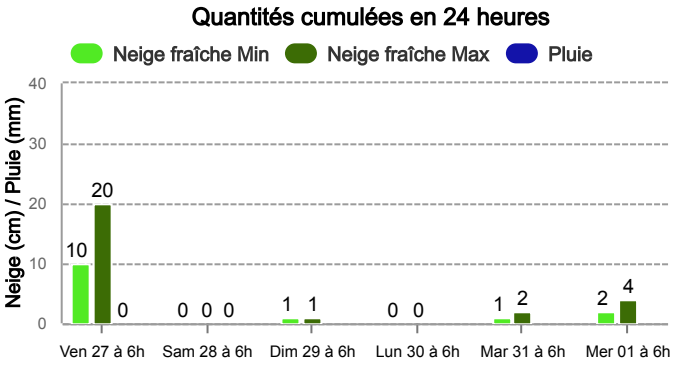

Tendance du mercredi 01 avril

2

Indice de risque limité

Pas dévolution notable en termes de risque.

Pour consulter la vigilance en cours, veuillez vous rendre sur le site https://vigilance.meteofrance.fr/fr

Météo-France - 73 avenue de Paris, 94165 Saint-Mandé cedex - Contact : contact@meteo.fr

Rédigé par Météo-France avec la contribution des observateurs du réseau nivo-météorologiques. Partenariat : ANMSM (Maires de Stations de Montagne), DSF (Domaines Skiables de France), ADSP (Directeurs de Pistes et de la Sécurité des Stations de Sports d'Hiver) et autres acteurs de la montagne.

Bulletin neige & avalanches par téléphone au
0 892 68 10 20 Service 0,35 € / min + prix appel

RÉPUBLIQUE FRANÇAISE
Liberté Égalité Fraternité

METEO FRANCE
À VOS CÔTÉS, DANS UN CLIMAT QUI CHANGE

Bulletin d'estimation du risque d'avalanche

(valable en dehors des pistes balisées et ouvertes)

MASSIF : Cinto Rotondo

Rédigé le lundi 30 mars 2026 à 16h

Conditions nivo-météo des 7 derniers jours

	mar. 24/03				mer. 25/03				jeu. 26/03				ven. 27/03				sam. 28/03				dim. 29/03				lun. 30/03			
	03h	09h	15h	21h	03h	09h	15h	21h	03h	09h	15h	21h	03h	09h	15h	21h	03h	09h	15h	21h	03h	09h	15h	21h	03h	09h	15h	21h
Météo																												
Vent (km/h)	30	25	20	20	20	60	80	120	110	85	90	90	50	40	35	50	30	15	20	10	15	35	45	30	25	25	40	45
à 3000m																												
Vent (km/h)	5	10	10	10	10	30	50	80	85	60	60	60	35	10	25	30	20	15	20	10	10	35	45	30	25	20	30	35
à 1500m																												

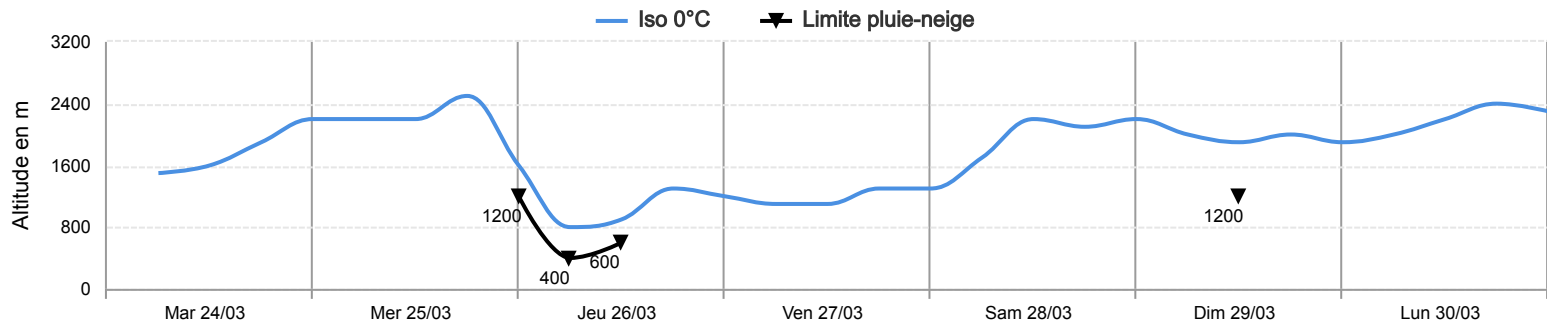

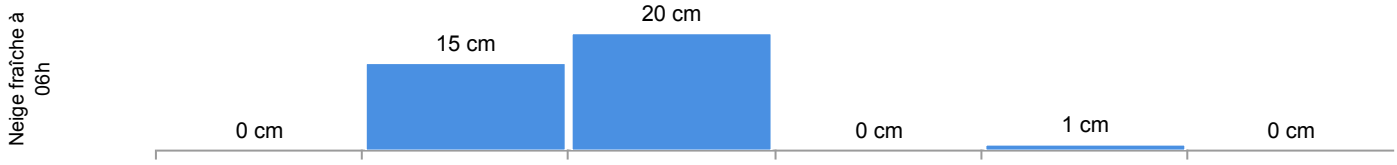

Risque d'avalanche	mar. 24/03	mer. 25/03	jeu. 26/03	ven. 27/03	sam. 28/03	dim. 29/03	lun. 30/03
	2	2	2	2	2	2	2

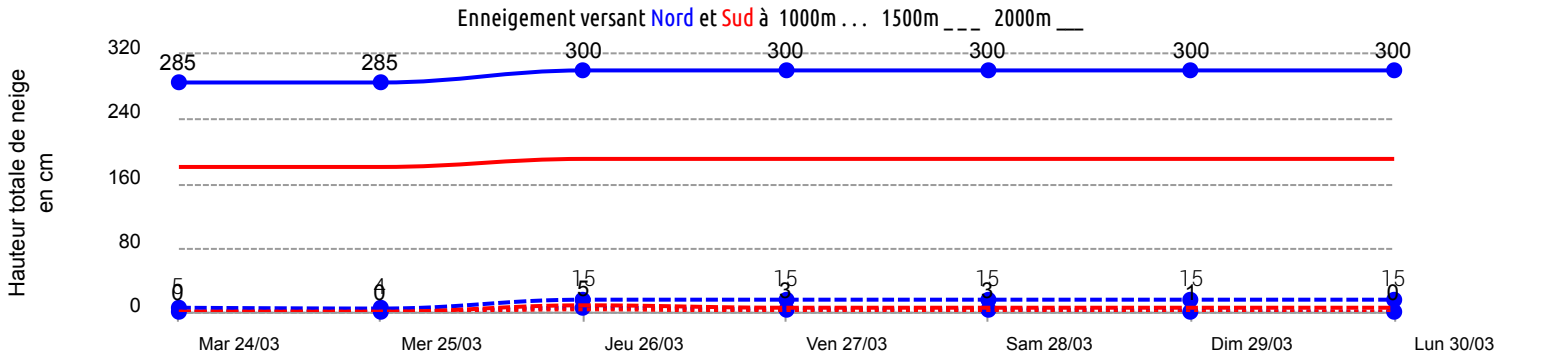

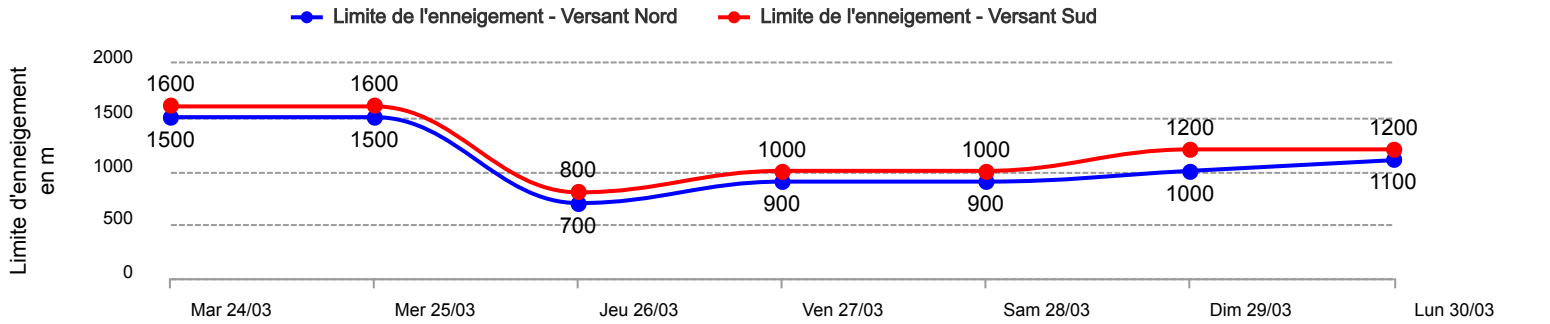

Pour consulter la vigilance en cours, veuillez vous rendre sur le site https://vigilance.meteofrance.fr/fr

Météo-France - 73 avenue de Paris, 94165 Saint-Mandé cedex - Contact : contact@meteo.fr

Bulletin neige & avalanches par téléphone au

0 892 68 10 20 Service 0,35 € / min + prix appel

Rédigé par Météo-France avec la contribution des observateurs du réseau nivo-météorologiques. Partenariat : ANMSM (Maires de Stations de Montagne), DSF (Domaines Skiables de France), ADSP (Directeurs de Pistes et de la Sécurité des Stations de Sports d'Hiver) et autres acteurs de la montagne.