Bulletin d'estimation du risque d'avalanche
(valable en dehors des pistes balisées et ouvertes)

MASSIF : Embrunais Parpaillon

Rédigé le lundi 30 mars 2026 à 16h

Estimation des risques pour le : MARDI 31 MARS

PLAQUES A VENT DANS LA NEIGE RÉCENTE VENTÉE

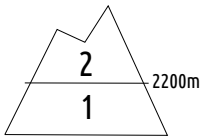

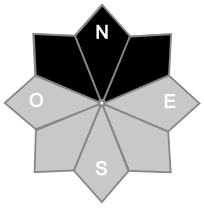

Au-dessus de 2200m indice de risque limité, plus bas indice faible.

Départs spontanés : une plaque surchargée par le vent peut céder spontanément. Taille limitée.

Déclenchements provoqués : instabilités dans la neige ventée, plus épaisses en altitude.

Indices de risque : 5 très fort - 4 fort - 3 marqué - 2 limité - 1 faible -- En noir : les pentes les plus dangereuses

Stabilité du manteau neigeux

Situation avalancheuse typique : neige ventée

Déclenchements provoqués : plaques en place dans la neige ventée, d'autres en formation sous l'action d'un fort vent de nord là où il reste encore de la neige légère et transportable. Présentes en toutes orientations au-dessus de 2000/2200 m environ, elles sont néanmoins plus nombreuses et sensibles dans les orientations d'un large secteur nord (nord-ouest, nord et nord-est) ainsi que vers le Parpaillon où les quantités de neige récente sont un peu plus importantes. Facilement déclenchables par le passage d'un skieur, ces instabilités génèrent des avalanches de taille petite (taille 1), voire moyenne (taille 2) aux plus hautes altitudes du massif.

Départs spontanés : rares ruptures par surcharge du au vent (rupture de corniche par exemple). Avalanche petite à moyenne (taille 1 à 2).

Qualité de la neige

L'enneigement est proche des normales pour une fin mars.
Hauteurs de neige observées : 107 cm à la nivôse du Parpaillon à 2500 m.

Limite d'enneigement skiable : au plus bas à 1500 m en ubacs bien protégés ou sur pistes forestières, plutôt 2000/2100 m en adrets.

État de la neige de surface : neige récente fortement travaillée par le vent, mais localement encore légère dans les secteurs bien abrités. Crêtes parfois décapées. En versant sud, neige croutée sous 2500 m.

Aperçu météo pour le mardi 31 mars

	nuit	matin	après-midi	soir

Temps froid, sec et venté. 0° à 2000 m et -9° à 3000 m.

Pluie-Neige				
Iso 0 °C	1 600 m	1 400 m	1 800 m	1 500 m
Vent 2000 m	80 km/h	60 km/h	45 km/h	30 km/h
Vent 3000 m	100 km/h	80 km/h	60 km/h	45 km/h

Épaisseur de neige hors-piste

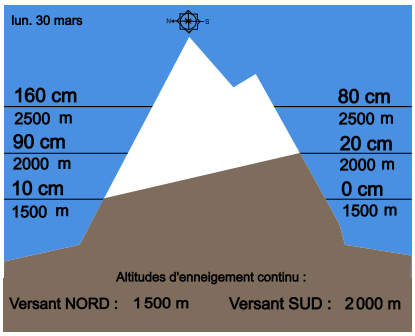

Précipitations à 1800 m

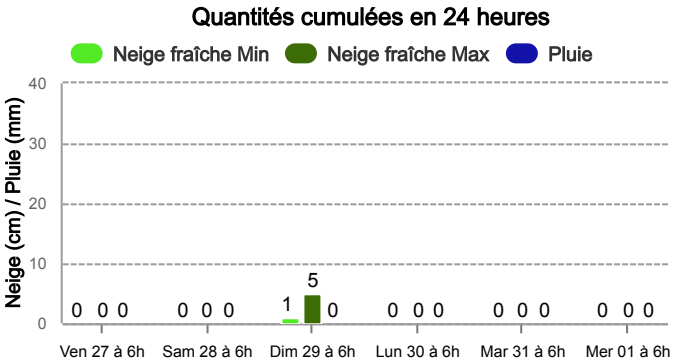

Tendance du mercredi 01 avril

Indice de risque limité

Maintien d'un risque limité. Le vent de nord à nord-est modéré continue de durcir le manteau neigeux.

Pour consulter la vigilance en cours, veuillez vous rendre sur le site https://vigilance.meteofrance.fr/fr

Météo-France - 73 avenue de Paris, 94165 Saint-Mandé cedex - Contact : contact@meteo.fr

Rédigé par Météo-France avec la contribution des observateurs du réseau nivo-météorologiques. Partenariat : ANMSM (Maires de Stations de Montagne), DSF (Domaines Skiables de France), ADSP (Directeurs de Pistes et de la Sécurité des Stations de Sports d'Hiver) et autres acteurs de la montagne.

Bulletin neige & avalanches par téléphone au
0 892 68 10 20 Service 0,35 € / min + prix appel

RÉPUBLIQUE FRANÇAISE
Liberté Égalité Fraternité

METEO FRANCE
À VOS CÔTÉS, DANS UN CLIMAT QUI CHANGE

Bulletin d'estimation du risque d'avalanche
(valable en dehors des pistes balisées et ouvertes)
MASSIF : Embrunais Parpaillon

Rédigé le lundi 30 mars 2026 à 16h

Conditions nivo-météo des 7 derniers jours

	mar. 24/03				mer. 25/03				jeu. 26/03				ven. 27/03				sam. 28/03				dim. 29/03				lun. 30/03			
	03h	09h	15h	21h	03h	09h	15h	21h	03h	09h	15h	21h	03h	09h	15h	21h	03h	09h	15h	21h	03h	09h	15h	21h	03h	09h	15h	21h
Météo																												
Vent (km/h)	25	15	15	15	30	50	60	70	30	60	70	70	50	40	30	10	30	25	30	25	25	40	25	20	30	50	80	100
à 3000m																												
Vent (km/h)	10	10	20	5	10	15	50	30	20	50	60	50	45	40	20	10	10	10	20	20	20	30	25	15	10	20	50	80
à 2000m																												

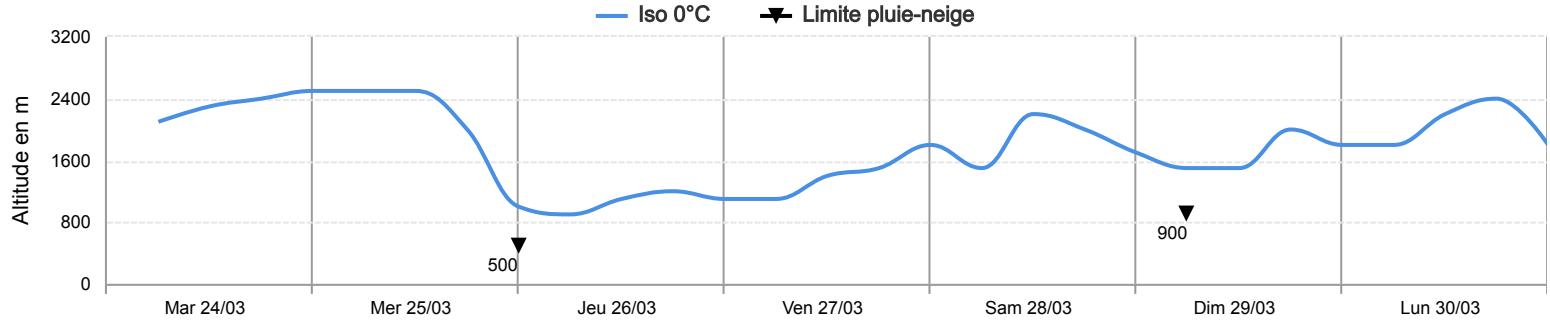

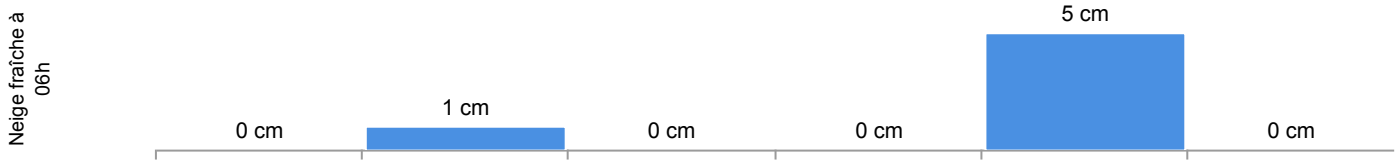

Risque d'avalanche	mar. 24/03	mer. 25/03	jeu. 26/03	ven. 27/03	sam. 28/03	dim. 29/03	lun. 30/03
	2	2	3	2	2	2	2

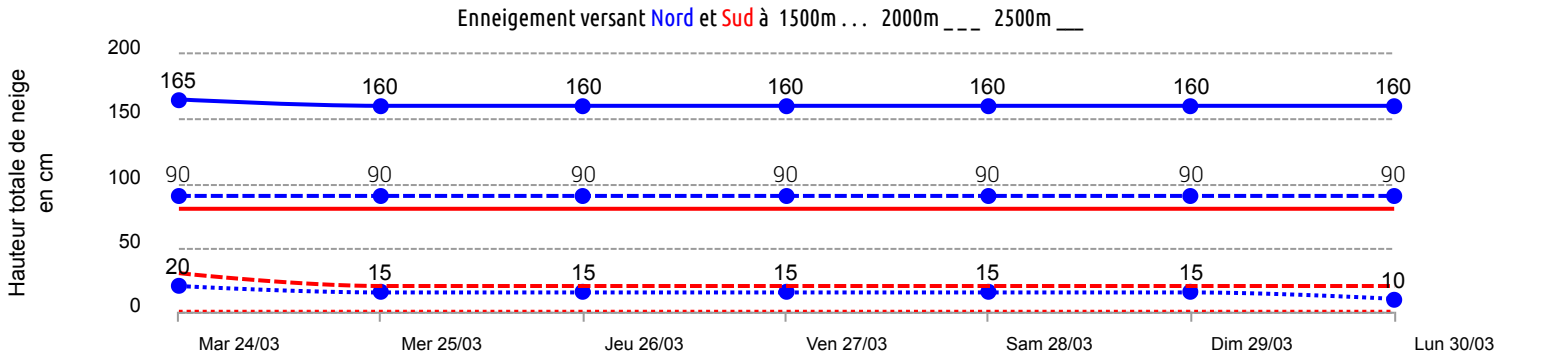

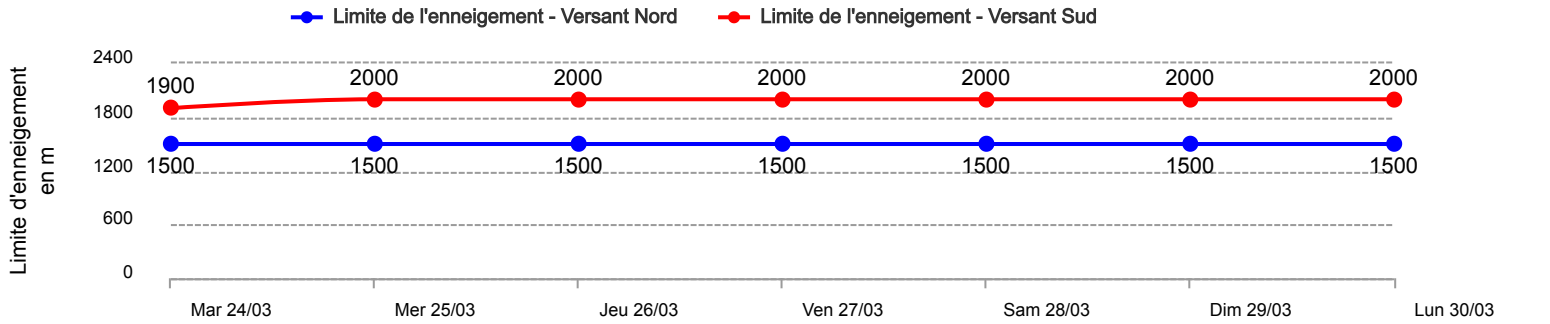

Pour consulter la vigilance en cours, veuillez vous rendre sur le site https://vigilance.meteofrance.fr/fr

Météo-France - 73 avenue de Paris, 94165 Saint-Mandé cedex - Contact : contact@meteo.fr

Rédigé par Météo-France avec la contribution des observateurs du réseau nivo-météorologiques. Partenariat : ANMSM (Maires de Stations de Montagne), DSF (Domaines Skiables de France), ADSP (Directeurs de Pistes et de la Sécurité des Stations de Sports d'Hiver) et autres acteurs de la montagne.

Bulletin neige & avalanches par téléphone au
0 892 68 10 20 Service 0,35 € / min + prix appel