Bulletin d'estimation du risque d'avalanche
(valable en dehors des pistes balisées et ouvertes)

MASSIF : Haute-Maurienne

Rédigé le lundi 30 mars 2026 à 16h

Estimation des risques pour le : MARDI 31 MARS

L'HIVER FAIT DE LA RÉSISTANCE AVEC DU VENT FORT EN ALTITUDE, DU FROID POUR LA SAISON ET QUELQUES CHUTES DE NEIGE ATTENDUES DANS LA NUIT DE LUNDI À MARDI. NOUVELLES PLAQUES EN FORMATION DANS CES CONDITIONS.

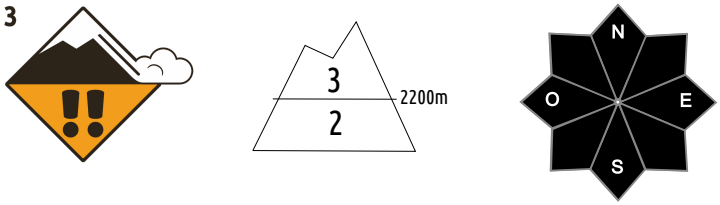

Au-dessus de 2200m indice de risque marqué, plus bas indice limité.

Départs spontanés : Petite au soleil dans les pentes très raides et rocheuses

Déclenchements provoqués : Plaques à vent surtout au dessus de 2200m

Indices de risque : 5 très fort - 4 fort - 3 marqué - 2 limité - 1 faible -- En noir : les pentes les plus dangereuses

Stabilité du manteau neigeux

Situation avalancheuse typique : neige ventée

Déclenchements provoqués : Plaques friables à dures présentes dans les pentes en neige récentes travaillées par le vent. Au dessus de 2200m et en Nord les volumes mobilisables sont encore conséquents et le transport en cours ce lundi est efficace. Demain mardi le passage d'un skieur dans une pente raide pourra alors suffire à déclencher une belle plaque récemment formée avec une cassure pouvant facilement dépasser les 50 cm, taille 2. Ces plaques se trouveront possiblement un peu en tous versants de haute altitude (au dessus de 2400m environ) dès que l'on rencontre des zones d'accumulations de neige récente (donc souvent loin des crêtes qui sont elles le plus souvent complètement gelées car décapées par le vent en cours ce lundi).
Sous 2400m moins de neige mobilisable ce lundi plaque possible mardi dans une accumulation mais beaucoup plus petite et localisée, taille 1.
Départs spontanés : Rares et petites purges de neige fraiche s'humidifiant au soleil dans les pentes rocheuses raides qui auront accumulées suffisamment de neige fraiche. Escargots, boulettes partant sous les rochers et au plus une taille 1.

Qualité de la neige

Enneigement : encore un peu au dessus de la moyenne. , sauf aux plus basses altitudes où les hauteurs de neige sont tout juste correctes pour la saison.

Limite skiable : vers 1300 m en Nord, 1700 m en Sud.

Qualité de la neige : neige poudreuse à l'abri du vent donc essentiellement à basse altitude dans les zones boisées ou au moins avec quelques arbres isolés. Au dessus de la ligne des arbres neige le plus souvent cartonnée à durci par le vent, aspect poudreux à l'abri du vent. Crêtes et cols en neige ventée très dure, ou en glace avec beaucoup de cailloux.
L'après midi, humidification de surface au soleil (pente ouest surtout) même si l'air reste encore frais pour la saison.

Aperçu météo pour le mardi 31 mars

Bouché au lever du jour retour de larges éclaircies en cours de matinée. Vent moins fort que nuit précédente mais toujours soutenu sur sommets et cols

	nuit	matin	après-midi	soir
Pluie-Neige	1 100 m			
Iso 0 °C	1 500 m	1 400 m	1 700 m	1 300 m
Vent 2500 m	↓ 25 km/h	↓ 30 km/h	↓ 35 km/h	↙ 35 km/h
Vent 3500 m	↓ 60 km/h	↙ 50 km/h	↙ 50 km/h	↙ 50 km/h

Épaisseur de neige hors-piste

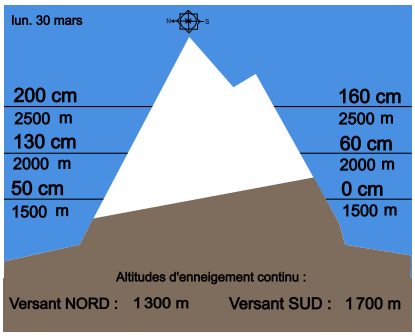

Précipitations à 1800 m

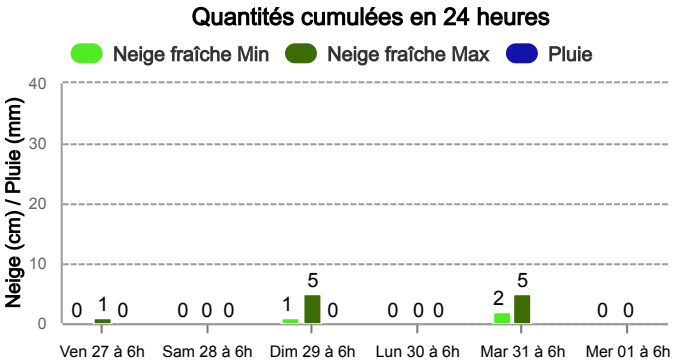

Tendance du mercredi 01 avril

2

Indice de risque limité

Stabilisation assez rapide des quelques plaques formées ce lundi et mardi.

Pour consulter la vigilance en cours, veuillez vous rendre sur le site https://vigilance.meteofrance.fr/fr

Météo-France - 73 avenue de Paris, 94165 Saint-Mandé cedex - Contact : contact@meteo.fr

Rédigé par Météo-France avec la contribution des observateurs du réseau nivo-météorologiques. Partenariat : ANMSM (Maires de Stations de Montagne), DSF (Domaines Skiables de France), ADSP (Directeurs de Pistes et de la Sécurité des Stations de Sports d'Hiver) et autres acteurs de la montagne.

Bulletin neige & avalanches par téléphone au
0 892 68 10 20 Service 0,35 € / min + prix appel

RÉPUBLIQUE FRANÇAISE
Liberté Égalité Fraternité

METEO FRANCE
À VOS CÔTÉS, DANS UN CLIMAT QUI CHANGE

Bulletin d'estimation du risque d'avalanche
(valable en dehors des pistes balisées et ouvertes)
MASSIF : Haute-Maurienne

Rédigé le lundi 30 mars 2026 à 16h

Conditions nivo-météo des 7 derniers jours

	mar. 24/03				mer. 25/03				jeu. 26/03				ven. 27/03				sam. 28/03				dim. 29/03				lun. 30/03			
	03h	09h	15h	21h	03h	09h	15h	21h	03h	09h	15h	21h	03h	09h	15h	21h	03h	09h	15h	21h	03h	09h	15h	21h	03h	09h	15h	21h
Météo																												
Vent (km/h)	20	20	15	35	50	65	85	100	100	95	90	90	60	30	30	30	30	40	40	30	30	30	30	30	50	95	105	75
à 3500m																												
Vent (km/h)	10	10	10	15	25	45	70	85	90	80	75	70	50	25	20	20	20	30	30	20	20	20	20	20	20	55	70	35
à 2500m																												

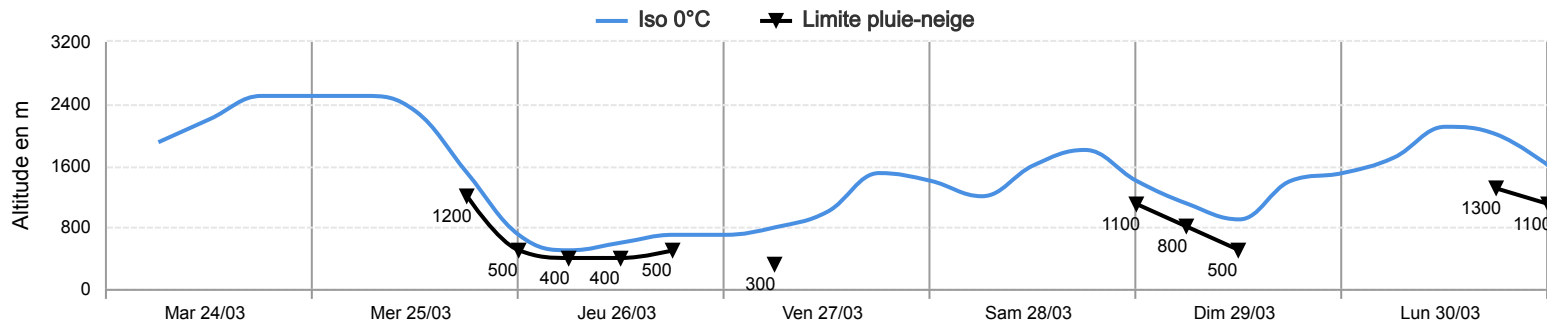

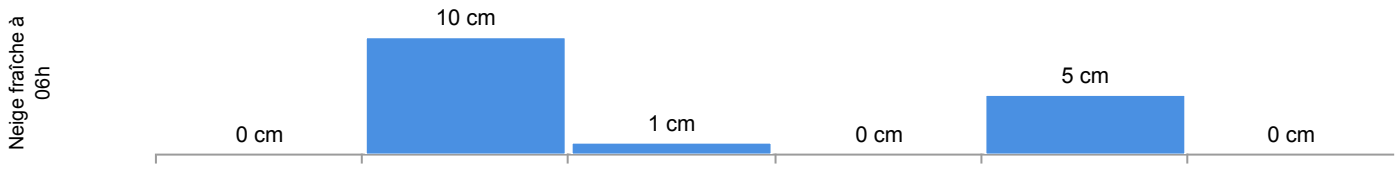

Risque d'avalanche	mar. 24/03	mer. 25/03	jeu. 26/03	ven. 27/03	sam. 28/03	dim. 29/03	lun. 30/03
	2	3	3	3	2	2	2

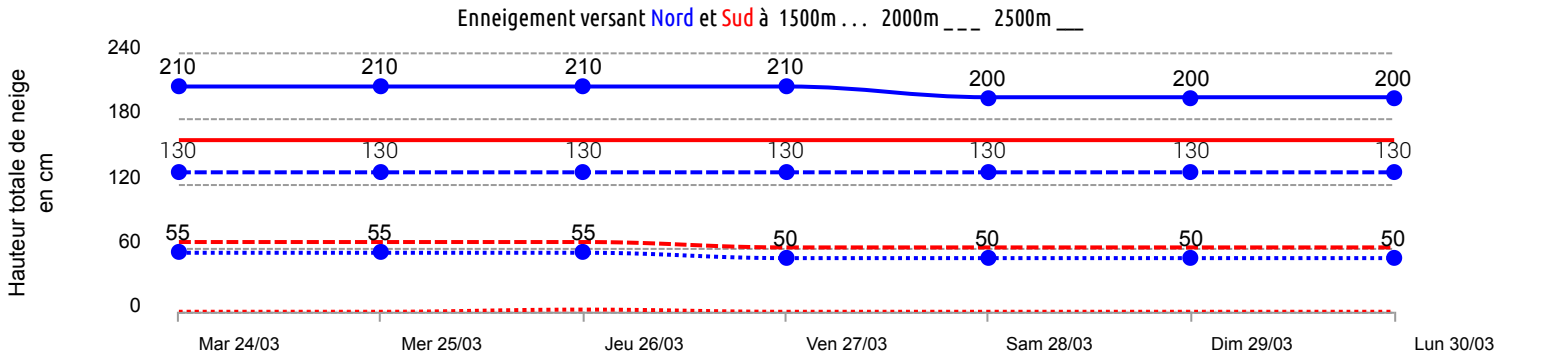

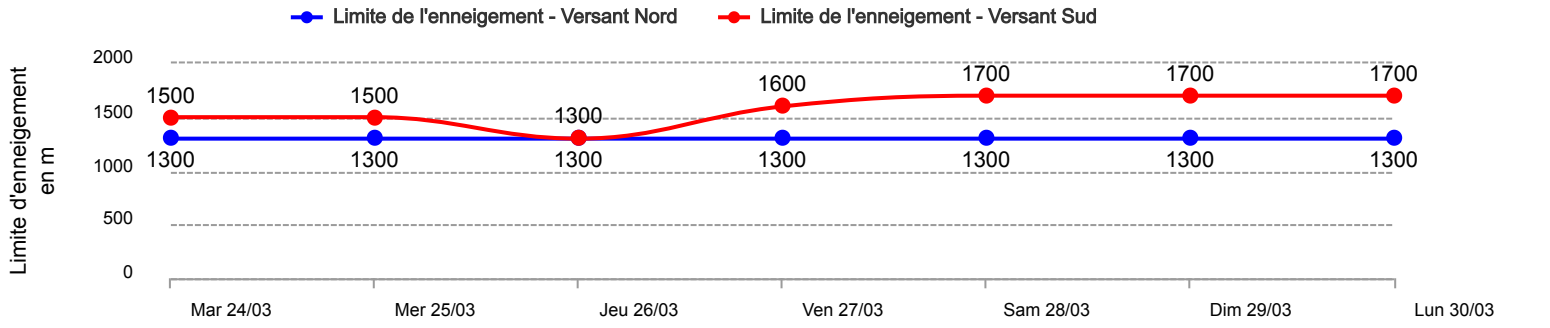

Pour consulter la vigilance en cours, veuillez vous rendre sur le site https://vigilance.meteofrance.fr/fr

Météo-France - 73 avenue de Paris, 94165 Saint-Mandé cedex - Contact : contact@meteo.fr

Rédigé par Météo-France avec la contribution des observateurs du réseau nivo-météorologiques. Partenariat : ANMSM (Maires de Stations de Montagne), DSF (Domaines Skiables de France), ADSP (Directeurs de Pistes et de la Sécurité des Stations de Sports d'Hiver) et autres acteurs de la montagne.

Bulletin neige & avalanches par téléphone au
0 892 68 10 20 Service 0,35 € / min + prix appel