# Bulletin d'estimation du risque d'avalanche

(valable en dehors des pistes balisées et ouvertes)

# MASSIF : Mont-Blanc

Rédigé le lundi 30 mars 2026 à 16h

## Estimation des risques pour le : MARDI 31 MARS

**NOUVELLES PLAQUES À VENT SOUS LA FORTE BISE DE NNE.**

3

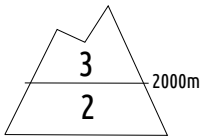


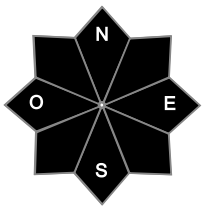


Au-dessus de 2000m indice de risque marqué, plus bas indice limité.

**Départs spontanés :** quelques accumulations dans la neige fraiche peuvent céder

**Déclenchements provoqués :** nouvelles plaques à vent dans la neige fraiche

Indices de risque : 5 très fort - 4 fort - 3 marqué - 2 limité - 1 faible -- En noir : les pentes les plus dangereuses

## Stabilité du manteau neigeux

**Situation avalancheuse typique :** neige ventée

Déclenchements provoqués :

Plaques à vent dans la neige récente subsistent encore mais sont désormais moins réactives. **De nouvelles plaques se forment dans la neige fraiche sous le vent de NNE dans la nuit de lundi à mardi et continuent de se former mardi en journée. Elles sont plus nombreuses et plus épaisses au-dessus de 2000 m.** La Bise de NNE souffle fort, les plaques se trouvent jusqu'en milieu des pentes, parfois loin des crêtes. Elles sont souvent dures (parfois encore friables), très réactives au passage d'un skieur. Les cassures sont entre 20/30 cm et parfois 50/60 cm. Taille 1 à 2, rarement 3 (petite à moyenne, rarement 3).

*Observables : accumulations, fissures devant les skis, changement de qualité de neige sur une courte distance.*

* Anecdotique mais pas impossible : ces plaques reposent localement sur une couche fragile persistante enfouie. En versants N, au-dessus de 2200 m. Déclenchement par skieur très peu probable, mais départ possible en cascade (une première avalanche, ou une chute de corniche, déclenche une plaque épaisse). Taille 2 à 3 (moyenne à grande).

Départs spontanés :

Quelques accumulations de neige récente peuvent céder dans des pentes très raides, ou des entrées de couloirs chargés par le vent de NO puis de NE en journée mardi, surtout au-dessus de 2800 m. Départs ponctuels ou en plaques peu larges. Taille 1, éventuellement 2.

## Qualité de la neige

Enneigement :

Bon pour une fin mars. On peut chausser skis ou raquettes dès 1200/1300 m. Attention, absence de sous-couches sous 1500/1600 m en versants S.

Qualité de la neige ce mardi :

5/15 cm de neige fraiche reposant sur une neige encore froide, dense, souple, sauf en versants S sous 2000 m où elle est déjà un peu croûtée. Neige soufflée dans les secteurs soumis à la Bise. Dure ou glacée près des crêtes.

Nombreuses corniches et accumulations/congères. Arêtes dures, longues portions en glace en haute-montagne.

## Aperçu météo pour le mardi 31 mars

| | nuit | matin | après-midi | soir |
|---|---|---|---|---|
| | | | | |

Dernières averses de neige en fin de nuit. Nuageux en matinée avec des éclaircies de plus en plus larges. Fort vent dès 2000 m.

| | | | | |
|---|---|---|---|---|
| **Pluie-Neige** | 600 m | | | |
| **Iso 0 °C** | 1 300 m | 1 100 m | 1 500 m | 1 100 m |
| **Vent 2000 m** | 70 km/h | 70 km/h | 60 km/h | 50 km/h |
| **Vent 4000 m** | 110 km/h | 110 km/h | 110 km/h | 100 km/h |

## Épaisseur de neige hors-piste

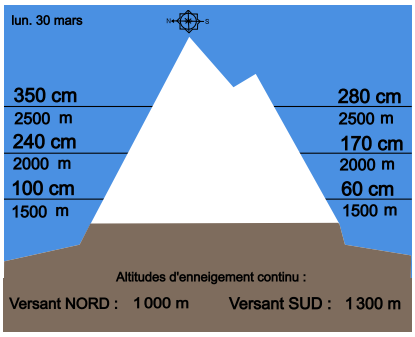


## Précipitations à 1800 m

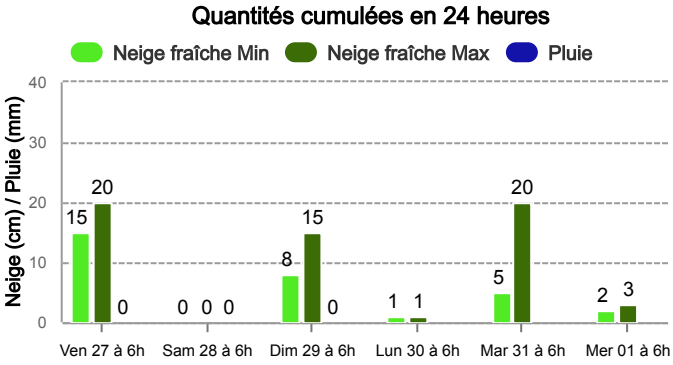


## Tendance du mercredi 01 avril

2

**Indice de risque limité**

Le soleil contribue à stabiliser les plaques, les plaques à vent restent sensibles en altitude.

Pour consulter la vigilance en cours, veuillez vous rendre sur le site https://vigilance.meteofrance.fr/fr

Météo-France - 73 avenue de Paris, 94165 Saint-Mandé cedex - Contact : contact@meteo.fr

Rédigé par Météo-France avec la contribution des observateurs du réseau nivo-météorologiques. Partenariat : ANMSM (Maires de Stations de Montagne), DSF (Domaines Skiables de France), ADSP (Directeurs de Pistes et de la Sécurité des Stations de Sports d'Hiver) et autres acteurs de la montagne.

Bulletin neige & avalanches par téléphone au

0 892 68 10 20 Service 0,35 € / min + prix appel

RÉPUBLIQUE FRANÇAISE
*Liberté Égalité Fraternité*

METEO FRANCE
À VOS CÔTÉS, DANS UN CLIMAT QUI CHANGE

# Bulletin d'estimation du risque d'avalanche

## (valable en dehors des pistes balisées et ouvertes)

# MASSIF : Mont-Blanc

Rédigé le lundi 30 mars 2026 à 16h

## Conditions nivo-météo des 7 derniers jours

| | mar. 24/03 | | | | mer. 25/03 | | | | jeu. 26/03 | | | | ven. 27/03 | | | | sam. 28/03 | | | | dim. 29/03 | | | | lun. 30/03 | | | |
|---|---|---|---|---|---|---|---|---|---|---|---|---|---|---|---|---|---|---|---|---|---|---|---|---|---|---|---|---|
| | 03h | 09h | 15h | 21h | 03h | 09h | 15h | 21h | 03h | 09h | 15h | 21h | 03h | 09h | 15h | 21h | 03h | 09h | 15h | 21h | 03h | 09h | 15h | 21h | 03h | 09h | 15h | 21h |
| Météo | | | | | | | | | | | | | | | | | | | | | | | | | | | | |
| Vent (km/h) | 40 | 25 | 20 | 15 | 25 | 90 | 110 | 90 | 90 | 90 | 90 | 80 | 60 | 80 | 50 | 70 | 60 | 50 | 30 | 40 | 50 | 40 | 50 | 70 | 80 | 80 | 80 | 110 |
| à 4000m | | | | | | | | | | | | | | | | | | | | | | | | | | | | |
| Vent (km/h) | 5 | 5 | 5 | 5 | 10 | 50 | 60 | 50 | 50 | 50 | 40 | 35 | 40 | 50 | 30 | 20 | 30 | 30 | 20 | 30 | 40 | 30 | 20 | 20 | 10 | 20 | 50 | 60 |
| à 2000m | | | | | | | | | | | | | | | | | | | | | | | | | | | | |

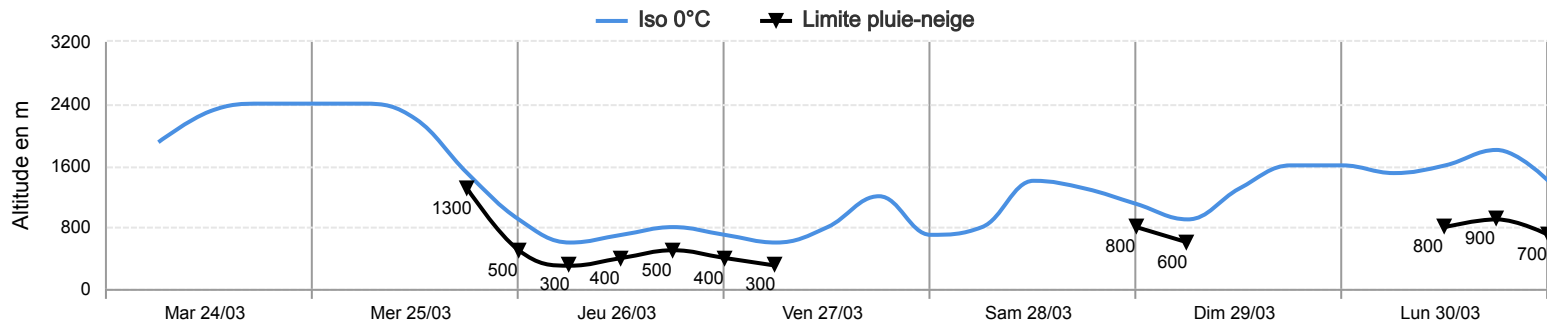


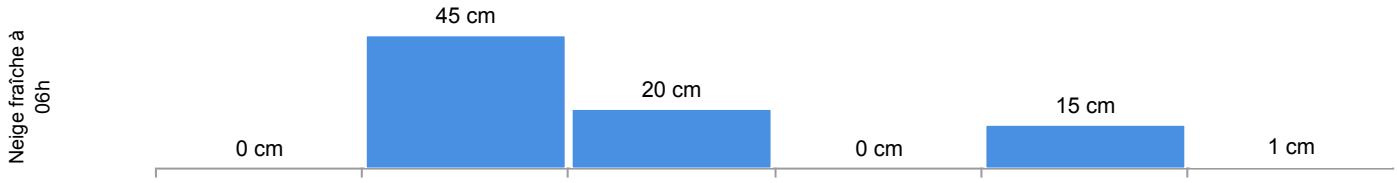


| Risque d'avalanche | mar. 24/03 | mer. 25/03 | jeu. 26/03 | ven. 27/03 | sam. 28/03 | dim. 29/03 | lun. 30/03 |
|---|---|---|---|---|---|---|---|
| | 2 | 3 | 4 | 4 | 3 | 2 | 2 |

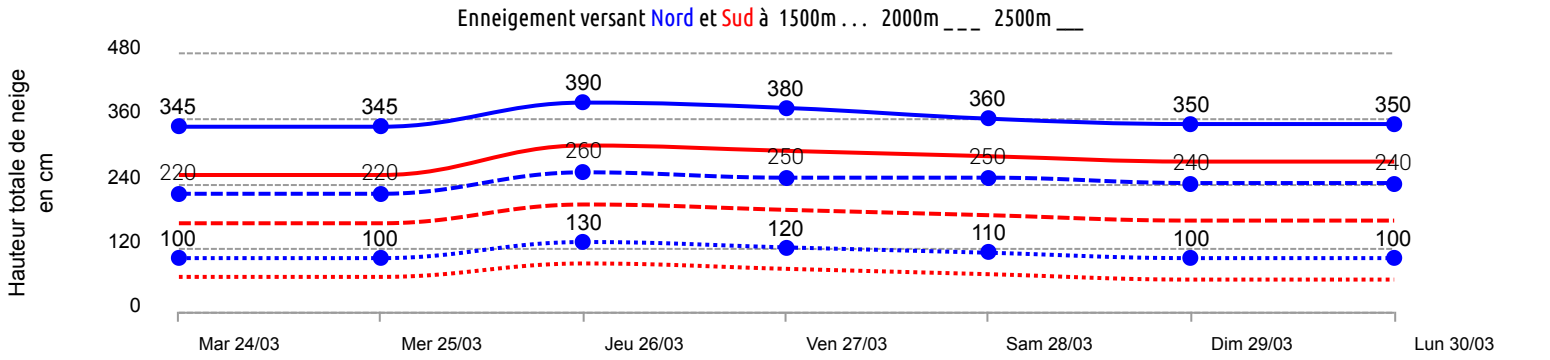


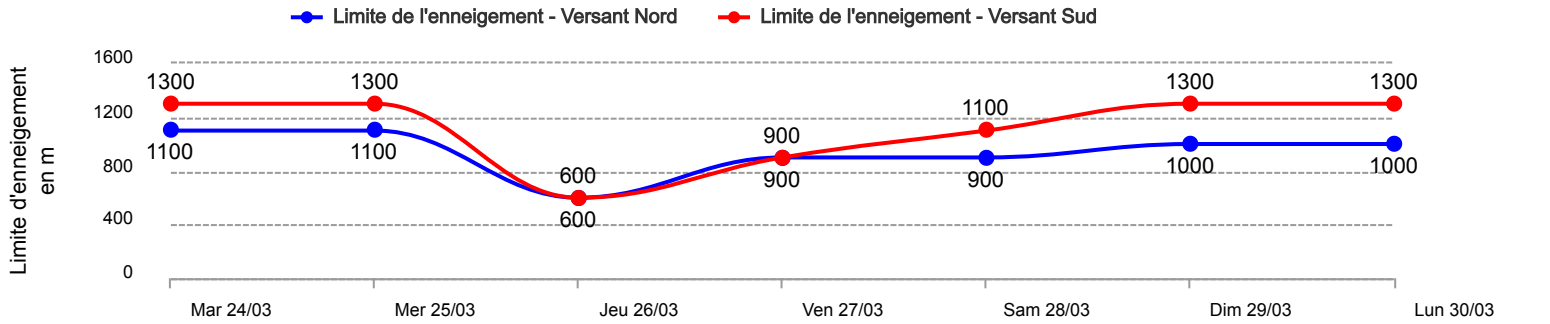


Pour consulter la vigilance en cours, veuillez vous rendre sur le site https://vigilance.meteofrance.fr/fr


Météo-France - 73 avenue de Paris, 94165 Saint-Mandé cedex - Contact : contact@meteo.fr


Bulletin neige & avalanches par téléphone au

0 892 68 10 20 Service 0,35 € / min + prix appel


Rédigé par Météo-France avec la contribution des observateurs du réseau nivo-météorologiques. Partenariat : ANMSM (Maires de Stations de Montagne), DSF (Domaines Skiables de France), ADSP (Directeurs de Pistes et de la Sécurité des Stations de Sports d'Hiver) et autres acteurs de la montagne.