# Bulletin d'estimation du risque d'avalanche
## (valable en dehors des pistes balisées et ouvertes)

# MASSIF : Pelvoux

Rédigé le lundi 30 mars 2026 à 16h

## Estimation des risques pour le : MARDI 31 MARS

**PLAQUES A VENT DANS LA NEIGE VENTÉE**

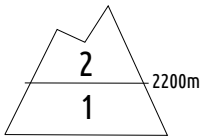


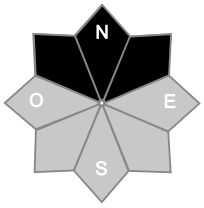


Au-dessus de 2200m indice de risque limité, plus bas indice faible.

**Départs spontanés :** une plaque surchargée par le vent peut céder spontanément. Taille limitée.

**Déclenchements provoqués :** instabilités dans la neige ventée, plus épaisses en bordure de l'Oisans.

Indices de risque : 5 très fort - 4 fort - 3 marqué - 2 limité - 1 faible -- En noir : les pentes les plus dangereuses

## Stabilité du manteau neigeux

**Situation avalancheuse typique :** neige ventée

**Déclenchements provoqués :** plaques en place dans la neige ventée, d'autres en formation sous l'action d'un fort vent de nord là où il reste encore de la neige légère et transportable. Présentes en toutes orientations au-dessus de 2000/2200 m environ, elles sont néanmoins plus nombreuses et sensibles dans les orientations d'un large secteur nord (nord-ouest, nord et nord-est) ainsi que vers l'Oisans où les quantités de neige fraîche sont un peu plus importantes. Facilement déclenchables par le passage d'un skieur, ces instabilités génèrent des avalanches de taille petite (taille 1), voire moyenne (taille 2), notamment vers Écrins/Agneaux/Combeynots.

**Départs spontanés :** rares ruptures par surcharge du au vent (rupture de corniche par exemple). Avalanche petite à moyenne (taille 1 à 2).

## Qualité de la neige

**L'enneigement** est proche des normales ou excédentaire pour une fin mars.
Hauteurs de neige observées : 295 cm à la Nivôse des Écrins vers 3000 m, 189 cm au Pré de Mme Carle à 1900 m.

**Limite d'enneigement skiable** : dès 1400 m en ubacs favorables (terrains herbeux, pistes forestières), 1800/1900 m en adrets pas trop raides.

**État de la neige de surface** : neige récente fortement travaillée par le vent, mais localement encore légère dans les secteurs bien abrités. Sur les crêtes, d'épaisses corniches côtoient des zones pelées par le vent.
En versant sud, neige croutée sous 2500 m.

## Aperçu météo pour le mardi 31 mars

| nuit | matin | après-midi | soir |
|---|---|---|---|

Temps froid, sec et venté. 0° à 2000 m et -9° à 3000 m.

| Pluie-Neige | | | | |
|---|---|---|---|---|
| Iso 0 °C | 1 500 m | 1 200 m | 1 800 m | 1 400 m |
| Vent 2000 m | 70 km/h | 55 km/h | 45 km/h | 45 km/h |
| Vent 3000 m | 90 km/h | 80 km/h | 60 km/h | 60 km/h |

## Épaisseur de neige hors-piste

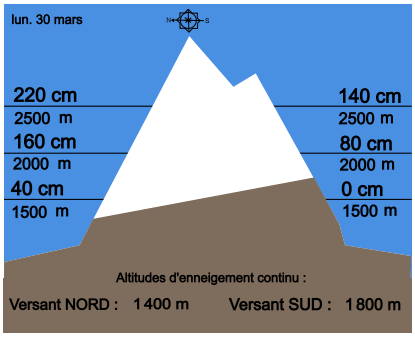


## Précipitations à 1800 m

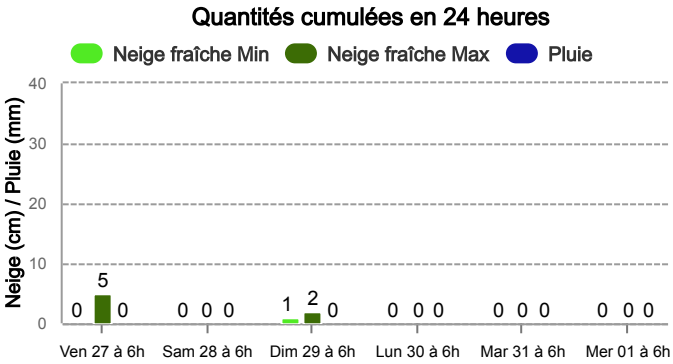


## Tendance du mercredi 01 avril

**Indice de risque limité**

Maintien d'un risque limité. Le vent de nord à nord-est modéré continue de durcir le manteau neigeux.

Pour consulter la vigilance en cours, veuillez vous rendre sur le site https://vigilance.meteofrance.fr/fr

Météo-France - 73 avenue de Paris, 94165 Saint-Mandé cedex - Contact : contact@meteo.fr

Rédigé par Météo-France avec la contribution des observateurs du réseau nivo-météorologiques. Partenariat : ANMSM (Maires de Stations de Montagne), DSF (Domaines Skiables de France), ADSP (Directeurs de Pistes et de la Sécurité des Stations de Sports d'Hiver) et autres acteurs de la montagne.

Bulletin neige & avalanches par téléphone au
0 892 68 10 20 Service 0,35 € / min + prix appel

RÉPUBLIQUE FRANÇAISE
*Liberté Égalité Fraternité*

METEO FRANCE
À VOS CÔTÉS, DANS UN CLIMAT QUI CHANGE

# Bulletin d'estimation du risque d'avalanche

## (valable en dehors des pistes balisées et ouvertes)

# MASSIF : Pelvoux

Rédigé le lundi 30 mars 2026 à 16h

## Conditions nivo-météo des 7 derniers jours

| | mar. 24/03 | | | | mer. 25/03 | | | | jeu. 26/03 | | | | ven. 27/03 | | | | sam. 28/03 | | | | dim. 29/03 | | | | lun. 30/03 | | | |
|---|---|---|---|---|---|---|---|---|---|---|---|---|---|---|---|---|---|---|---|---|---|---|---|---|---|---|---|---|
| | 03h | 09h | 15h | 21h | 03h | 09h | 15h | 21h | 03h | 09h | 15h | 21h | 03h | 09h | 15h | 21h | 03h | 09h | 15h | 21h | 03h | 09h | 15h | 21h | 03h | 09h | 15h | 21h |
| Météo | | | | | | | | | | | | | | | | | | | | | | | | | | | | |
| Vent (km/h) | 15 | 10 | 10 | 10 | 25 | 50 | 80 | 85 | 90 | 95 | 90 | 80 | 70 | 40 | 10 | 10 | 20 | 25 | 30 | 35 | 30 | 20 | 20 | 20 | 30 | 50 | 90 | 100 |
| à 3000m | | | | | | | | | | | | | | | | | | | | | | | | | | | | |
| Vent (km/h) | 10 | 10 | 10 | 5 | 10 | 20 | 55 | 70 | 70 | 70 | 70 | 70 | 70 | 40 | 10 | 5 | 15 | 25 | 30 | 30 | 30 | 20 | 25 | 20 | 30 | 40 | 60 | 80 |
| à 2000m | | | | | | | | | | | | | | | | | | | | | | | | | | | | |

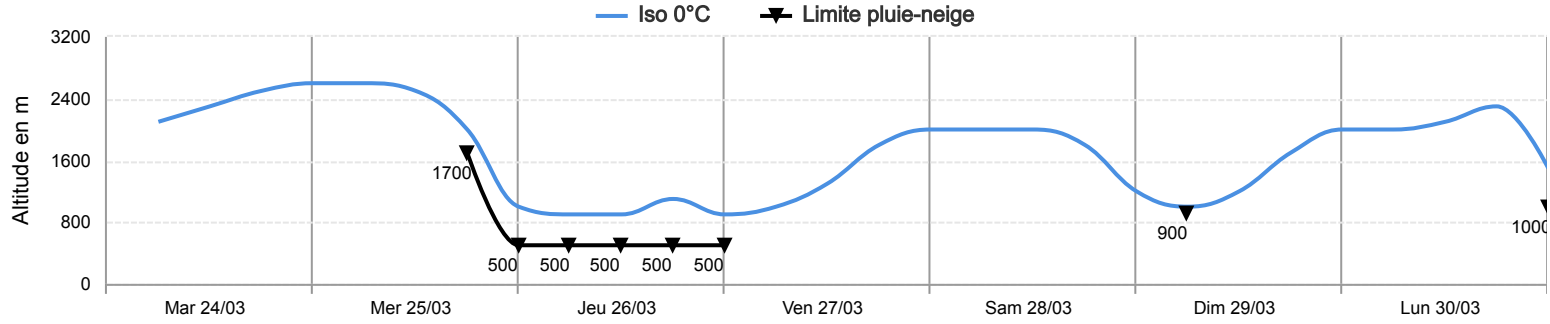


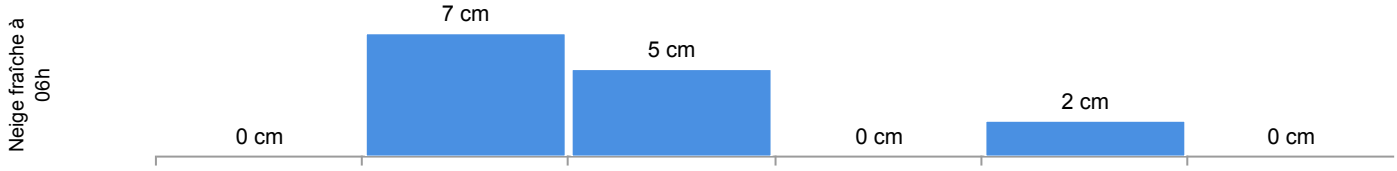


| Risque d'avalanche | mar. 24/03 | mer. 25/03 | jeu. 26/03 | ven. 27/03 | sam. 28/03 | dim. 29/03 | lun. 30/03 |
|---|---|---|---|---|---|---|---|
| | 2 | 2 | 3 | 3 | 2 | 2 | 2 |

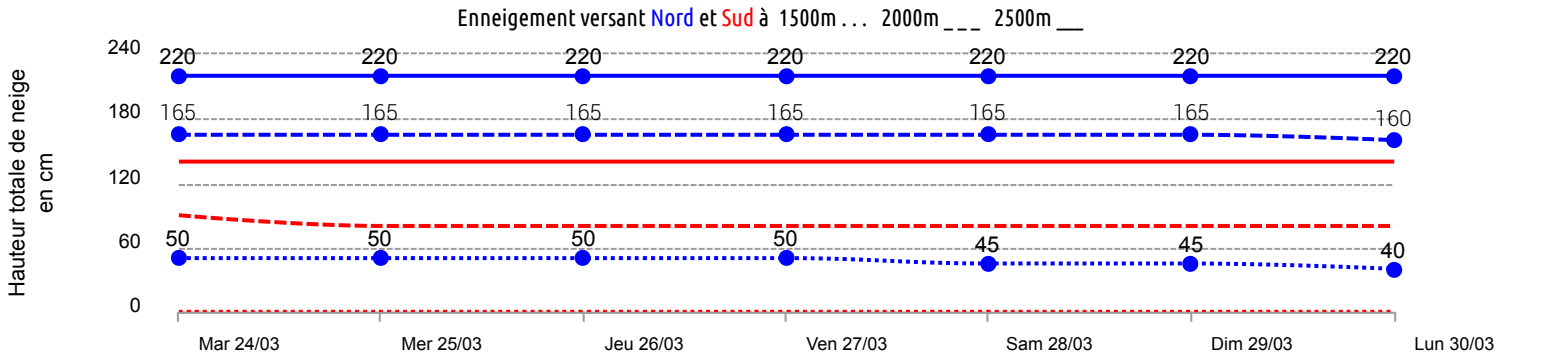


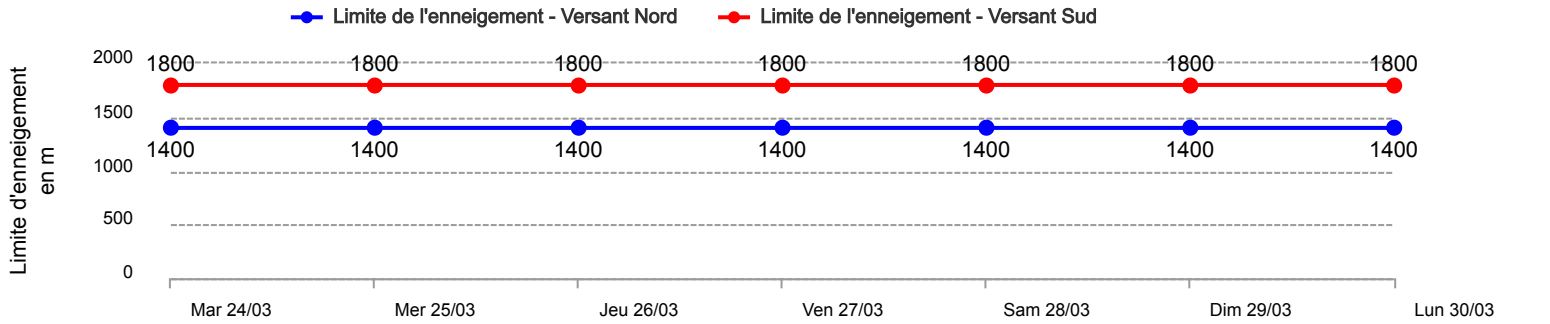


Pour consulter la vigilance en cours, veuillez vous rendre sur le site https://vigilance.meteofrance.fr/fr


Météo-France - 73 avenue de Paris, 94165 Saint-Mandé cedex - Contact : contact@meteo.fr



Rédigé par Météo-France avec la contribution des observateurs du réseau nivo-météorologiques. Partenariat : ANMSM (Maires de Stations de Montagne), DSF (Domaines Skiables de France), ADSP (Directeurs de Pistes et de la Sécurité des Stations de Sports d'Hiver) et autres acteurs de la montagne.



Bulletin neige & avalanches par téléphone au
0 892 68 10 20 Service 0,35 € / min + prix appel