Bulletin d'estimation du risque d'avalanche
(valable en dehors des pistes balisées et ouvertes)

MASSIF : Ubaye

Rédigé le lundi 30 mars 2026 à 16h

Estimation des risques pour le : MARDI 31 MARS

QUELQUES INSTABILITÉS EN ALTITUDE DANS LA NEIGE VENTÉE

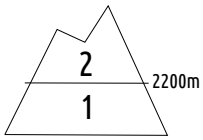

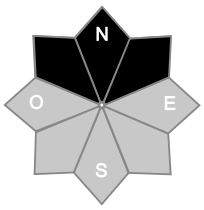

Au-dessus de 2200m indice de risque limité, plus bas indice faible.

Départs spontanés : rares et à haute altitude, en neige ventée

Déclenchements provoqués : quelques instabilités de surface dans la neige ventée.

Indices de risque : 5 très fort - 4 fort - 3 marqué - 2 limité - 1 faible -- En noir : les pentes les plus dangereuses

Stabilité du manteau neigeux

Situation avalancheuse typique : neige ventée

Déclenchements provoqués : instabilités limitées à de quelques pentes d'altitude dans la neige récente ventée. Généralement en neige dure bien identifiable, ces plaques sont possibles surtout en large orientation nord au-dessus de 2000/2200 m environ, plutôt à distance des crêtes. Départs possibles au passage d'un seul skieur et générant des avalanches de petite taille, parfois moyenne.

Départs spontanés : rares et restants peu volumineux dans les secteurs d'accumulation par le vent en altitude. Taille petite, plus rarement moyenne.

Qualité de la neige

Enneigement proche des normales.
Hauteurs de neige observées : 75 cm à la Nivôse de Restefond à 2550 m, 86 vers le col de Larche à 2270 m

Enneigement skiable : vers 1600 m en ubacs, 2000/2100 m en adrets peu pentus.

État de la neige en surface : manteau neigeux souvent dur/regelé en adrets, durcis par le vent en ubacs d'altitude. On retrouve localement un peu de neige légère en surface dans les combes nord bien abritées du vent. Pas ou peu d'humidification au soleil en journée.

Aperçu météo pour le mardi 31 mars

	nuit	matin	après-midi	soir

Temps sec avec quelques cumulus vers l'italie le matin, se généralisant l'après-midi.

Pluie-Neige				
Iso 0 °C	1 700 m	1 400 m	1 900 m	1 700 m
Vent 2000 m	↓ 50 km/h	↓ 35 km/h	↓ 35 km/h	↙ 35 km/h
Vent 3000 m	↓ 65 km/h	↙ 50 km/h	↙ 50 km/h	↙ 50 km/h

Épaisseur de neige hors-piste

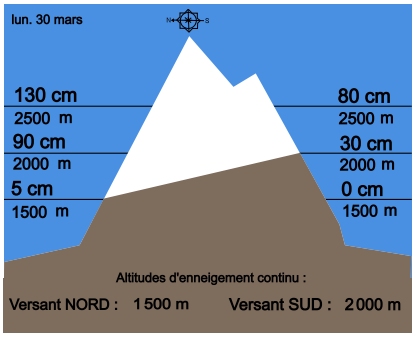

Précipitations à 1800 m

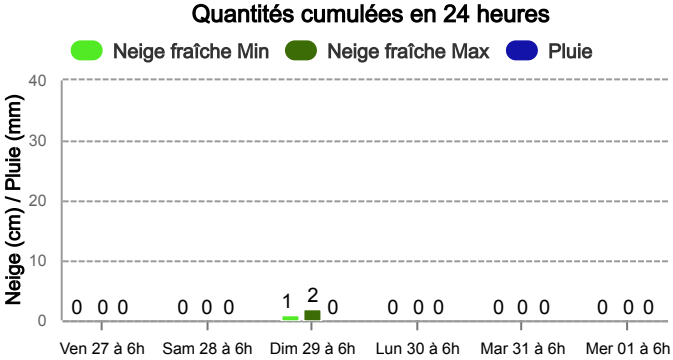

Tendance du mercredi 01 avril

Indice de risque limité

Peu d'évolution de la situation nivologique. De rares instabilités persistent en altitude dans la neige ventée.

Pour consulter la vigilance en cours, veuillez vous rendre sur le site https://vigilance.meteofrance.fr/fr

Météo-France - 73 avenue de Paris, 94165 Saint-Mandé cedex - Contact : contact@meteo.fr

Rédigé par Météo-France avec la contribution des observateurs du réseau nivo-météorologiques. Partenariat : ANMSM (Maires de Stations de Montagne), DSF (Domaines Skiables de France), ADSP (Directeurs de Pistes et de la Sécurité des Stations de Sports d'Hiver) et autres acteurs de la montagne.

Bulletin neige & avalanches par téléphone au
0 892 68 10 20 Service 0,35 € / min + prix appel

RÉPUBLIQUE FRANÇAISE
Liberté Égalité Fraternité

METEO FRANCE
À VOS CÔTÉS, DANS UN CLIMAT QUI CHANGE

Bulletin d'estimation du risque d'avalanche

(valable en dehors des pistes balisées et ouvertes)

MASSIF : Ubaye

Rédigé le lundi 30 mars 2026 à 16h

Conditions nivo-météo des 7 derniers jours

	mar. 24/03				mer. 25/03				jeu. 26/03				ven. 27/03				sam. 28/03				dim. 29/03				lun. 30/03			
	03h	09h	15h	21h	03h	09h	15h	21h	03h	09h	15h	21h	03h	09h	15h	21h	03h	09h	15h	21h	03h	09h	15h	21h	03h	09h	15h	21h
Météo																												
Vent (km/h)	15	10	15	20	25	40	70	100	100	80	70	60	60	50	40	30	25	25	25	25	30	40	30	15	30	50	75	120
à 3000m																												
Vent (km/h)	5	5	5	5	10	20	50	80	80	60	50	50	45	35	20	10	10	10	20	15	20	40	25	15	10	25	45	80
à 2000m																												

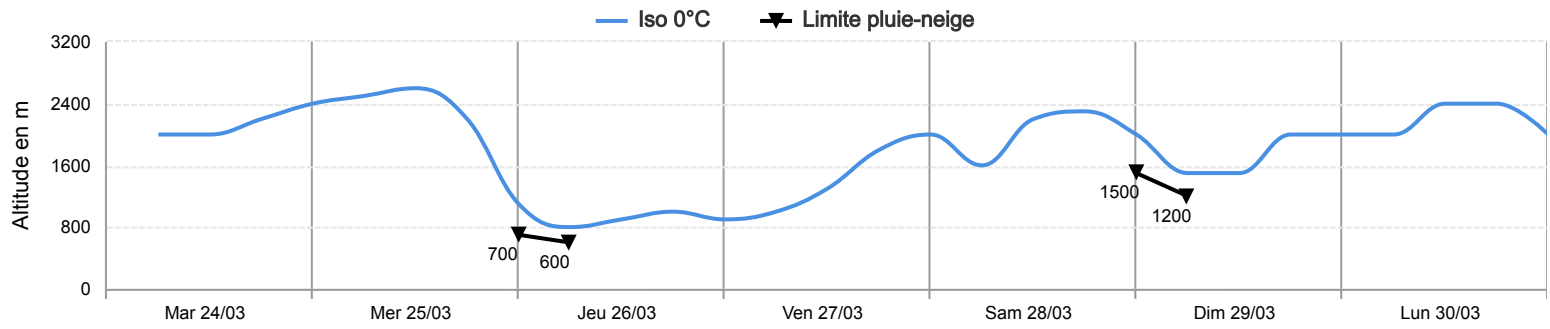

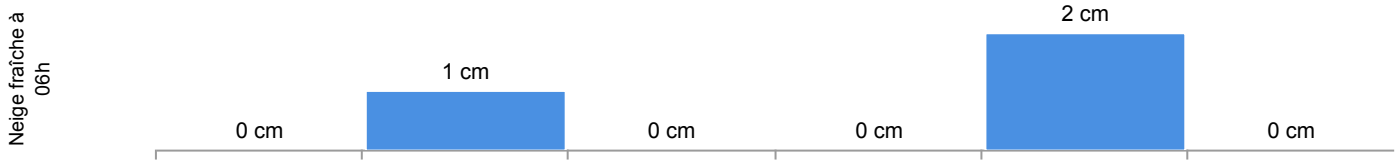

Risque d'avalanche	mar. 24/03	mer. 25/03	jeu. 26/03	ven. 27/03	sam. 28/03	dim. 29/03	lun. 30/03
	2	2	3	2	2	2	2

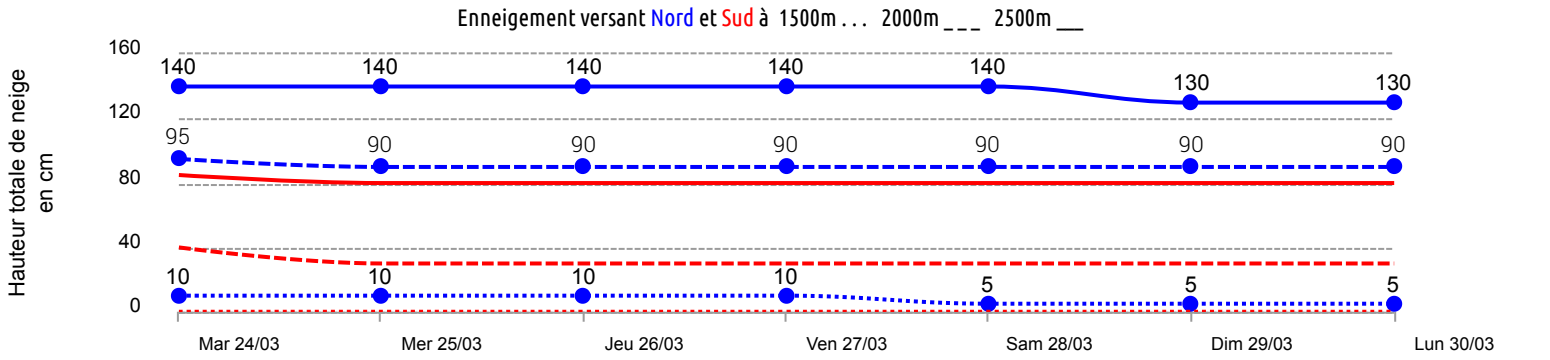

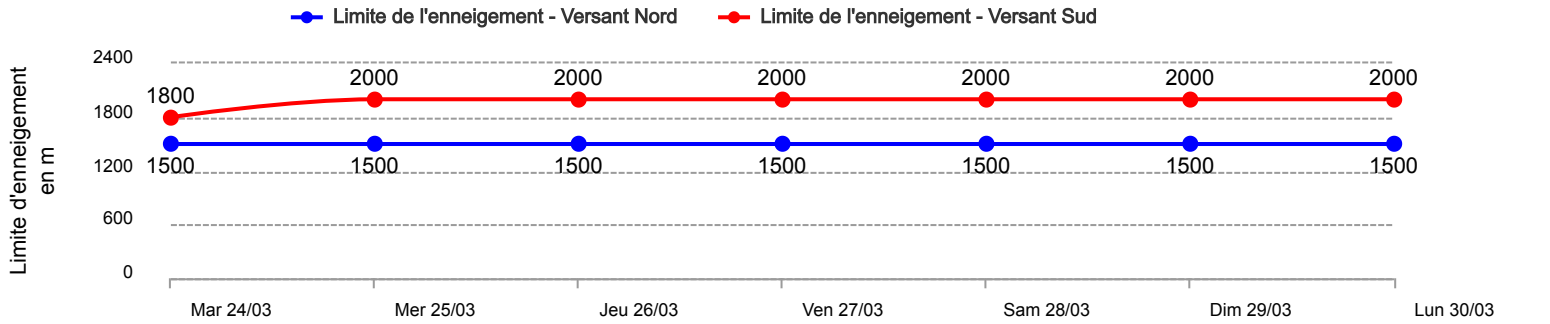

Pour consulter la vigilance en cours, veuillez vous rendre sur le site https://vigilance.meteofrance.fr/fr

Météo-France - 73 avenue de Paris, 94165 Saint-Mandé cedex - Contact : contact@meteo.fr

Rédigé par Météo-France avec la contribution des observateurs du réseau nivo-météorologiques. Partenariat : ANMSM (Maires de Stations de Montagne), DSF (Domaines Skiables de France), ADSP (Directeurs de Pistes et de la Sécurité des Stations de Sports d'Hiver) et autres acteurs de la montagne.

Bulletin neige & avalanches par téléphone au

0 892 68 10 20 Service 0,35 € / min + prix appel