Bulletin d'estimation du risque d'avalanche

(valable en dehors des pistes balisées et ouvertes)

MASSIF : Vanoise

Rédigé le lundi 30 mars 2026 à 16h

Estimation des risques pour le : MARDI 31 MARS

L'HIVER FAIT DE LA RÉSISTANCE AVEC DU VENT FORT EN ALTITUDE, DU FROID POUR LA SAISON ET QUELQUES CHUTES DE NEIGE ATTENDUES DANS LA NUIT DE LUNDI À MARDI. NOUVELLES PLAQUES EN FORMATION DANS CES CONDITIONS.

3

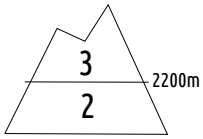

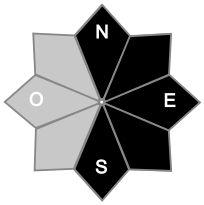

Au-dessus de 2200m indice de risque marqué, plus bas indice limité.

Départs spontanés : Peu probable

Déclenchements provoqués : Nouvelles plaques en formation dans la neige fraiche

Indices de risque : 5 très fort - 4 fort - 3 marqué - 2 limité - 1 faible -- En noir : les pentes les plus dangereuses

Stabilité du manteau neigeux

Situation avalancheuse typique : neige fraîche neige ventée

Déclenchements provoqués : Quelques nouvelles plaques en formation avec la neige fraiche ventée attendue ce lundi soir. Avec 10/15 cm attendu au mieux à l'ouest et sud du massif, ces nouvelles plaques ne devraient pas être bien épaisses en général mais attention toutefois aux zones d'accumulations sous le vent . Vent de Nord qui va d'ailleurs continuer de souffler demain mardi sur les crêtes faisant peu à peu grossir ces nouvelles plaques. Ce mardi elles seront temporairement sensible au passage d'un skieur, généralement peu étendu avec cassure de 30 à 50 cm possible. taille 1 à 2. Elles seront présentes surtout au dessus de 2200m (limite haute des arbres) et plus fréquentes en Est et Sud souvent loin des crêtes qui sont elles souvent décapés par le vent. On pourra aussi en trouver quelques unes en nord derrière une rupture de pente là aussi loin des crêtes.

Départs spontanés : Peu probable, à part quelques petites purges de neige fraiche s'humidifiant au soleil dans les rares pentes ouest raides qui verront suffisamment de soleil pour chauffer en fin de journée. Escargots, boulettes partant sous les rochers et au plus une taille 1.

Qualité de la neige

Enneigement : Encore un peu au dessus de la moyenne grâce à cette petite séquence hivernale retardant depuis quelques jours l'inéluctable fonte printanière.

Limite skiable : vers 1200/1300 m en Nord, 1600 m en Sud.

Qualité de la neige : neige poudreuse à l'abri du vent donc essentiellement à basse altitude dans les zones boisées ou au moins avec quelques arbres isolés. Au dessus de la ligne des arbres neige le plus souvent cartonnée à durcie par le vent, aspect poudreux à l'abri du vent seulement.

Crêtes et cols en neige ventée très dure, ou en glace notamment en Lauzière suite petit épisode de pluie verglaçante de ce lundi après midi.

Aperçu météo pour le mardi 31 mars

	nuit	matin	après-midi	soir

Neige faible la nuit. Encore bien bouché avec brouillard en montagne une bonne partie de la matinée; éclaircies l'après midi. Vent Nord fort en crête.

Pluie-Neige	800 m			
Iso 0 °C	1 400 m	1 200 m	1 600 m	1 200 m
Vent 2500 m	↘ 50 km/h	↘ 25 km/h	↘ 30 km/h	↓ 30 km/h
Vent 3500 m	↓ 60 km/h	↙ 55 km/h	↙ 60 km/h	↙ 55 km/h

Épaisseur de neige hors-piste

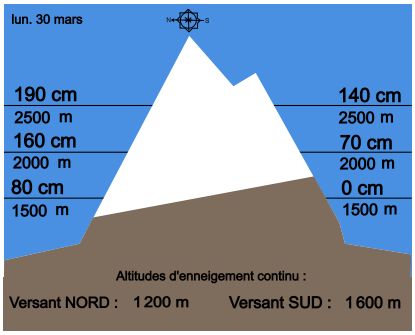

Précipitations à 1800 m

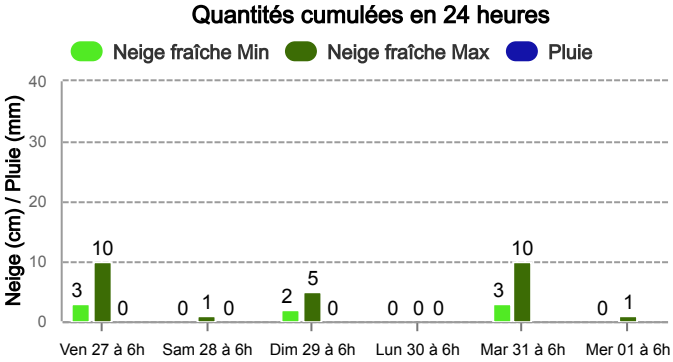

Tendance du mercredi 01 avril

Indice de risque limité

Retour du soleil, stabilisation rapide des quelques plaques formées ce lundi et mardi. Humidification de surface au soleil même si l'air reste encore frais pour la saison.

Pour consulter la vigilance en cours, veuillez vous rendre sur le site https://vigilance.meteofrance.fr/fr

Météo-France - 73 avenue de Paris, 94165 Saint-Mandé cedex - Contact : contact@meteo.fr

Rédigé par Météo-France avec la contribution des observateurs du réseau nivo-météorologiques. Partenariat : ANMSM (Maires de Stations de Montagne), DSF (Domaines Skiables de France), ADSP (Directeurs de Pistes et de la Sécurité des Stations de Sports d'Hiver) et autres acteurs de la montagne.

Bulletin neige & avalanches par téléphone au 0 892 68 10 20 Service 0,35 € / min + prix appel

RÉPUBLIQUE FRANÇAISE
Liberté Égalité Fraternité

METEO FRANCE
À VOS CÔTÉS, DANS UN CLIMAT QUI CHANGE

Bulletin d'estimation du risque d'avalanche

(valable en dehors des pistes balisées et ouvertes)

MASSIF : Vanoise

Rédigé le lundi 30 mars 2026 à 16h

Conditions nivo-météo des 7 derniers jours

	mar. 24/03				mer. 25/03				jeu. 26/03				ven. 27/03				sam. 28/03				dim. 29/03				lun. 30/03			
	03h	09h	15h	21h	03h	09h	15h	21h	03h	09h	15h	21h	03h	09h	15h	21h	03h	09h	15h	21h	03h	09h	15h	21h	03h	09h	15h	21h
Météo																												
Vent (km/h)	20	25	20	20	40	60	85	85	70	65	70	60	55	40	30	20	30	40	40	30	30	30	30	30	45	55	75	85
à 3500m																												
Vent (km/h)	10	10	10	10	30	45	70	70	60	55	60	50	45	30	20	10	20	30	30	20	20	20	20	20	15	25	50	50
à 2500m																												

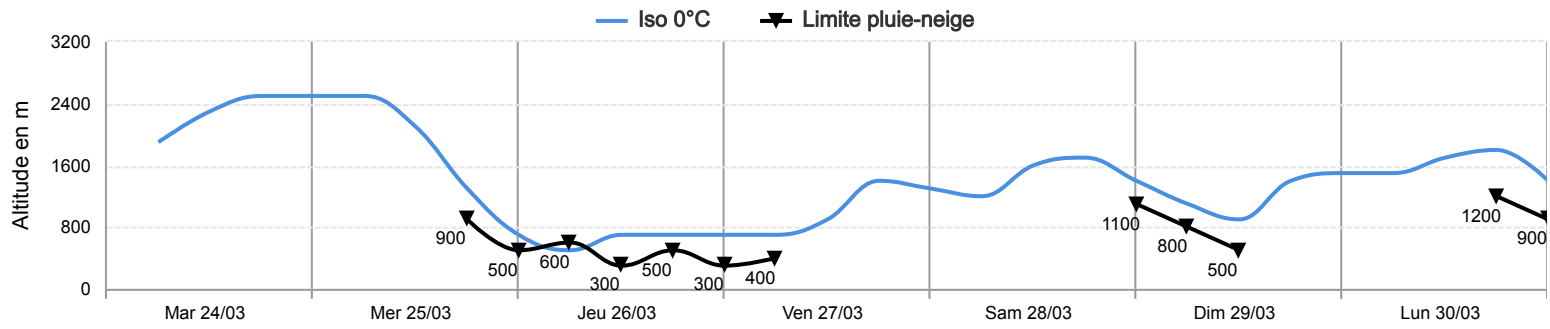

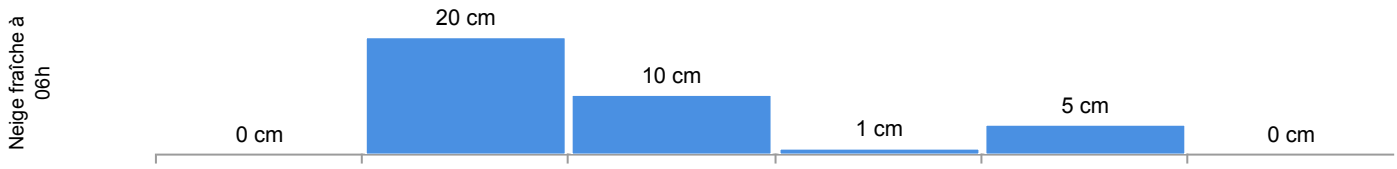

Risque d'avalanche	mar. 24/03	mer. 25/03	jeu. 26/03	ven. 27/03	sam. 28/03	dim. 29/03	lun. 30/03
	2	3	3	3	2	2	2

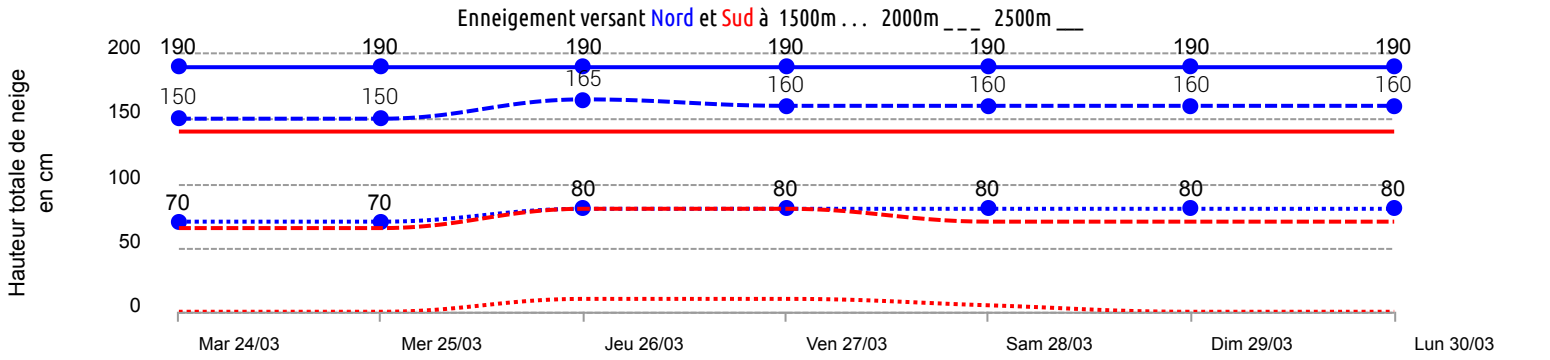

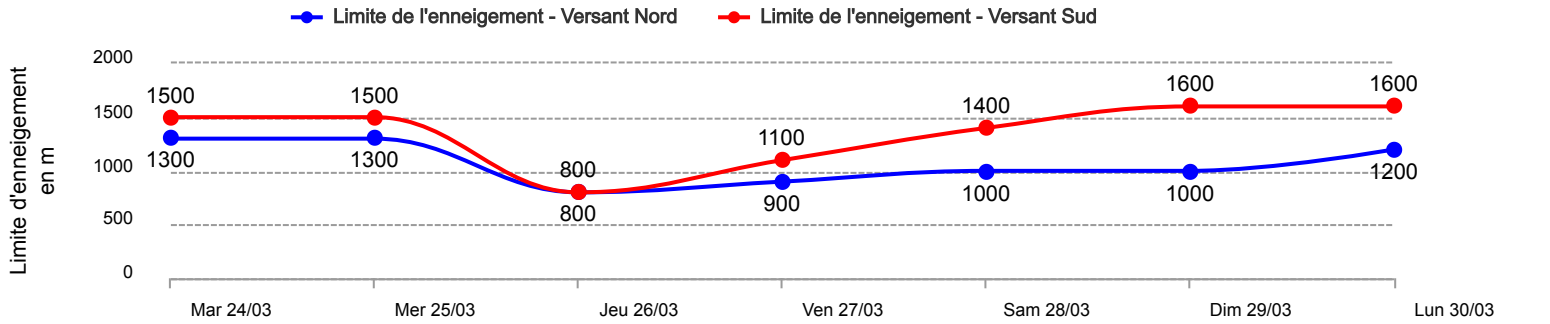

Pour consulter la vigilance en cours, veuillez vous rendre sur le site https://vigilance.meteofrance.fr/fr

Météo-France - 73 avenue de Paris, 94165 Saint-Mandé cedex - Contact : contact@meteo.fr

Rédigé par Météo-France avec la contribution des observateurs du réseau nivo-météorologiques. Partenariat : ANMSM (Maires de Stations de Montagne), DSF (Domaines Skiables de France), ADSP (Directeurs de Pistes et de la Sécurité des Stations de Sports d'Hiver) et autres acteurs de la montagne.

Bulletin neige & avalanches par téléphone au

0 892 68 10 20 Service 0,35 € / min + prix appel